	MARINHA DO BRASIL CAPITANIA FLUVIAL DA AMAZÔNIA OCIDENTAL	NPCF-CFAOC OSTENSIVO

NORMAS E PROCEDIMENTOS DA CAPITANIA FLUVIAL DA AMAZÔNIA OCIDENTAL

1ª Mod

2024

NORMAS E PROCEDIMENTOS DA CAPITANIA FLUVIAL DA AMAZÔNIA OCIDENTAL

MARINHA DO BRASIL

CAPITANIA FLUVIAL DA AMAZÔNIA OCIDENTAL

2024

TIPO: NORMA

FINALIDADE: NORMATIVA

FOLHA DE REGISTRO DE MODIFICAÇÕES

NÚMERO DA MODIFICAÇÃO	PORTARIA	PÁGINAS AFETADAS	DATA DA ALTERAÇÃO
Mod. 1	163/CFAOC	-	09/09/2024

ÍNDICE

Folha de Rosto		II
Registro de Modificações		III
Índice		IV - XIII
Introdução		XIII
CAPÍTULO 1	**- ÁREAS DE JURISDIÇÃO**	1-167
SEÇÃO I	**- ORGANIZAÇÃO, JURISDIÇÃO E LIMITES**	1-167
1.1	- Organização e Jurisdição	1-167
1.2	- Capitania Fluvial da Amazônia Ocidental (CFAOC)	1-167
1.3	- Agência Fluvial de Eirunepé (AgEirunepé)	3-167
1.4	- Agência Fluvial de Itacoatiara (AgItacoatiara)	4-167
1.5	- Agência Fluvial de Parintins(AgParintins)	5-167
1.6	- Agência Fluvial de Tefé (AgTefé)	6-167
1.7	- Agência Fluvial de Caracaraí (AgCaracaraí)	7-167
1.8	- Atendimento ao Público	8-167
1.8.1	- Descrição dos Serviços	8-167
1.9	- Acompanhamento de Processos	9-167
1.10	- Vistoria de Embarcações	9-167
1.11	- Carta de Serviço ao Usuário	10-167
1.12	- Denúncias e Sugestões	10-167
1.13	- Limites para Navegação Interior	10-167
1.14	- Navegação no Quadro	11-167
SEÇÃO II	**-CARATERÍSTICAS PRINCIPAIS DOS PORTOS E SUAS ADMINISTRAÇÕES**	12-167
1.16	-Terminais Localizados na Área de Jurisdição da CFAOC e Agências	12-167
1.16.1	**-Terminais Privado**	12-167
1.16.1.1	- Terminal Hidroviário do AJATO	12-167
1.161.2	-Terminal de Uso Privativo CHIBATÃO1-15	13-167
1.16.1.3	-Terminal de Uso Privativo SUPERTERMINAIS	13-167
1.16.1.4	-Terminal de Uso Privativo da Moageira (TRIGOLAR)	13-167
1.16.1.5	-Terminais Aquaviário de Manaus (TA–MANAUS-REAM)	13-167
1.16.1.6	-Terminais Aquaviário de Manaus (ATEM)	13-167
1.16.1.7	-Terminal Aquaviário de COARI (TA-COARI-TRANSPETRO)	13-167
1.16.1.8	-Terminal de Uso Privativo CIMENTO VENCEMOS	13-167
1.16.1.9	-Terminal Hidroviário de CARAUARI	13-167
1.16.1.10	-Terminal Hidroviário de JOÃO DE DEUS	13-167
1.16.1.11	-Terminal Hidroviário de DEMÉTRIO	13-167
1.16.1.12	-Terminal Hidroviário de SÃO RAIMUNDO	13-167
1.16.2	**-Terminais Públicos**	13-167
1.16.2.1	-Porto Público de Manaus (Cais das Torres e Terminal Roadway)	13-167
1.16.2.2	-Terminal de Pequeno Porte (IP4) Manacapuru	13-167
1.16.2.3	-Terminal de Pequeno Porte (IP4) Tapauá	13-167

1.16.2.4	-Terminal de Pequeno Porte (IP4) Beruri	13-167
1.16.2.5	-Terminal de Pequeno Porte (IP4) Anori	13-167
1.16.2.6	-Terminal de Pequeno Porte (IP4) Santa Isabel Rio Negro	13-167
1.16.2.7	-Terminal de Pequeno Porte (IP4) Novo Airão	13-167
1.16.2.8	-Terminal de Pequeno Porte (IP4) Barcelos	13-167
1.16.2.9	-Terminal de Pequeno Porte (IP4) Cacau Pirêra	13-167
1.16.2.10	-Terminal de Pequeno Porte (IP4) Caapiranga	13-167
1.16.2.11	-Terminal de Pequeno Porte (IP4) Manaquiri	13-167
1.16.2.12	-Terminal de Pequeno Porte (IP4) Careiro da Várzea	13-167
1.16.2.13	-Terminal de Pequeno Porte (IP4) Coari	13-167
1.16.2.14	-Terminal de Pequeno Porte (IP4) Codajás	13-167
1.162.15	-Terminal de Pequeno Porte (IP4) Iranduba	13-167
1.17	**AGÊNCIA FLUVIAL DE ITACOATIARA**	14-167
1.17.1	**-Terminais Privados**	14-167
1.17.1.1	-TUP Graneleiro da HERMASA	14-167
1.17.1.2	-TUP TERMINAIS FLUVIAIS DO BRASIL (TFB)	14-167
1.17.1.3	-TUP Graneleiro MAQUIRA	14-167
1.17.1.4	-TUP Porto de Novo Remanso	14-167
1.17.2	**-Terminais Públicos**	14-167
1.17.2.1	-Terminal de Pequeno Porte (IP4) de MAUÉS	14-167
1.17.2.2	-Terminal de Pequeno Porte (IP4) de ITAPIRANGA	14-167
1.17.2.3	-Terminal de Pequeno Porte (IP4) de BORBA	14-167
1.17.2.4	-Terminal de Pequeno Porte (IP4) de NOVA OLINDA DO NORTE	14-167
1.17.2.5	-Terminal de Pequeno Porte (IP4) de ITACOATIARA	14-167
1.17.2.6	-Terminal de Pequeno Porte (IP4) de ITACOATIARA PORTO NOVO	14-167
1.17.2.7	-Terminal de Pequeno Porte (IP4) de URUCARÁ	14-167
1.17.2.8	-Terminal de Pequeno Porte (IP4) de SILVES	14-167
1.17.2.9	-Terminal de Pequeno Porte (IP4) de URUCURITUBA	14-167
1.17.2.10	-Terminal de Pequeno Porte (IP4) de Autazes	14-167
1.18	**AGÊNCIA FLUVIAL DE EIRUNEPÉ**	14-167
1.18.1	-Terminal de Pequeno Porte (IP4) de EIRUNEPÉ	14-167
1.18.2	-Terminal de Pequeno Porte (IP4) de ENVIRA	14-167
1.18.3	-Terminal de pequeno Porte (IP4) de Itamarati	14-167
1.19	**AGÊNCIA FLUVIAL DE PARINTINS**	14-167
1.19.1	-Terminal de Pequeno Porte (IP4) de PARINTINS	14-167
1.19.2	-Terminal de Pequeno Porte (IP4) de VILA AMAZÔNIA	14-167

1.19.3	-Terminal de Pequeno Porte (IP4) de NHAMUNDÁ	14-167
1.19.4	-Terminal de Pequeno Porte (IP4) de BOA VISTA DO RAMOS	14-167
1.20	**AGÊNCIA FLUVIAL DE TEFÉ**	15-167
1.20.1	-Terminal de Pequeno Porte (IP4) de ALVARÃES	14-167
1.20.2	-Terminal de Pequeno Porte (IP4) de FONTE BOA	14-167
1.20.3	-Terminal de Pequeno Porte (IP4) de JAPURÁ	14-167
1.20.4	-Terminal de Pequeno Porte (IP4) de JURUÁ	14-167
1.20.5	-Terminal de Pequeno Porte (IP4) de MARAÃ	15-167
1.20.6	-Terminal de Pequeno Porte (IP4) de UARINI	15-167
1.20.7	-Terminal de Pequeno Porte (IP4) de TEFÉ	15-167
1.21	**AGÊNCIA FLUVIAL DE CARACARAÍ**	15-167
1.21.1	-Terminal de Pequeno Porte (IP4) de CARACARAÍ	15-167
1.22	**-Documentações previstas para Obras e atividades afins em Águas sob Jurisdição Brasileira**	15-167
CAPÍTULO 2	**- FATOS E ACIDENTES DA NAVEGAÇÃO**	16-167
2.1	- Aplicação	17-167
2.2	- Acidentes e Fatos da Navegação	17-167
2.3	- Situações não Tipificadas como Acidentes ou Fato da Navegação	18-167
2.4	- Competência para Instauração de IAFN	18-167
2.5	- Prazo Referentes aos IAFN	19-167
2.5.1	- Prazo para Instauração	19-167
2.5.2	- Prazo para Conclusão	19-167
2.6	- Retenção das Embarcações Envolvidas em Acidentes e/ou Fatos da Navegação	19-167
2.7	- Procedimentos em Caso de Ocorrências Envolvendo Mercadorias Perigosas	20-167
2.8	- Prevenção de Acidentes	21-167
CAPÍTULO 3	**- DOTAÇÃO DE MATERIAL DE SEGURANÇA DAS EMBARCAÇÕES E DOCUMENTOS OBRIGATÓRIOS**	23-167
3.1	- Equipamentos Individuais de Salvatagem	23-167
3.2	- Equipamentos de Navegação e Publicações	24-167
3.2.1	- Embarcações de Transporte de Passageiros e/ou Cargas	24-167
3.2.2	- Navios Mercantes	26-167
3.3	- Documentação	27-167
3.3.1	- Embarcações Certificadas Classe 1 (EC1) com AB < 500	27-167
3.3.2	- Embarcações com AB ≥ 20	27-167
3.3.3	- Cartas Náuticas	27-167
3.4	- Responsabilidades	28-167
3.5	- Equipamentos de Rádio Comunicações	28-167
3.5.1	- Registro de Equipamento de Radiocomunicação	29-167
3.5.2	- Chamada Fonia	29-167

3.6	-Infrações	29-167
3.7	- Cartazes	29-167
3.8	- Dispositivos	30-167
3.8.1	- Amarração Balsa – Empurrador	30-167
3.9	-Embarcação de Apoio (Bote Orgânico)	30-167
3.10	- Outros Equipamentos, Dispositivos, Materiais e Publicações	31-167
3.10.1	- Luzes e Instalações Elétricas	31-167
3.10.2	- Uso de Sirene em Embarcações	31-167
3.10.3	- Marcação	31-167
3.11	- Uso de Uniformes	31-167
3.12	- Arqueação Bruta (AB) Maior Que 20	31-167
3.13	- Arqueação Bruta (AB) Menor Que 20	32-167
3.14	-Sistemas de Combustível	32-167
3.15	-Requisitos Adicionais Para Embarcações Que Operam Em Comboios	32-167
3.16	- Porte obrigatório de material de salvatagem	32-167
3.17	- Cartão de tripulação de Segurança (CTS)	33-167
3.17.1	-Navegação Interior (Embarcação de Passageiro/Carga)	33-167
3.17.2	-Navegação Interior (Comboio)	34-167
3.17.3	-Navegação Interior (Embarcações de Pesca)	35-167
CAPÍTULO 4	**- PROCEDIMENTO PARA NAVIOS NO PORTO**	36-167
SEÇÃO I	**- PROCEDIMENTOS PARA O TRÁFEGO E PERMANÊNCIA NO PORTO**	36-167
4.1	- Tráfego no Porto	36-167
4.2	- Empresas de Praticagem da Amazônia Ocidental	37-167
4.3	- Agências Marítimas	37-167
4.4	- Comandante de Embarcação Estrangeira	38-167
4.5	- Proibições	38-167
4.6	- Canal de Acesso e Sistema de Balizamento	38-167
4.7	- Entrada, Despacho e Saída de Embarcações	39-167
4.7.1	- Entrada da Embarcação	39-167
4.7.2	- Aviso de Entrada	39-167
4.7.3	- Entrada de Embarcação Estrangeira de Esporte e/ou Recreio	39-167
4.7.4	- Saída da Embarcação	39-167
4.7.5	- Pedido de Despacho	39-167
4.7.6	- Validade do Despacho	41-167
4.7.7	- Dispensa de Despacho	41-167
4.7.8	- Aviso de Saída	42-167
4.7.9	- Entrada, Permanência e Saída de Embarcação Estrangeira de Esporte e/ou Recreio	42-167
4.7.10	- Porto Sem Papel (PSP)	42-167
4.7.11	- Embarque de Pessoal não Tripulante	42-167
4.8	- Ferros e Amarração	43-167
4.9	- Transporte de Material e Pessoal	43-167
4.10	- Reparos	43-167

4.11	- Liberação de Embarcações Apreendidas	44-167
SEÇÃO II	**- SERVIÇO DE REBOCADORES**	44-167
4.12	- Condições de Uso de Rebocadores (Uso Obrigatório e Facultativo)	44-167
4.12.1	- Requisitos para Operar	44-167
4.12.2	- Situações de Maior Risco	45-167
4.12.3	- Recomendações sobre Tipo e Método de Emprego de Rebocadores	45-167
4.12.4	- Situações de Força Maior	46-167
4.12.5	- Disposições Complementares	46-167
SEÇÃO III	**- SERVIÇO PRATICAGEM**	47-167
4.13	- Propósito	47-167
4.13.1	- Serviço de Praticagem	47-167
4.13.2	- Características, Organização do Serviço das ZP da Área de Jurisdição e Número de Práticos Necessários para Execução das Fainas de Praticagem	48-167
4.13.3	-Número de Práticos Necessários a Realização das Fainas de Praticagem	48-167
4.13.4.	-Condições mínimas para alojamento e conforto térmico dos práticos a bordo	48-167
4.13.5	- Procedimentos Diversos	49-167
4.14	- Escala Única de Rodízio para Práticos	50-167
4.15	- Obrigações do Comandante	53-167
4.16	- Obrigações do Prático e do Praticante de Prático	53-167
4.16.1	- Compete ao Prático no Desempenho das Funções	53-167
4.16.2	- Compete ao Praticante de Prático	53-167
4.17	- Impraticabilidade	53-167
4.17.1	- Declaração de Impraticabilidade	54-167
4.17.2	- Procedimentos para Declaração de Impraticabilidade	54-167
4.18	- Qualificação do Praticante de Prático	55-167
4.18.1	- Exame de Habilitação para Prático	56-167
4.19	- Manutenção da Habilitação do Prático	56-167
4.19.1	- Plano de Manutenção de Habilitação da Zona de Praticagem (ZP-02)	56-167
4.19.2	- Fiscalização da escala de rodízio única (ERU)	57-167
4.19.3	- Obrigações das Praticagens da ZP-01 na área de jurisdição da CFAOC	57-167
SEÇÃO IV	**- SEGURANÇA ORGÂNICA**	57-167
4.20	- Segurança das Embarcações Contra Assaltos, Roubos e Similares	57-167
4.20.1	- Segurança Armada	58-167
4.21	- Presença de Tripulantes	59-167
SEÇÃO V	**- MEIO AMBIENTE**	59-167
4.22	- Preservação Ambiental	59-167
4.22.1	- Comunicação de Incidente Ambiental	59-167
4.22.2	- Plano de Emergência	59-167
4.22.3	- Cuidados para Evitar Poluição	60-167
4.22.4	- Recebimento e Transferência de Combustível	60-167
4.22.5	- Mercadorias Perigosas	61-167
4.22.6	- Manutenção de Dalas e Porões	61-167

4.23	- Embarcações que chegam ao Porto	62-167
4.23.1	- Embarcações que deixam o Porto	62-167
4.23.2	- Transporte De Álcool, Petróleo E Seus Derivados	62-167
SEÇÃO VI	**- FISCALIZAÇÃO POR AUTORIDADES NACIONAIS**	63-167
4.24	- Entrada da embarcação	63-167
4.24.1	- Entrada De Embarcação Estrangeira De Esporte e/ou Recreio	63-167
4.24.2	- Livre prática	63-167
4.24.3	- Quarentena	64-167
4.25	- Saída da Embarcação	64-167
4.26	- Port State Control e Flag State Control	64-167
CAPÍTULO 5	- **PARÂMETROS OPERACIONAIS DO PORTO E PROCEDIMENTOS ESPECIAIS**	65-167
SEÇÃO I	**- RESTRIÇÕES OPERACIONAIS**	65-167
5.1	- Calado Máximo Recomendado (Calado Operacional)	65-167
5.1.1	- Calado Máximo Recomendado nos Trechos da Jurisdição	65-167
5.1.2	- Recomendações	68-167
5.2	- Restrições de Velocidade, Cruzamento e Ultrapassagem	69-167
5.2.1	- Restrições de Velocidades	70-167
5.2.2	-Trapiches, Flutuantes, Embarcações E Portos Organizados	70-167
5.2.3	- Petrobras Solimões – TSOL	70-167
5.2.4	- Canais estreitos, paranás, igarapés e “furos”	71-167
5.3	- Restrições de Cruzamento e Ultrapassagem	71-167
5.4	- Restrições de Horário	71-167
5.5	- Restrições de Porte das Embarcações	71-167
5.6	- Restrições de Fundeio	71-167
5.6.1	- Áreas de Fundeio Permitido (Fundeadouros)	71-167
5.6.1.1	- Área de Manaus-AM	71-167
5.6.1.2	- Fundeadouro I	72-167
5.6.1.3	- Fundeadouro II	72-167
5.6.1.4	- Fundeadouro III	72-167
5.6.1.5	- Fundeadouro IV	72-167
5.6.1.6	- Fundeadouro V	72-167
5.6.2	- Área de Itacoatiara-AM	73-167
5.6.3	- Área de Novo Remanso-AM	74-167
5.6.3.1	- Fundeadouro Novo Remanso I	74-167
5.6.3.2	- Fundeadouro Novo Remanso II	75-167
5.6.3.3	- Fundeadouro Novo Remanso III	75-167
5.6.4	- Áreas de Fundeio Proibido	76-167
5.7	- Restrições nas Bacias de Manobra e Outras Restrições	77-167
5.8	- Monitoramento das Condições Batimétricas	77-167
5.9	- Parâmetros Operacionais Fora da Área dos Portos Organizados	77-167
5.9.1	- Rio Madeira	77-167
5.9.2	- Rio Juruá	77-167
5.10	- Calado Aéreo Máximo Admitido	78-167

SEÇÃO II	**- PLATAFORMAS, NAVIOS SONDA, FPSO, FSU, DEMAIS CONSTRUÇÕES E BOIAS DE GRANDE PORTE1-167**	78-167
5.11	- Plataformas, Navios Sonda, FPSO	78-167
5.11.1	- Estabelecimento	79-167
5.11.2	- Deslocamento	79-167
5.11.3	- Movimentação/Posicionamento	79-167
5.11.4	- Operações de Helicópteros a Bordo de Plataformas e Embarcações	79-167
5.11.5	- Embarcações para Resgate	79-167
5.12	- Recomendações para Fundeio de Plataformas em Águas Abrigadas e Semi – Abrigadas	80-167
5.13	- Boias de Grande Porte	81-167
5.13.1	- Identificação	81-167
5.13.2	- Lançamento	81-167
5.13.3	- Providências no Caso de uma Boia Garrar	81-167
5.14	- Operações de Mergulho	82-167
5.14.1	- Empresa de Mergulho	82-167
5.14.2	- Embarcações Operando com Mergulhadores	83-167
5.14.3	- São Obrigações do Contratante	83-167
5.14.4	- Obrigações da Empresa de Mergulho Contratada	84-167
SEÇÃO III	**- EVENTOS NÁUTICOS ESPECIAIS**	85-167
5.15	- Principais Procissões Marítimas e demais Eventos Náuticos na Área de Jurisdição	85-167
5.15.1	- Instruções de Caráter Geral	85-167
5.15.2	- Instruções para os Organizadores	85-167
5.15.3	- Instruções para os Participantes	86-167
5.15.4	- Instruções Complementares para Eventos Tipo Procissão Fluviais	87-167
5.15.5	- Instruções para a Queima de Fogos em Rios	87-167
5.15.6	- Instruções para Evento tipo Festa e Confraternização em Embarcações	89-167
5.15.7	- Aluguel de Embarcações e Eventos Náuticos	90-167
5.15.8	- Instruções Complementares para Empresas que Trabalham com Aluguel de Embarcações de Esporte e/ou Recreio	90-167
5.15.9	- Com Tripulante (s)	90-167
5.15.10	- Sem Tripulante (s)	90-167
5.16	- Pedalinhos, Stand Up, Bicicletas Aquáticas	91-167
5.16.1	- Pedalinhos	91-167
5.16.2	- Stand up Paddle	91-167
5.16.3	- Bicicletas Aquáticas	92-167
5.17	- Vistorias especiais e portabilidade do “passe” por ocasião do Festival Folclórico de Parintins	93-167
5.18	- Planejamento, Execução, Registro e Aperfeiçoamento	94-167
5.19	- Campanhas Educativas	94-167
CAPÍTULO 6	**- VIAS NAVEGÁVEIS DA JURISDIÇÃO**	95-167

SEÇÃO I	**- CONDIÇÕES DE NAVEGABILIDADE, SINALIZAÇÃO NÁUTICA E NAVEGAÇÃO**	95-167
6.1	- Vias Navegáveis Cartografadas	95-167
6.1.1	- Principais Características do Rio Amazonas	95-167
6.1.2	- Principais Características do Rio Solimões	97-167
6.2	- Vias Navegáveis Não Cartografadas	99-167
6.2.1	- Rio Maués, Paranás do Ramos e Urariá	100-167
6.2.2	- Rio Urucu	101-167
6.2.3	- Rio Negro	101-167
6.2.4	- Rio Branco	106-167
6.2.5	- Rio Purus	109-167
6.2.6	- Rio Juruá	111-167
6.2.7	- Rio Japurá	112-167
6.3	- Regras na Navegação Interior	112-167
6.3.1	- Normas para Tráfego de Comboio no Rio Urucu	113-167
6.3.1.1	- Constituição do Comboio Balsa Empurrador	113-167
6.3.1.2	- Navegação no Rio Urucu	113-167
6.4	- Comboios	114-167
6.4.1	- Dimensões dos Comboios	114-167
6.4.1.1	- Comboios tipo Homologados pela CFAOC	114-167
6.4.1.2	- Outros Requisitos	115-167
6.4.2	- Arrumação da Carga	116-167
6.4.2.1	- Balsa – Empurrador	116-167
6.4.2.2	- Balsa – Empurrador Com Conteiner Alojamento	117-167
6.4.2.3	- Embarcações de travessia	117-167
6.4.2.4	- Acessos	118-167
6.4.2.5	- Marcações	119-167
6.4.3	- Transporte de Madeiras em Toros Flutuantes	119-167
6.4.3.1	- Embarcações Necessárias	119-167
6.4.3.2	- Sinalização	119-167
6.4.3.3	- Dimensões Máximas	119-167
6.4.3.4	- Proibições	119-167
6.4.4	- Transporte de Produtos Inflamáveis	119-167
6.4.5	- Transporte de Material e Passageiros	120-167
6.5	- Dever de Informação	121-167
SEÇÃO II	**- OBRAS, DRAGAGENS E EXTRAÇÃO MINERAL**	121-167
6.6	- Obras em Vias Navegáveis	121-167
6.6.1	- Pontes	122-167
6.6.2	- Pontões	123-167
6.6.3	- Bares Flutuantes, Residências e Estabelecimentos Comerciais Flutuantes	124-167
6.6.4	- Planta de Situação	124-167
6.6.5	- Acompanhamento de Processos	124-167
6.7	- Barragens e Eclusas	125-167
6.8	- Dragagens	125-167
6.9	- Extração de Minerais	125-167

6.10	- Atualização de Documentos Náuticos	125-167
CAPÍTULO 7	- **DISPOSIÇÕES GERAIS**	126-167
SEÇÃO I	**- DEVERES E SANÇÕES**	126-167
7.1	- Deveres	126-167
7.1.1	- Deveres Adicionais para os Comandantes de Embarcações de Transporte de Passageiros	127-167
7.1.2	- Deveres Adicionais para os Comandantes de Embarcações de Transporte Escolar	127-167
7.1.3	- Marinas, Clubes Náuticos, Entidades Desportivas Náuticas, Estabelecimentos e Pessoas Físicas Cadastradas	127-167
7.2	- Amadores	133-167
7.3	- Infrações e sanções	133-167
7.4	- Assinatura na Declaração do Engenheiro responsável e no Termo de Responsabilidade de Construção/Alteração	134-167
7.5	- Inscrição De Canoas Indígenas E Ribeirnhas Menores Que 12 Metros	134-167
7.6	- Inscrições de embarcações regionais artesanais indígenas/ribeirinhas acima de 12m menores que 20 ab	135-167
7.7	-Transporte De Combustíveis Por Pequenas Embarcações Regionais Indígenas/Ribeirinhas Para Comunidades Distantes Das Cidades	136-167
7.8	- Reboque De Embarcações Utilizadas Em Pesca Esportiva	137-167
7.8.1	- Comprimento Do Dispositivo De Reboque	137-167
7.8.2	- Quantidade De Embarcações A Serem Rebocadas	138-167
7.8.3	- Instruções Gerais	134-167
ANEXOS:		
2-A	Encaminhamento das Informações Sobre Ocorrência de Perda ou Perda Provável de Mercadorias Perigosas em Águas Sob Jurisdição Nacional	139-167
3-A	Modelos de Placas a serem Colocadas em cada Convés de Barcos de Passageiros ou em Balsas de Travessia	141-167
4-A	Lista de Empresas de Rebocadores Disponíveis	142-167
4-B	Pilot Card	143-167
4-C	Lista de Verificação do Prático	145-167
4-D	Sinopse do Módulo Inicial da ZP-02	147-167
4-E	Sumário do Módulo Inicial da ZP-02	149-167

4-F	Guia para Organização do Programa de Qualificação para Praticante de Prático (PRP)	152-167
4-G	Programa Mínimo de Estágio de Qualificação de PRP	154-167
4-H	Quadro de Resumo Mensal de Manobras/Singraduras Acompanhadas/Realizadas por PRP	156-167
4-I	Relatório de Manobra/Singradura	157-167
4-J	Modelo de Portaria de Fainas de Praticagem	158-167
4-K	Modelo de Portaria da Banca Examinadora	160-167
4-L	Plano de Recuperação da Habilitação	161-167
4-M	Decálogo de Segurança	162-167
4-N	Papeleta de Solicitação de Troca de Serviço	164-167
6-A	Declaração de dados pessoais	165-167
7-A	Recomendações do uso do colete	166-167
7-B	Lista De Embarcação De Associados Das Marinas, Clubes E Entidades Desportivas Náuticas	167-167

INTRODUÇÃO

1. PROPÓSITO

Este documento tem como propósito consolidar as Normas e Procedimentos específicos para a jurisdição da Capitania Fluvial da Amazônia Ocidental, complementando a Legislação Nacional (Lei nº 9.537/1997 – Lei de Segurança do Tráfego Aquaviário, e o Decreto nº 2.596/98 – Regulamento da Lei de Segurança do Tráfego Aquaviário) e as Normas da Autoridade Marítima (NORMAM) em vigor, para atendimento das peculiaridades regionais. Constitui o principal documento normativo desta Capitania e Agências subordinadas, cujo conhecimento não desobriga os utilizadores a cumprir os dispositivos da Legislação Nacional em vigor e das NORMAM, bem como aqueles previstos nas Convenções Internacionais aplicáveis e ratificadas pelo Brasil.

1.1. LEGISLAÇÃO NACIONAL RELACIONADA DIRETAMENTE COM A SEGURANÇA DO TRÁFEGO AQUAVIÁRIO:

A relação das Normas da Autoridade Marítima (NORMAM/DPC) e das Normas e Procedimentos das Capitanias Fluviais/Portos (NPCF/NPCP) encontram-se disponíveis nos sítios "www.dpc.mar.mil.br" e "www.cfaoc.mar.mil.br", bem como algumas das principais Leis, Decretos e outros documentos normativos relacionados à Segurança da Navegação.

2. DEVERES

É dever do Comandante da embarcação, além de outras obrigações legais pertinentes, cumprir e fazer cumprir as presentes Normas e Procedimentos, bem como conhecer e divulgar aos tripulantes todas as informações contidas nas Normas da Autoridade Marítima (NORMAM/DPC) e demais documentos náuticos, tais como: Avisos aos Navegantes, Roteiro, Cartas Náuticas, Avisos Rádio Náuticos e SAR, além de outros emitidos pela Diretoria de Hidrografia e Navegação da Marinha do Brasil.

3. INFRAÇÕES E SANÇÕES

O não cumprimento das presentes Normas e Procedimentos será caracterizado como infração às mesmas, estando o infrator sujeito às penalidades previstas nos incisos VI e VIII, do art. 23, do Regulamento da Lei de Segurança do Tráfego Aquaviário (RLESTA), Decreto nº 2.596/98. De acordo com a legislação em vigor, as penas impostas poderão ser simultâneas e complementares, e serem impostas liminarmente.

4. COMPOSIÇÃO

Estas Normas e Procedimentos da Capitania Fluvial da Amazônia Ocidental (NPCF-CFAOC) estão divididas em sete Capítulos, a saber:

Capítulo 1 - Áreas de Jurisdição;
Capítulo 2 - Fatos e Acidentes da Navegação;
Capítulo 3 - Dotação de Material de Segurança das Embarcações e Documentos Obrigatórios;
Capítulo 4 - Procedimento para Navios no Porto;
Capítulo 5 - Parâmetros Operacionais do Porto e Procedimentos Especiais;
Capítulo 6 - Vias Navegáveis da Jurisdição; e
Capítulo 7 - Disposições Gerais.

CAPÍTULO 1

ÁREAS DE JURISDIÇÃO

SEÇÃO I

ORGANIZAÇÃO, JURISDIÇÃO E LIMITES

1.1. ORGANIZAÇÃO E JURISDIÇÃO

A Capitania Fluvial da Amazônia Ocidental (CFAOC) é composta por sua sede e pelas seguintes Agências subordinadas:

- Agência Fluvial de Caracaraí, no estado de Roraima;
- Agência Fluvial de Eirunepé, no estado do Amazonas;
- Agência Fluvial de Itacoatiara, no estado do Amazonas;
- Agência Fluvial de Parintins, no estado do Amazonas; e
- Agência Fluvial de Tefé, no estado do Amazonas.

1.2. CAPITANIA FLUVIAL DA AMAZÔNIA OCIDENTAL (CFAOC):

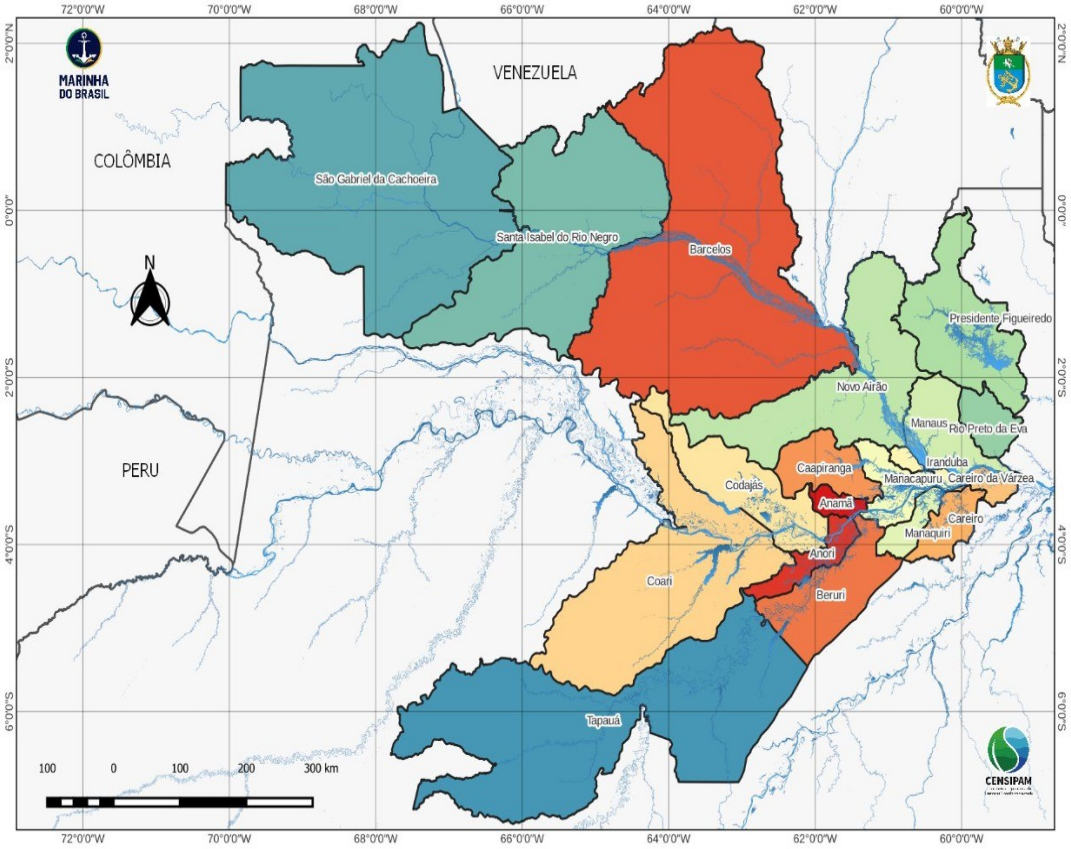

CFAOC	
Endereço	Rua Bernardo Ramos, s/n, Ilha de São Vicente, Centro, Manaus-AM, CEP: 69005-310.
Telefone	(92) 2123-4900
WhatsApp	(92) 99302-5040
Emergências Marítimas e Fluviais (SALVAMAR)	185.
Guarnecimento Permanente (VHF)	Canal 16.
Grupo de Atendimento ao Público (GAP)	Rua Marquês de Santa Cruz, nº 264, Centro, Manaus-AM, CEP: 69.005-050. Tel: (92) 2123-4909/2123-4910.
Horário de Atendimento do Grupo de Atendimento ao Público (GAP)	08h15min às 11h30min e 13h15min às 14h30min (dias úteis).
E-mail	cfaoc.secom@marinha.mil.br.
Despacho de Embarcações	cfaoc.despacho@marinha.mil.br.
Horário de Despacho	07h00 às 17h00

São águas jurisdicionais diretas desta Capitania o rio Negro e seus afluentes, o rio Amazonas e seus afluentes a montante do município de Itacoatiara-AM, o rio Solimões e seus afluentes a jusante do município de Tefé-AM, o rio Purus e seus afluentes, da foz no rio Solimões até o município de Tapauá-AM, e o rio Branco e seus afluentes abrangendo todos os rios, paranás, lagos, lagoas constantes dos seguintes municípios:

MUNICÍPIO	UF	MUNICÍPIO	UF
ANAMÃ	AM	MANACAPURU	AM
ANORI	AM	MANAQUIRI	AM
BARCELOS	AM	MANAUS	AM
BERURI	AM	NOVO AIRÃO	AM
CAAPIRANGA	AM	PRESIDENTE FIGUEIREDO	AM
CAREIRO	AM	RIO PRETO DA EVA	AM
CAREIRO DA VÁRZEA	AM	SANTA ISABEL DO RIO NEGRO	AM
COARI	AM	SÃO GABRIEL DA CACHOEIRA	AM
CODAJÁS	AM	TAPAUÁ	AM
IRANDUBA	AM	-	-

1.3. AGÊNCIA FLUVIAL DE EIRUNEPÉ (AgEirunepé):

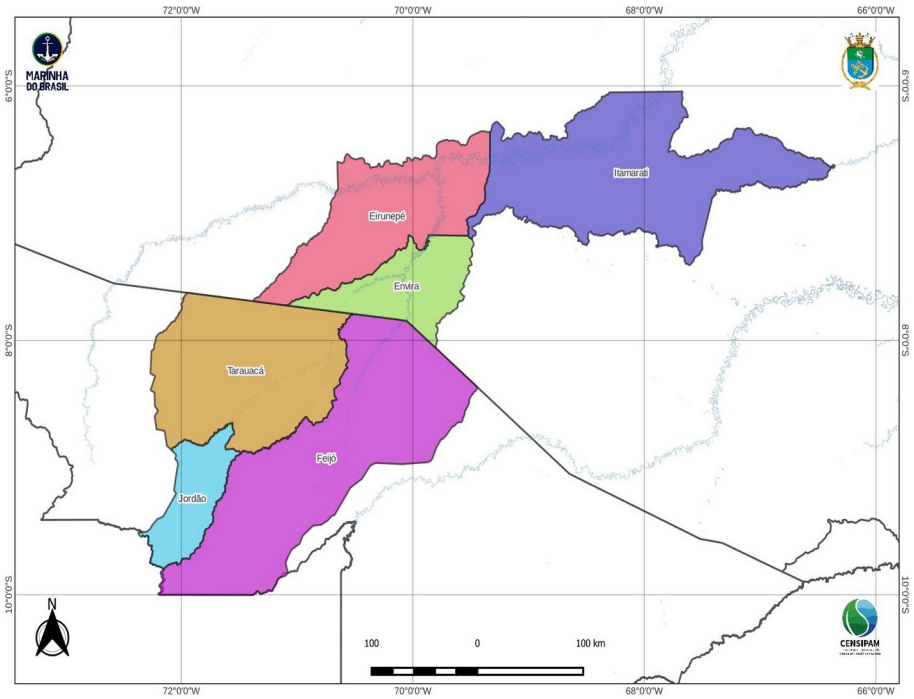

AgEirunepé	
Endereço	Rua Filipe Cunha, nº 113, Centro, Eirunepé-AM CEP 69880-000
Telefone	(97) 3481-1206.
WhatsApp	(97) 98127-6464.
Emergências Marítimas Fluviais (SALVAMAR)	185.
Guarnecimento Permanente	Canal VHF 16.
Horário Atendimento do GAP	08h às 12h e de 14h às 16h (dias úteis).
E-mail	ageirunepe.secom@marinha.mil.br.
Despacho de Embarcações	Grupo de atendimento ao Público.
Horário de Despacho	08h00min às 20h00min.

São águas jurisdicionais da AgEirunepé o rio Juruá e seus afluentes a montante de Caraurari-AM, abrangendo todos os rios, paranás, lagos, lagoas dos seguintes municípios:

MUNICÍPIO	UF	MUNICÍPIO	UF
EIRUNEPÉ	AM	ITAMARATI	AM
ENVIRA	AM	JORDÃO	AC
FEIJÓ	AC	TARAUACÁ	AC

1.4. AGÊNCIA FLUVIAL DE ITACOATIARA (AgItacoatiara):

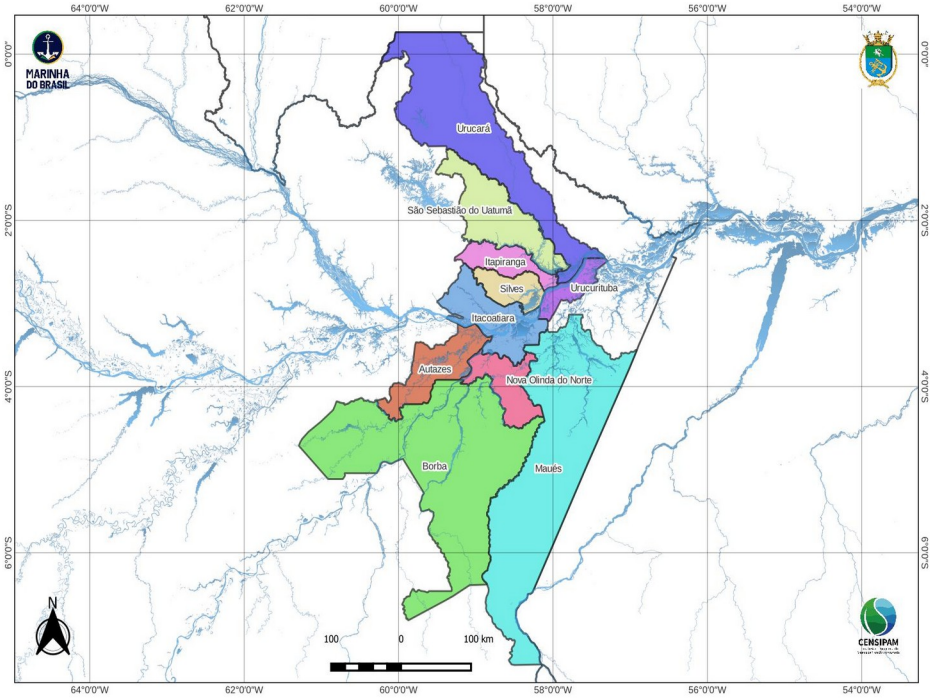

AgItacoatiara	
Endereço	Av. Parque, nº 262, Centro, Itacoatiara-AM, CEP: 69.100-000.
Supervisor de Serviço	(92) 99505-7281.
Telefone	(92) 3521-1131.
WhatsApp	(92) 99505-7281.
Emergências Marítimas e Fluviais (SALVAMAR)	185.
Guarnecimento Permanente (VHF)	Canal 16.
Horário de Atendimento do GAP	08h às 12h (dias úteis).
E-mail	agitac.secom@marinha.mil.br.
Despacho de Embarcações	Agenciafluvialdeitacoatiara@gmail.com
Horário de Despacho	08h15min às 11h15min e das 13h15min às 17h.

São águas jurisdicionais da **AgItacoatiara**: o rio Amazonas e seus afluentes a jusante da ilha da Grande Eva até o município de Urucará-AM, e o rio Madeira e seus afluentes, da foz no rio Amazonas até o município de Borba-AM, abrangendo todos os rios, paranás, lagos, lagoas constantes dos seguintes municípios:

MUNICÍPIO	UF	MUNICÍPIO	UF
AUTAZES	AM	NOVA OLINDA DO NORTE	AM
BORBA	AM	SÃO SEBASTIÃO DO UATUMÃ	AM
ITACOATIARA	AM	SILVES	AM
ITAPIRANGA	AM	URUCARÁ	AM
MAUÉS	AM	URUCURITUBA	AM

1.5. AGÊNCIA FLUVIAL DE PARINTINS (AgParintins):

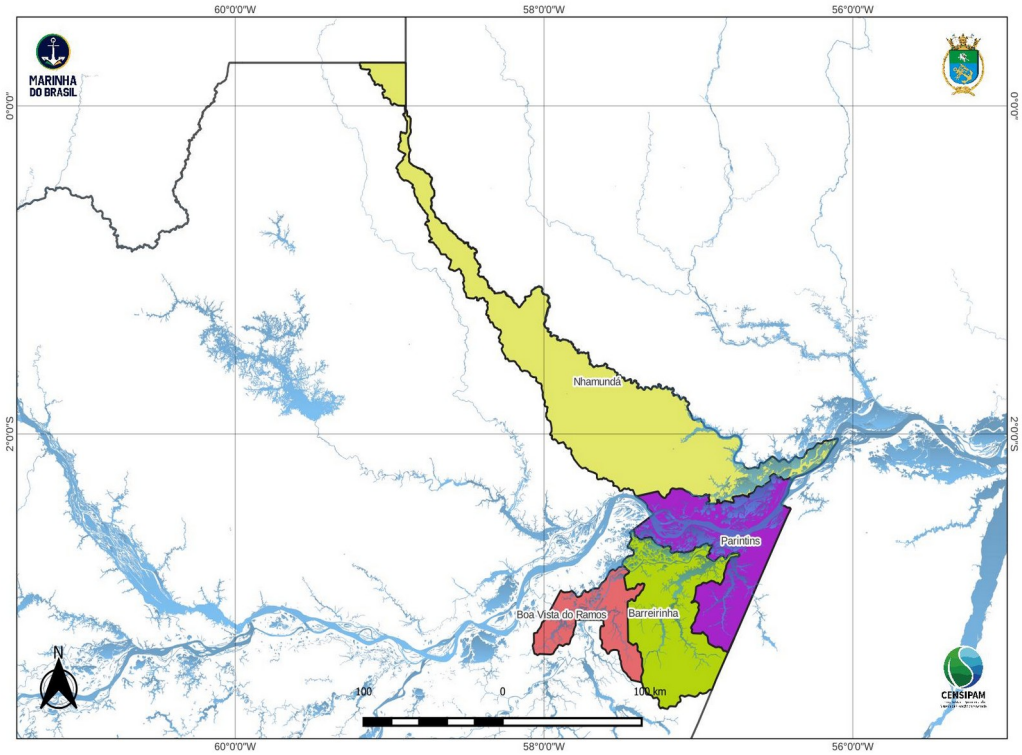

AgParintins	
Endereço	Rua Benjamim da Silva nº 1820, Centro, Parintins-AM, CEP: 69.151-270.
Telefone	(92) 3533-2967.
WhatsApp	(92) 98818-3219.
Emergências Marítimas e Fluviais (SALVAMAR)	185.
Guarnecimento Permanente (VHF)	Canal 16.
Horário de Atendimento do GAP	08h às 12h e de 14h às 16h (dias úteis).
E-mail	agparintins.secom@marinha.mil.br.
Despacho de Embarcações	agparintins.atendimento@marinha.mil.br.

Horário de Despacho	08h15min às 11hs15min e das 13h15min às 17h.

São águas jurisdicionais da AgParintins: no Estado do Amazonas, o rio Amazonas e seus afluentes da margem direita, até o município de Boa Vista do Ramos-AM, e seus afluentes da margem esquerda até o município de Nhamundá-AM, abrangendo todos os rios, paranás, lagos, lagoas constantes dos seguintes municípios:

MUNICÍPIO	UF	MUNICÍPIO	UF
BARREIRINHA	AM	NHAMUNDÁ	AM
BOA VISTA DO RAMOS	AM	PARINTINS	AM

1.6. AGÊNCIA FLUVIAL DE TEFÉ (AgTefé):

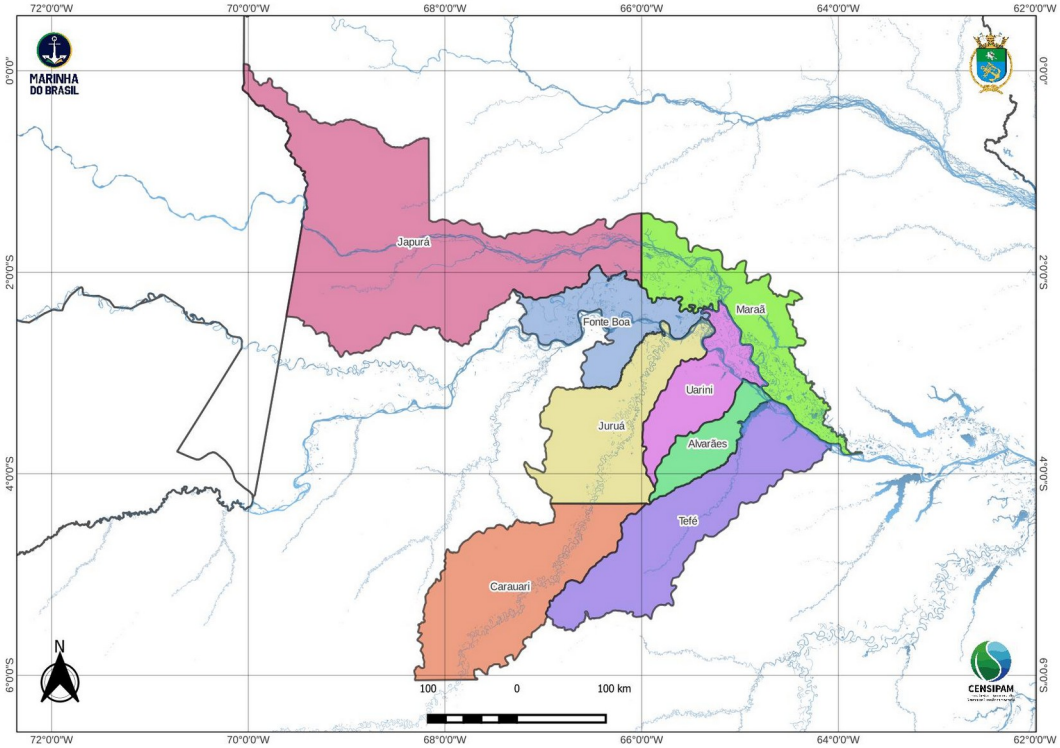

AgTefé	
Endereço	Rua Duque de Caxias, nº 287, Centro, Tefé-AM, CEP: 69.550-013.
Telefone	(97) 3343-2572.
WhatsApp	(97) 3343-2572.
Emergências Marítimas e Fluviais (SALVAMAR)	185.
Guarnecimento Permanente (VHF)	Canal 16.
Horário de Atendimento do GAP	08h às 12h e de 14h às 16h (dias úteis).

E-mail	agtefe.secom@marinha.mil.br.
Despacho de Embarcações	Agtefe.despachoeletronico@marinha.mil.br
Horário de Despacho	08h15min às 11h15min e das 13h15min às 17h.

São águas jurisdicionais da **AgTefé**: o rio Solimões e seus afluentes, a montante da sede do município de Tefé-AM até Fonte Boa-AM e a jusante até São João do Catuá, o rio Juruá e seus afluentes, da foz no rio Solimões até o município de Carauari-AM na comunidade de Bonfim, e o rio Japurá e seus afluentes, abrangendo todos os rios, paranás, lagos, lagoas constantes dos seguintes municípios:

MUNICÍPIO	UF	MUNICÍPIO	UF
ALVARÃES	AM	JAPURÁ	AM
CARAUARI	AM	MARAÃ	AM
FONTE BOA	AM	TEFÉ	AM
JURUÁ	AM	UARINI	AM

1.7. AGÊNCIA FLUVIAL DE CARACARAÍ (AgCaracaraí)

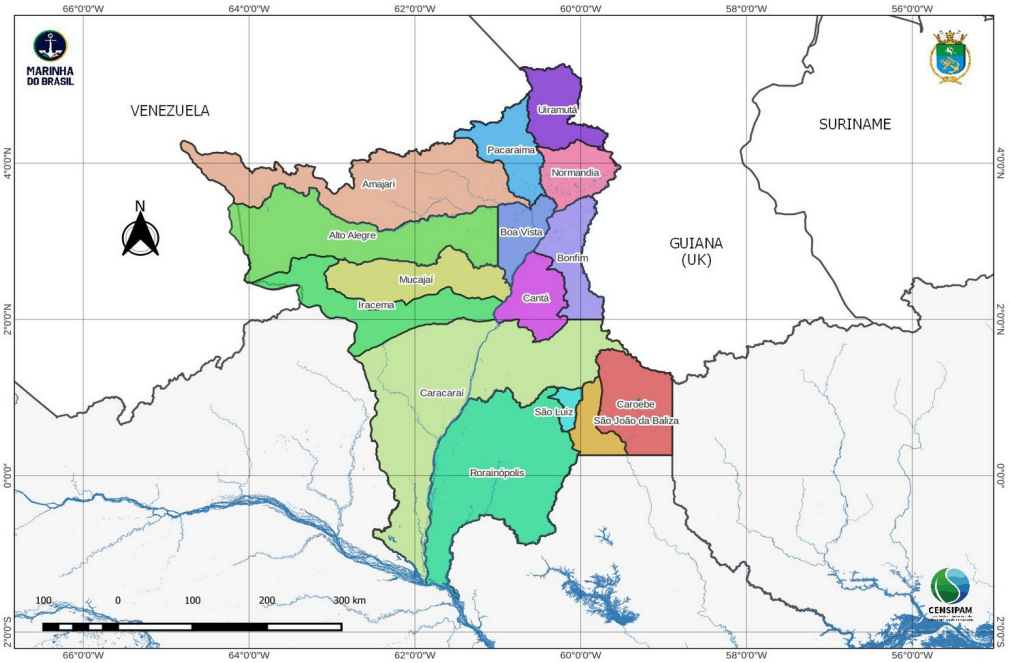

AgCaracaraí	
Endereço	Avenida Doutor Zany, S/N, Caracaraí – Centro - RR, CEP: 69.360-000.
Telefone	(95) 3532-1681.
WhatsApp	-
Emergências Marítimas e Fluviais	185.

(SALVAMAR)	
Guarnecimento Permanente (VHF)	Canal 16.
Horário de Atendimento do GAP	08h às 12h e 14h às 16h (dias úteis).
E-mail	agcaracarai.secom@marinha.mil.br
Despacho de Embarcações	Agcaracarai.despachoeletronico@marinha.mil.br
Horário de Despacho	08h15min às 11h15min e das 13h15min às 17h.

São águas jurisdicionais da AgCaracaraí: o rio Branco e seus afluentes, abrangendo todos os rios, paranás, lagos, lagoas constantes dos seguintes municípios:

MUNICÍPIO	UF	MUNICÍPIO	UF
ALTO ALEGRE	RR	MUCAJAÍ	RR
AMAJARI	RR	NORMANDIA	RR
BOA VISTA	RR	PACARAIMA	RR
BONFIM	RR	RORAINÓPOLIS	RR
CANTÁ	RR	SÃO JOÃO DA BALIZA	RR
CARACARAÍ	RR	SÃO LUÍS	RR
CAROEBE	RR	UIRAMUTÃ	RR
IRACEMA	RR	-	-

1.8. ATENDIMENTO AO PÚBLICO

1.8.1. DESCRIÇÃO DOS SERVIÇOS

a) A CFAOC e as suas Organizações Militares Subordinadas atendem ao público nos dias úteis, conforme discriminado no item 1.1

b) TIPOS DE SERVIÇO:

Os serviços prestados no Grupo de Atendimento ao Público (GAP) da CFAOC estão divididos entre serviços relativos às embarcações, serviços relativos aos Aquaviários e Amadores-

c) HORÁRIOS DE SERVIÇO:

Os serviços darão entrada por meio de agendamento eletrônico no site www.cfaoc.mar.mil.br, porém o cumprimento de exigências, defesa de infração, entrega de documentos e processos para o GVI não há necessidade de agendamento, sendo realizado nos seguintes dias e horários:

I) cumprimento de exigências e entrega de documentos: segunda-feira à sexta-feira, das 08h15 às 14h30;

II) defesa de notificações e infrações: segunda-feira à sexta-feira de 08h15 às 14h30min; e

III) processos para o GVI: segunda-feira à sexta-feira de 13h15min às 14h30min.

d) MEIOS PARA REALIZAR OS SERVIÇOS

Os processos poderão ser protocolados no GAP por meio de pessoas designadas pelo interessado (representantes legais), desde que estejam munidos de Procuração.

I) As cópias de quaisquer documentos poderão ser autenticadas pelo servidor a quem deva ser apresentado, mediante a apresentação do documento original.

II) Serão aceitos os comprovantes de residência (contas públicas) emitidas, no máximo, nos últimos 90 (noventa) dias corridos, ou as declarações de residência apresentadas e assinadas perante o servidor, conforme os Anexos 2-P da NORMAM-202/DPC, Anexo 2-I da NORMAM-211/DPC e Anexo 1-L da NORMAM 101/DPC.

III) No sítio da CFAOC (www.cfaoc.mar.mil.br) estão disponíveis informações sobre os serviços prestados nesta Capitania Fluvial.

IV) Todos Os Serviços Prestados Pela Capitania, Delegacias e Agências estão acessíveis a qualquer Pessoa Sem A Obrigatoriedade De Intermediação De Despachantes, Representantes ou quaisquer outros Intermediários.

V) Processos incompletos, rasurados, com erro ou outro motivo que, após analisado previamente, esteja em desacordo com as Normas ou se apresente inconsistências, não serão protocolados, com sua devolução imediata ao interessado ou preposto.

1.9. ACOMPANHAMENTO DE PROCESSOS

O proprietário de embarcação ou seu representante legal, ao protocolar seu processo, deverá cadastrar seu telefone celular e e-mail (preposto e proprietário), para recebimento de informações referentes ao andamento ou situação do respectivo processo.

O Acompanhamento poderá ser feito diretamente no site da Capitania, por meio do preenchimento do número do protocolo, no link:

https://sistemas.dpc.mar.mil.br/sisap/agendamento

1.10. VISTORIA DE EMBARCAÇÕES

As solicitações de vistoria de embarcações deverão ser feitas na CFAOC e Organizações Militares (OM) subordinadas, no horário de atendimento ao público nos guichês do Grupo de Atendimento ao Público (GAP). O serviço será realizado nos dias e horários definidos pela Capitania e Organizações Militares subordinadas, podendo ser alterado para outra data e horário, em razão de qualquer imperativo técnico/administrativo, devidamente justificado.

O transporte e estadia das comissões de vistorias e demais serviços em localidades fora da sede da Capitania ou das Agências deverá ser providenciado pelo solicitante.

1.11. CARTA DE SERVIÇOS AO USUÁRIO

A Capitania Fluvial da Amazônia Ocidental e Agências possuem, no sítio da CFAOC (www.cfaoc.mar.mil.br), a "Carta de Serviço ao Usuário", que tem por finalidade informar ao cidadão acerca dos serviços prestados pelo órgão, das formas de acesso a esses serviços e dos respectivos compromissos e padrões de qualidade de atendimento ao público.

A Carta divulga de maneira simples e clara os serviços que a CFAOC oferece e estipula os requisitos e a maneira como cada serviço deve ser tratado, antes de serem acessados pelo interessado. Por reconhecer o usuário como cliente parceiro e prioritário, a Carta de Serviços da CFAOC também aponta o caminho para as sugestões ou reclamações que possam vir a melhorar os processos, assegurando a efetiva participação do usuário na avaliação desses serviços prestados.

1.12. DENÚNCIAS E SUGESTÕES

É mantido em operação, 24 horas por dia, serviço de atendimento telefônico, gratuito, destinado a receber consultas sobre a segurança da navegação e denúncias sobre violação à Lei de Segurança do Tráfego Aquaviário, em toda a região Amazônica emergências Marítimas e Fluviais (SALVAMAR) - 185, que possui a finalidade de atender as emergências relativas à salvaguarda da vida humana, que possam atingir os navegantes no mar e nas vias navegáveis interiores.

1.13. LIMITES PARA A NAVEGAÇÃO INTERIOR

As áreas de navegação referentes à jurisdição da Capitania e Agências são classificadas como navegação Interior (conforme a definição constante nas Normas da Autoridade Marítima para Embarcações Empregadas na Navegação Interior - NORMAM-02/DPC).

1.14. NAVEGAÇÃO NO QUADRO

Considerando a característica peculiar de elevada extensão das vias navegáveis da Amazônia Ocidental, com concentração da navegação nas proximidades dos centros urbanos principais, foram estabelecidas áreas de navegação especiais denominadas de “Quadros”, onde a navegação, por suas características, necessita de regras especiais. Desta forma, qualquer embarcação que for navegar dentro de cada Quadro efetuará o Despacho conforme Capítulo 4 desta norma ou, alternativamente, apresentar o Anexo 2-J da NORMAM-202/DPC - Registro de Movimentação da Embarcação. A delimitação das áreas de cada Quadro encontra-se tabelada abaixo:

JURISDIÇÃO	QUADRO
CFAOC	Área do rio Negro compreendida entre a praia do Tupé e a localidade de Terra Nova, no Município de Manaus, delimitada pelas coordenadas: 03° 02’,0 S/ 059° 52’,0 W; 03° 13’,0” S/ 059° 52’ 00” W; 03° 02’,0 S / 060° 07’,5 W; e 03° 13’,0 S / 060° 07’ ,5 W, conforme Carta Náutica DHN n° 4110.
Agência de Caracaraí	Área do Rio Branco compreendido pelas seguintes coordenadas: ao norte pela LAT 01° 59`29.0``N e LONG 061° 01`43,4``W, na proximidade da Ilha do Cemitério a montante do furo do Conjubim. Ao sul pela LAT 01° 34`14.9``N e LONG 061° 13`58,7``W, nas proximidades da Ilha do Frio, a 10MN a jusante da Comunidade de Vista Alegre, no Município de Caracaraí -RR.
Agência Fluvial de Eirunepé	Área do rio Juruá compreendida entre a foz do rio Tarauacá, passando pelo porto de Eirunepé, até a praia de Paris, no município de Eirunepé-AM.
Agência Fluvial de Itacoatiara	Área do rio Amazonas compreendida entre a Ilha do Risco e a localidade de Ponta do Catarro no município de Itacoatiara-AM.
Agência Fluvial de Parintins	Área no rio Amazonas compreendida entre a enseada do Mocambo e a Ilha da Valéria, no município de Parintins-AM.
Agência Fluvial de Tefé	Lago de Tefé e área do Rio Solimões compreendida entre a localidade de Vila Caiambé a jusante e a cidade de Alvarães-AM a montante do

	município de Tefé-AM.

SEÇÃO II

CARACTERÍSTICAS PRINCIPAIS DOS PORTOS E SUAS ADMINISTRAÇÕES

1.15. CARACTERÍSTICAS PRINCIPAIS

Os portos da área de jurisdição da CFAOC e de suas Agências possuem diversas características peculiares, dentre elas os regimes de cheia e vazante dos rios. Além disso, o acesso a esses portos e terminais demanda a navegação por diversos pontos críticos relacionados no capítulo 6 desta NPCF, portanto, é obrigatório o conhecimento prévio do mencionado capítulo, bem como o estudo detalhado dos anexos abaixo relacionados:

a) o estudo minucioso dos demais documentos náuticos, tais como: avisos aos navegantes, roteiro, cartas náuticas, avisos rádio náuticos e SAR, e outros emitidos pela Diretoria de Hidrografia e Navegação da Marinha do Brasil; e

b) a leitura do Capítulo 4 destas Normas, que trata da entrada, permanência e saída dos portos.

1.16. TERMINAIS LOCALIZADOS NA ÁREA DE JURISDIÇÃO DA CFAOC E AGÊNCIAS

Os terminais portuários, hidroviários e as Instalações Portuárias Públicas de Pequeno Porte – IP4 localizados na área de jurisdição da CFAOC e de suas Agências são listados abaixo e as informações técnicas de cada um deles podem ser acessadas através dos links abaixo:

Terminais portuários e hidroviários:
https://www.marinha.mil.br/cfaoc/sites/www.marinha.mil.br.cfaoc/files/TERMINAIS PORTUARIOS - TUP E TERMINAIS HIDROVIÁRIOS
Instalações Portuárias Públicas de Pequeno Porte – IP4:
https://www.marinha.mil.br/cfaoc/sites/www.marinha.mil.br.cfaoc/files/INSTALAÇÕES PORTUARIAS PUBLICAS DE PEQUENO PORTE - IP4

1.16.1. Terminais Privados:

1.16.1.1. Terminal Hidroviário do AJATO

1.16.1.2. Terminal de Uso Privativo CHIBATÃO

1.16.1.3. Terminal de Uso Privativo SUPERTERMINAIS

1.16.1.4. Terminal de Uso Privativo da Moageira (TRIGOLAR)

1.16.1.5. Terminais Aquaviário de Manaus (TA–MANAUS-REAM)

1.16.1.6. Terminais Aquaviário de Manaus (ATEM)

1.16.1.7. Terminal Aquaviário de COARI (TA-COARI-TRANSPETRO)

1.16.1.8. Terminal de Uso Privativo CIMENTO VENCEMOS

1.16.1. 9. Terminal Hidroviário de CARAUARI

1.16..1 10. Terminal Hidroviário JOÃO DE DEUS

1.16.1.11. Terminal Hidroviário do DEMÉTRIO

1.16.1.12. Terminal Hidroviário de SÃO RAIMUNDO

1.16.2. Terminais Públicos:

1.16.2. 1. Porto Público de Manaus (Cais das Torres e Terminal Roadway)

1.16.2. 2. Instalações Portuárias Públicas de Pequeno Porte (IP4) MANACAPURU

1.16.2. 3. Instalações Portuárias Públicas de Pequeno Porte (IP4) TAPAUÁ

1.16.2. 4. Instalações Portuárias Públicas de Pequeno Porte (IP4) BERURI

1.16.2. 5. Instalações Portuárias Públicas de Pequeno Porte (IP4) ANORI

1.16.2.6. Instalações Portuárias Públicas de Pequeno Porte de (IP4) SANTA ISABEL RIO NEGRO

1.16.2.7. Instalações Portuárias Públicas de Pequeno Porte (IP4) NOVO AIRÃO

1.16.2.8. Instalações Portuárias Públicas de Pequeno Porte (IP4) BARCELOS

1.16.2.9. Instalações Portuárias Públicas de Pequeno Porte (IP4) CACAU PIRÊRA

1.16.2.10. Instalações Portuárias Públicas de Pequeno Porte (IP4) CAAPIRANGA

1.16.2.11. Instalações Portuárias Públicas de Pequeno Porte (IP4) MANAQUIRI

1.16.2.12. Instalações Portuárias Públicas de Pequeno Porte(IP4) CAREIRO DA VÁRZEA

1.16.2.13. Instalações Portuárias Públicas de Pequeno Porte (IP4) COARI

1.16.2.14. Instalações Portuárias Públicas de Pequeno Porte (IP4) CODAJÁS

1.16.2.15. Instalações Portuárias Públicas de Pequeno Porte (IP4) IRANDUBA

1.17. AGÊNCIA FLUVIAL DE ITACOATIARA:

1.17.1. Terminais Privados:

1.17.1.1. TUP Graneleiro da HERMASA

1.17.1.2. TUP TERMINAIS FLUVIAIS DO BRASIL S.A (TFB)

1.17.1.3. TUP Graneleiro MAQUIRA

1.17.1.4 TUP Porto de NOVO REMANSO

1.17.2. Terminais Públicos:

1.17.2.1. Instalações Portuárias Públicas de Pequeno Porte (IP4) de MAUÉS

1.17.2.2. Instalações Portuárias Públicas de Pequeno Porte (IP4) de ITAPIRANGA

1.17.2.3. Instalações Portuárias Públicas de Pequeno Porte (IP4) de BORBA

1.17.2.4. Instalações Portuárias Públicas de Pequeno Porte (IP4) de NOVA OLINDA DO NORTE

1.17.2.5. Instalações Portuárias Públicas de Pequeno Porte (IP4) de ITACOATIARA

1.17.2.6. Instalações Portuárias Públicas de Pequeno Porte (IP4) de ITACOATIARA PORTO NOVO

1.17.2.7. Instalações Portuárias Públicas de Pequeno Porte (IP4) de URUCARÁ

1.17.2.8. Instalações Portuárias Públicas de Pequeno Porte (IP4) de SILVES

1.17.2.9. Instalações Portuárias Públicas de Pequeno Porte (IP4) de URUCURITUBA

1.17.2.10. Instalações Portuárias Públicas de Pequeno Porte (IP4) AUTAZES

1.18. AGÊNCIA FLUVIAL DE EIRUNEPÉ

1.18.1. Instalações Portuárias Públicas de Pequeno Porte (IP4) de EIRUNEPÉ

1.18.2. Instalações Portuárias Públicas de Pequeno Porte (IP4) de ENVIRA

1.18.3. Instalações Portuárias Públicas de Pequeno Porte (IP4) de ITAMARATI

1.19. AGÊNCIA FLUVIAL DE PARINTINS:

1.19.1. Instalações Portuárias Públicas de Pequeno Porte (IP4) de PARINTINS

1.19.2. Instalações Portuárias Públicas de Pequeno Porte (IP4) de VILA AMAZÔNIA

1.19.3. Instalações Portuárias Públicas de Pequeno Porte (IP4) de NHAMUNDÁ

1.19.4. Instalações Portuárias Públicas de Pequeno Porte (IP4) de BOA VISTA DO RAMOS

1.20. AGÊNCIA FLUVIAL DE TEFÉ:

1.20.1. Instalações Portuárias Públicas de Pequeno Porte (IP4) de ALVARÃES

1.20.2. Instalações Portuárias Públicas de Pequeno Porte (IP4) de FONTE BOA

1.20.3. Instalações Portuárias Públicas de Pequeno Porte (IP4) de JAPURÁ

1.20.4. Instalações Portuárias Públicas de Pequeno Porte (IP4) de JURUÁ

1.20.5. Instalações Portuárias Públicas de Pequeno Porte (IP4) de MARAÃ

1.20.6. Instalações Portuárias Públicas de Pequeno Porte (IP4) de UARINI

1.20.7. Instalações Portuárias Públicas de Pequeno Porte (IP4) de TEFÉ

1.21. AGÊNCIA FLUVIAL DE CARACARAÍ:

1.21.1. Instalações Portuárias Públicas de Pequeno Porte (IP4) de CARACARAÍ

1.22. Documentações previstas para Obras e atividades afins em Águas sob Jurisdição Brasileira

Após portaria DPC /DGN/MB nº 55, 24 de maio de 2022, com sua data de alteração em 1º de junho de 2022, e de acordo com o contido na NORMAM-303/DPC, fica estabelecido que somente as Estruturas Flutuantes destinadas ao armazenamento de carga deverão apresentar os documentos pertinentes constantes da NORMAM-202/DPC quanto à inscrição, certificação e demais procedimentos previstos.

As demais obras descritas acima deverão apresentar os documentos previstos no item 2.3 da NORMAM-303/DPC para obtenção do PPO - Parecer Provisório de Obras ou PIP - Parecer de Interferência Prévia.

Por ocasião das atividades de Inspeção Naval nível 2, caso sejam verificados indícios de deterioração das condições de estabilidade, flutuabilidade ou estruturais das obras citadas acima, a Capitania ou Agência deverá:

- Notificar os responsáveis pelas obras;

- Interditar as obras, condicionando o retorno das operações após o reparo das estruturas e apresentação das condições de estabilidade / flutuabilidade;

- Divulgar a interdição da obra a comunidade marítima por meio de portarias;

- Solicitar novo laudo técnico elaborado por Engenheiro Naval com a respectiva ART – Anotação de Responsabilidade Técnica conforme previsto nos itens 2.3 a 2.6 do Capítulo 02 da NORMAM-303/DPC; e

- Autorizar a retomada das atividades após avaliação satisfatória do laudo técnico apresentado pelo responsável técnico e cumprimento de outras eventuais exigências.

CAPÍTULO 2

FATOS E ACIDENTES DA NAVEGAÇÃO

2.1. APLICAÇÃO

A ocorrência de Acidentes ou Fatos da Navegação, conforme definidos nas Normas da Autoridade Marítima para Inquéritos Administrativos sobre Acidentes e Fatos da Navegação (NORMAM-09/DPC), deverá ser comunicada tempestivamente à Capitania, Delegacia ou Agência de jurisdição, para abertura do competente Inquérito Administrativo sobre Acidentes e Fatos da Navegação (IAFN).

O contido nas NORMAM-302/DPC se aplica a qualquer acidente ou fato da navegação envolvendo:

a) embarcações mercantes e de esporte e recreio de qualquer nacionalidade, em águas jurisdicionais brasileiras, respeitando-se os regimes jurídicos previstos para o Mar Territorial, Zona Contígua, Zona Econômica Exclusiva e Plataforma Continental, em consonância com a Convenção das Nações Unidas sobre o Direito do Mar (Lei nº 8.617, de 4 de janeiro de 1993, e Decreto nº 1.530, de 22 de junho de 1995);

b) os aquaviários e amadores brasileiros;

c) os aquaviários e amadores estrangeiros, em território ou águas jurisdicionais brasileiras;

d) os proprietários, armadores, operadores, locatários, carregadores, agentes, consignatários de carga, sociedades classificadoras e respectivos prepostos de embarcações brasileiras e estrangeiras;

e) os empreiteiros e proprietários de construções executadas sob, sobre e às margens das águas interiores e que, por erro, ou inadequação de projeto, ou execução, ou pela não observância de especificações técnicas de materiais, métodos e processos adequados, ou ainda, por introduzir modificações estruturais não autorizadas nas obras originais, atentem contra a segurança da navegação;

f) toda pessoa jurídica ou física envolvida com construção e reparo naval;

g) as marinas, clubes náuticos, pontões, trapiches e similares;

h) as ilhas artificiais, instalações estruturais, bem como embarcações de qualquer nacionalidade, empregadas em operações relacionadas com pesquisa científica marinha, prospecção, exploração, explotação, produção, armazenamento e beneficiamento dos recursos naturais, nas águas interiores respeitados os acordos bilaterais ou multilaterais firmados pelo país e as normas do Direito Internacional; e

i) toda pessoa jurídica ou física envolvida em Acidente ou Fato da Navegação, por qualquer forma ou motivo, respeitados os demais instrumentos do Direito Interno e as normas do Direito Internacional.

As embarcações envolvidas no acidente ou fato da navegação, cujas avarias comprometam a navegação segura, serão retiradas de tráfego por Portaria e submetidas à vistoria após os devidos reparos, antes de serem liberadas. Além disto, as embarcações envolvidas deverão ser preservadas e disponibilizadas, por seus Comandantes, ao Encarregado do Inquérito, para serem submetidas às perícias necessárias.

É dever do Comandante da embarcação informar à Capitania, Delegacia ou Agência, ao chegar ao porto, ou antes, de sua saída, qualquer ocorrência definida como acidente ou fato da navegação envolvendo a sua embarcação e tripulação.

2.2. ACIDENTES E FATOS DA NAVEGAÇÃO

a) Consideram-se acidentes da navegação, qualquer evento que foge ao curso normal, causado por um evento alheio, imperícia, imprudência ou negligência, tais como:

I) naufrágio, encalhe, colisão, abalroamento, água aberta, explosão, incêndio, varação, arribada, alijamento (as definições completas de cada um desses acidentes podem ser observadas no item 1.6 da NORMAM-302/DPC); e

II) avaria ou defeito no navio, nas suas instalações, que ponha em risco a embarcação, as vidas e fazendas de bordo.

b) Consideram-se Fatos da Navegação, os eventos que alteram a capacidade, a rota e a utilidade de uma embarcação, por interesse pessoal ou organizacional e que coloca em risco toda uma comunidade, tais como:

I) o mau aparelhamento ou a impropriedade da embarcação para o serviço em que é utilizada e a deficiência da equipagem (as definições completas de cada um desses fatos da navegação podem ser observadas no item 1.6.2, alíneas A e b, da NORMAM-302/DPC);

II) a alteração da rota;

III) a má estivação da carga, que sujeite a risco a segurança da expedição;

III) a recusa injustificada de socorro à embarcação em perigo;

IV) todos os fatos que prejudiquem ou ponham em risco a incolumidade e segurança da embarcação, as vidas e fazendas de bordo; e

V) o emprego da embarcação, no todo ou em parte, na prática de atos ilícitos, previstos em lei como crime ou contravenção penal, ou lesivos à Fazenda Nacional.

VI) A comunicação de acidentes ou fatos da navegação deverá ser feita por meio dos telefones abaixo relacionados:

Disque Denúncia (WhatsApp)	(92) 2123-4900/(92) 99302-5040
Emergências Marítimas e Fluviais (SALVAMAR)	185
Capitania Fluvial da Amazônia Ocidental	(92) 2123-4900
Agência Fluvial de Eirunepé	(97) 98127-6464
Agência Fluvial de Itacoatiara	(92) 99505-7281
Agência Fluvial de Parintins	(92) 3533-2967
Agência Fluvial de Tefé	(97) 3343-2572
Agência Fluvial de Caracaraí	(95) 3532-1681

2.3. SITUAÇÕES NÃO TIPIFICADAS COMO ACIDENTE OU FATO DA NAVEGAÇÃO

Para apurar eventuais infrações e seus autores materiais, que tenham chegado ao conhecimento do Agente da Autoridade Marítima e não estejam perfeitamente tipificadas como acidente ou fato da navegação, poderá ser instaurado Inquérito Administrativo (IA), conforme previsto nas Normas da Autoridade Marítima para Atividades de Inspeção Naval (NORMAM-301/DPC).

No caso de acidentes com mergulhadores, quando no exercício de atividades subaquáticas, será obrigatória a instauração de IAFN/IA conforme o caso envolva embarcações ou não.

A CFAOC somente emitirá certidão de permanência no porto, ou sobre-estadia, a pedido da parte interessada, exclusivamente nos casos de ocorrência de acidente ou fato da navegação, cuja investigação demande tempo além do previsto para estadia normal da embarcação.

2.4. COMPETÊNCIA PARA INSTAURAÇÃO DE IAFN

a) Conforme determina o Art. 33 da Lei nº 2.180/54, será instaurado IAFN, sempre que chegar ao conhecimento de um Agente da Autoridade Marítima, por qualquer meio de comunicação, a ocorrência de acidente ou fato da navegação.

b) Somente as Capitanias (CP) e Delegacias (DL) poderão instaurar IAFN.

c) Quando uma Agência desta Capitania tiver o conhecimento da ocorrência de acidente ou fato da navegação, deverá comunicar imediatamente o fato à Capitania a que estiver subordinada, para que essa instaure o competente IAFN.

2.5. PRAZOS REFERENTES AOS IAFN

2.5.1. PRAZO PARA INSTAURAÇÃO

O IAFN deve ser instaurado imediatamente ou até o prazo de cinco (5) dias, contados da data em que uma das CP ou DL houver tomado conhecimento do acidente ou fato da navegação.

2.5.2. PRAZO PARA CONCLUSÃO

O IAFN deverá ser concluído no prazo máximo de noventa (90) dias, a contar da data da sua instauração até a ciência e o "de acordo" do Capitão dos Portos ou Delegado, podendo ser prorrogado por até um ano.

2.6. RETENÇÃO DAS EMBARCAÇÕES ENVOLVIDAS EM ACIDENTES E/OU FATOS DA NAVEGAÇÃO

Os navios mercantes e demais embarcações envolvidas em acidentes ou fatos da navegação poderão ser retidos, para investigação, apenas pelo tempo suficiente para a tomada de depoimentos de tripulantes e a realização do exame pericial, a fim de instruir o respectivo IAFN. Tal fato não deve ser confundido com eventuais retenções pelo Port State Control (PSC) ou Flag State Control (FSC), para cumprimento de exigências de vistorias.

A CFAOC e as Agências Subordinadas somente emitirão certidão de permanência no porto, ou sobrestada, a pedido da parte interessada, exclusivamente nos casos de ocorrência de acidente ou fato de navegação, cuja investigação demande tempo além do previsto para estadia normal da embarcação.

Após a ocorrência de um acidente ou fato da navegação é terminantemente proibido a alteração do local e das condições em que se encontre a embarcação ou as embarcações envolvidas, até que seja procedida a perícia. Por conseguinte, não devem ser efetuados repa-

ros, retiradas de peças e cargas ou tomadas quaisquer providências que prejudiquem as investigações, ressalvadas, naturalmente, aquelas necessárias à segurança da navegação, que devem ser adequada e detalhadamente justificadas.

Caso seja avaliado pelos inspetores navais/peritos navais que houve dano na estrutura da embarcação que possa levá-la a naufrágio, o responsável pela embarcação encaminhará a embarcação para o estaleiro ou local onde devam ser reparados os danos imediatamente, sendo liberada para voltar as atividades normais, após nova vistoria realizada pelas Entidades Certificadoras, que emitirá o competente Laudo Técnico atestando a incolumidade do casco quanto à estanqueidade, e posteriormente apresentará este documento na Capitania para a emissão do Termo de Liberação.

2.7. PROCEDIMENTOS EM CASO DE OCORRÊNCIAS ENVOLVENDO MERCADORIAS PERIGOSAS

São consideradas mercadorias perigosas todas as substâncias assim classificadas pela Convenção Internacional para Salvaguarda da Vida Humana no Mar (SOLAS-74) como os gases, líquidos e sólidos inflamáveis, substâncias comburentes, oxidantes, peróxidos orgânicos, venenosas, infecciosas, radioativas e corrosivas.

O transporte de mercadorias perigosas obedecerá às normas contidas na Convenção Internacional para Salvaguarda da Vida Humana no Mar - SOLAS-74, no “Internacional Maritime Dangerous Goods Code” - IMDG Code e demais normas previstas na legislação vigente, devendo ser observado o contido nas Normas da Autoridade Marítima para embarcações empregadas na navegação interior (NORMAM-202/DPC) e as Normas da Autoridade Marítima para transporte de cargas perigosas (NORMAM-201/DPC).

Os acidentes com embarcações transportando mercadorias perigosas nas vias fluviais da Amazônia Ocidental com perda ou perda provável de mercadorias perigosas devem ser imediatamente comunicados à Capitania e às demais autoridades competentes da área onde tenha ocorrido o acidente.

Os Comandantes das embarcações deverão comunicar o derramamento de poluentes à Capitania, Delegacia, Agência, ou à Estação Rádio mais próxima, conforme Anexo 2-A desta Norma, assim como informar ao IBAMA, à Diretoria de Portos e Costas, ao Comando do 9º Distrito Naval, além dos Órgãos Estaduais e Municipais de Meio Ambiente e Prefeituras

Municipais da área de jurisdição, citando o tipo e a quantidade de material, o local, se possível as coordenadas geográficas da embarcação responsável pela perda e outras informações julgadas necessárias. Outros procedimento/esclarecimentos sobre mercadorias perigosas constam na NORMAM-202/DPC.

O Brasil tem responsabilidades da divulgação desses incidentes, em atendimento a documentos da Organização Marítima Internacional.

As Estações Rádio, estações terrenas ou Sistema INMARSAT e estações de qualquer Sistema de Informações de Navio deverão retransmitir as informações supracitadas à Capitania, a fim de que sejam encaminhadas:

a) ao país da bandeira do navio implicado; e

b) a qualquer outro país que também possa ser afetado.

2.8. PREVENÇÃO DE ACIDENTES

Nos casos de Acidentes e Fatos da Navegação, cabe sempre ao Comandante da embarcação a avaliação da situação e as ações decorrentes. Assim, recomendam-se aos tripulantes das embarcações as seguintes ações preventivas e corretivas:

I) O condutor deverá ter pleno conhecimento prévio das regras para evitar abalroamento no mar (RIPEAM), a fim de agir em conformidade com este regulamento;

II) O condutor deverá, ao avistar a outra embarcação, fazer contato via rádio VHF ou, na sua falta deste, sinalizar com o apito ou holofote (se de noite), mantendo a marcação visual (rota de colisão), a fim de combinar a manobra de ultrapassagem de forma segura, levando em consideração a posição relativa em que se encontram e o canal navegável em função de seus calados.

III) Deve alertar as situações de risco aos tripulantes e passageiros, se for o caso.

IV) Dirigir-se à margem, a fim de encalhar a embarcação, se for o caso;

V) Providenciar material para efetuar o escoamento e colocar em uso a bomba de esgoto da embarcação e, caso disponha de outra bomba portátil, colocá-la também em uso;

VI) Pedir auxílio às embarcações em trânsito nas proximidades do acidente;

VII) Manter o adestramento da tripulação, fazendo uso periodicamente destes equipamentos;

VIII) Verificar antes de suspender a plena condição de operação das bombas de esgoto e colocá-las em pronto uso;

IX) Caso verifique que os equipamentos de esgoto não possuem vazão suficiente, providenciar o remanejamento ou a remoção da carga e, se for necessário, evacuar os tripulantes da embarcação de forma ordeira;

X) Evitar navegar próximo às margens, a fim de evitar troncos submersos.

XI)Verificar a situação segura das balaustradas antes do embarque de passageiros;

XII) Verificar se as retinidas das boias salva-vidas estão no devido local e sem obstruções ao seu acesso; e

XIII) Orientar aos passageiros como proceder em caso de testemunhar a queda de uma pessoa na água.

CAPÍTULO 3

DOTAÇÃO DE MATERIAL DE SEGURANÇA DAS EMBARCAÇÕES E DOCUMENTOS OBRIGATÓRIOS

As dotações de equipamentos e materiais para embarcações estão estabelecidas nas Normas da Autoridade Marítima para Embarcações Empregadas na Navegação Interior (NORMAM-202/DPC), Normas da Autoridade Marítima para Amadores, Embarcações de Esporte e/ou Recreio e para Cadastramento e Funcionamento das Marinas, Clubes e Entidades Desportivas Náuticas (NORMAM-211/DPC), Normas da Autoridade Marítima para Homologação de Material (NORMAM-321/DPC) e Entretanto, considerando as peculiaridades regionais dos rios da jurisdição da CFAOC e OM subordinadas, algumas exigências adicionais poderão ser impostas.

Para efeito de aplicação no presente capítulo, um empurrador é uma embarcação destinada a empurrar uma ou um conjunto de barcaças que formam um Comboio. Desta forma, a definição de Comboio diz respeito à combinação de uma embarcação do tipo empurrador quando acoplado a uma ou mais barcaças/balsas.

3.1. EQUIPAMENTOS INDIVIDUAIS DE SALVATAGEM

Colete Salva-vidas – equipamento individual de abandono, capaz de manter uma pessoa, mesmo inconsciente, flutuando por, no mínimo, 24 horas. Os coletes podem ser rígidos ou infláveis e são fabricados em quatro tamanhos diferentes, a saber:

- extragrande, para pessoas de massa igual ou superior a 110 kg;
- grande, para pessoas de massa igual ou superior a 55 kg e inferior a 110 kg;
- médio, para pessoas de massa superior a 35 kg e inferior a 55 kg; e
- pequeno, para crianças até 35 Kg.

Os coletes podem ser do tipo "canga" (de vestir pela cabeça) ou tipo "jaleco" (de vestir como paletó).

Equipamento	Embarcação	Observação
Colete salva-vidas	Todas as embarcações.	- As embarcações empregadas no transporte de passageiros deverão dotar, adicionalmente, uma quantidade de coletes salva-vidas

		adequada para crianças (colete tamanho pequeno) igual a pelo menos 10% do total de passageiros ou uma quantidade maior, de modo que haja um colete salva-vidas para cada criança. - São obrigados a usar (vestir) coletes salva-vidas os tripulantes e passageiros a bordo de: a) embarcações sem cabine habitável de transporte de passageiros; b) embarcações com borda livre menor que 30 cm; c) motos aquáticas; e d) embarcações que possuem cabine habitável, durante as manobras nas quais seus tripulantes realizam fainas em convés aberto.

3.2. EQUIPAMENTOS DE NAVEGAÇÃO E PUBLICAÇÕES

Em complemento à dotação de segurança prevista nas NORMAM-202/DPC, NORMAM-211/DPC e NORMAM-321/DPC, as embarcações abaixo classificadas para navegação interior, que transitem na área sob responsabilidade da CFAOC e OM subordinadas, deverão possuir os itens relacionados a seguir:

3.2.1. EMBARCAÇÕES DE TRANSPORTE DE PASSAGEIROS E/OU CARGAS

Equipamento	Embarcação	Observação
Aparelho Flutuante	Embarcações de transporte de passageiros com AB > 20; qualquer embarcação propulsada com AB > 100 e embarcações classificadas EC1, exceto as Estruturas Flutuantes que operam em local fixo e determinado, desde que estejam atracadas à margem	Para atender a 100% dos passageiros e tripulantes, acomodados de forma a ficarem livres para flutuar em caso de naufrágio.

	de rios, lagos, canais, píeres, etc.	
Ecobatímetro	Embarcações com AB > 20 e que transportam passageiros	Em embarcações com AB ≤ 20, (exceto em empurrador/rebocador) recomenda-se o uso do prumo de mão, graduado em metros.
Prancha com balaústre	Embarcações de passageiros com AB > 20.	As pranchas deverão ser confeccionadas de acordo com o modelo da NORMAM-02/DPC.
Rádio VHF fixo com potência ≥ 25W.	Embarcações com propulsão que transportem qualquer número de Passageiros; As demais embarcações com propulsão e AB ≥ 20; e qualquer embarcação com propulsão, de qualquer porte, que vá efetuar uma operação de eclusagem.	Exceto as miúdas, que poderão dotar equipamento de radiocomunicação em VHF móvel.
Mesa de Carta Náutica com iluminação	Embarcações propulsadas com AB > 100 e Empurradores de Comboios.	Exceto para embarcações empregadas em travessias menores que 1 hora.
Cartas náuticas e croquis da DHN	Embarcações com AB > 20 e empurrador/rebocador de qualquer AB.	Exceto para embarcações empregadas em travessias menores que 1 hora.
Radar	Embarcações propulsadas com AB ≥ 500 e todos os empurradores e rebocadores em comboios.	-
Sistema Automático de Identificação (Transceptor AIS, classe B)	Embarcações propulsadas com AB ≥ 500; e todos os empurradores e rebocadores em comboios.	-
Agulha magnética ou	Embarcações propulsadas com AB> 20; embarcações de Esporte	Embarcações propulsadas com AB ≥ 20 (recomendável).

giroscópica	e/ou Recreio com comprimento maior que 12m; e rebocadores e empurradores em comboios.	
Tubulações de descarga dos motores, eixos propulsores e partes móveis do motor	Todas as embarcações	Esses acessórios deverão ser protegidos, a fim de se evitar acidentes durante sua operação, principalmente queimaduras e Escalpelamento.

3.2.2. NAVIOS MERCANTES

Equipamento	Dotação/Operação	Observação
Ecobatímetro	Pelo menos um operando.	Em caso de avaria em viagem, deverá ser empregado o prumo de mão até a atracação do navio.
Radar	Dois operando.	Em caso de avaria em viagem, poderá ser empregado um até a atracação do navio. Não será permitido o navio navegar sem radar.
Rádio VHF fixo (25W)	Pelo menos um operando.	Não será permitido ao navio navegar sem Rádio VHF.
Cartas Náuticas	Atualizadas.	O navio só poderá navegar com cartas náuticas atualizadas.
Agulha Giroscópica	Pelo menos uma operando.	Em caso de avaria poderá ser usada a agulha magnética até a atracação do navio.
Agulha Magnética	Pelo menos uma com certificado de compensação válido.	Será usada durante o dia, em caso de avaria da agulha giroscópica.
Luzes de Navegação	Todas operando.	-
Ferros	Dois operando.	Não será permitida a navegação em águas interiores sem os dois

		ferros operando. Caso um dos ferros ou aparelho de fundeio esteja inoperante, a Capitania deverá ser consultada pelo Comandante da embarcação para avaliação da situação.

3.3. DOCUMENTAÇÃO

3.3.1. EMBARCAÇÕES CERTIFICADAS CLASSE 1 (EC1) COM AB < 500

Regras para Evitar Abalroamento	Cartão de Tripulação de Segurança
Título de Inscrição ou Provisão de Registro de Propriedade Marítima	Caderneta de Inscrição e Registro de cada Tripulante
Certificado ou Notas de Arqueação	Certificado Nacional de Borda-livre
Certificado de Conformidade para Transporte de Gases Liquefeitos a Granel	Declaração de Conformidade Para Transporte de Álcool, Petróleo e seus derivados.
–	Certificado de Segurança de Navegação
Plano de Segurança Aprovado por OR.	Tabelas ou Quadros de Balizamento
Tabelas ou Quadros de Regras de Governo e Navegação	Tabelas ou Quadros de Sinais Sonoros e Luminosos
Tabelas Quadros de Sinais de Salvamento	Tabelas ou Quadros de Primeiros Socorros
Treinamento específico da tripulação	Rol Portuário ou de Equipagem
Licença de Estação Navio (ANATEL)	Livro de Registro de Óleo
Livro de Descarte de lixo	

3.3.2. EMBARCAÇÕES COM AB< 20

Regras para Evitar Abalroamento	Cartão de Tripulação de Segurança (caso aplicável)
Título de Inscrição ou TIEM	Caderneta de Inscrição e Registro de cada Tripulante
Termo de Responsabilidade	Notas de Arqueação
Rol de Equipagem	Livro de Descarte de lixo
Licença de Estação Navio (ANATEL)	

3.3.3. CARTAS NÁUTICAS

A dispensa da dotação de cartas náuticas em papel é permitida quando a embarcação dispuser de um Sistema de Apresentação de Cartas Eletrônicas e de Informações (ECDIS), utilizando cartas eletrônicas oficiais (ENC), bem como um segundo ECDIS com backup do principal, instalado segundo preconizado pela Organização Marítima Internacional (IMO).

Cartas náuticas em formato RASTER não serão aceitas para o atendimento deste requisito, conforme estabelece as Normas da Autoridade Marítima para a Navegação e Cartas Náuticas (NORMAM-28/DHN).

3.4. RESPONSABILIDADES

Os comandantes dos navios são responsáveis pela manutenção das cartas náuticas atualizadas.

As empresas de navegação proprietárias/armadoras de navios de bandeira nacional responderão solidariamente aos Comandantes do navio.

Os práticos, ao embarcarem nos navios, deverão verificar se as cartas náuticas empregadas pelo navio até o ponto de embarque de prático e as utilizadas para a demanda deste ponto ao porto estão atualizadas. Caso constatem existência de cartas náuticas desatualizadas, estes deverão comunicar a irregularidade imediatamente à Capitania. Responderá solidariamente à infração o prático que não participar a irregularidade constatada à Capitania.

3.5. EQUIPAMENTOS DE RÁDIO COMUNICAÇÕES

a) As embarcações abaixo listadas deverão ser providas de, pelo menos, um equipamento de radiocomunicação em VHF fixo (25W) e que disponha da frequência de chamada de socorro 156,8 MHz (canal 16), devendo estas possuírem suas receptivas Licenças de Estação Navio emitida pela ANATEL.

I)Embarcações que transportem qualquer número de passageiros, exceto as miúdas;

II) Todas as demais embarcações com propulsão e AB maior que 100;

III)Qualquer barco, de qualquer porte, que vá efetuar uma operação de eclusagem; e

IV) Rebocadores e empurradores com AB maior ou igual a 20.

2. É recomendável que as embarcações possuam, pelo menos, mais um equipamento de VHF fixo (25W), podendo ser móvel os demais, para ser utilizado em situações de falha do equipamento orgânico.

3. A CP poderá exigir a instalação de equipamento de radiocomunicação em HF, para determinados tipos de embarcações, em função de suas características e da área em que irá operar.

4. Recomenda-se que as embarcações não citadas nas alíneas anteriores possuam, pelo menos, um equipamento VHF fixo (25W), podendo os demais equipamentos, caso existam, serem móveis.

3.5.1. REGISTRO DE EQUIPAMENTOS DE RADIOCOMUNICAÇÃO

Toda embarcação que seja dotada de um equipamento fixo de radiocomunicação deverá possuir a licença rádio, emitida pela Agência Nacional de Telecomunicações (ANATEL). A licença rádio deverá ser mantida a bordo da embarcação com o seu respectivo prazo de validade.

3.5.2. CHAMADA FONIA

A solicitação de identificação, nas águas interiores, por navios da Marinha do Brasil ou embarcações da Inspeção Naval, bem como das demais embarcações de fiscalização dos órgãos públicos competentes, deverá ser prontamente atendida. Caso a embarcação não disponha de estação radiotelefônica em VHF, ou esta se encontre inoperante, deverá empregar sinais visuais de acordo com o Código Internacional de Sinais que permitam sua identificação pela embarcação fiscalizadora.

3.6. INFRAÇÃO

Por ocasião das inspeções navais, o silêncio da fonia na frequência de chamada de socorro 156,8 MHz (canal 16) caracterizará a embarcação com rádio desligado, inoperante ou fora daquela frequência. Esse fato constitui infração, conforme os art. 21, inciso I, e/ou art. 23, inciso VI, do Decreto nº 2.596/1998 (RLESTA) que regulamenta a Lei nº 9537/1997 (LESTA).

3.7. CARTAZES

a) As embarcações que transportam passageiros e veículos deverão ter em locais visíveis ao público, placas, conforme discriminadas no Anexo 3-A desta norma, indicando:

I) Limites máximos de carga e de passageiros por convés;

II) Local de guarda dos coletes salva-vidas;

III) Localização das saídas de emergência;

IV) Telefone da empresa responsável pela embarcação;

V) Telefone da Capitania e Agências da área de jurisdição;

VI) Endereço eletrônico da Ouvidoria (Fale Conosco) da Capitania e Agências da área de jurisdição;

VII) Para embarcações de travessia de veículos, informação de obrigatoriedade de todos os veículos estarem com o freio de estacionamento (freio de mão) acionado, motor desligado, marcha engrenada, luzes apagadas e suas rodas calçadas com, pelo menos, dois calços, de modo a impedir movimentos durante a travessia e cintas de fixação; e

VIII) As pessoas não deverão permanecer no interior dos veículos, enquanto a embarcação estiver em movimento.

b) A concessionária deverá fixar em local visível ao público, junto aos pontos de embarque, os horários regulares de embarque.

c) Deverão ser confeccionados, ainda, para colocação em local visível, cartazes em idioma inglês e espanhol, contendo as mesmas informações acima citadas. Deverão existir setas indicando a Saída de Emergência, também pintadas nos idiomas **PORTUGUÊS**, **ESPANHOL** e **INGLÊS**.

3.8. DISPOSITIVOS

3.8. 1. AMARRAÇÃO BALSA EMPURRADOR

Deverá ser feita com cabo de aço obedecendo a ABNT – NBR-6327.

3.9. EMBARCAÇÃO DE APOIO (BOTE ORGÂNICO):

As embarcações propulsadas que possuam bote com propulsão limitada até 50 HP poderão ser utilizadas para apoiar a embarcação maior, devendo esta seguir os seguintes requisitos:

a) O tripulante, para condução desta embarcação, deverá portar sua respectiva Caderneta de Inscrição e Registro (CIR), não sendo permitida a utilização de CHA – Carteira de Habilitação de Amador;

b) Estas embarcações ficam proibidas de desenvolver atividades de esporte e/ou recreio;

c) Deverá constar em seu casco, em ambos os bordos, o nome e número de inscrição da embarcação para a qual realiza o apoio;

d) Estas embarcações poderão ter em sua lotação máxima 3 três tripulantes, sendo obrigatório, que o piloto seja da seção de convés, estando estas dispensadas de inscrição simplificada; e

e) Casos especiais: para lotação maior que esta regra exige, deverá apresentar as documentações previstas na NORMAM-202/DPC para processo de inscrição simplificada.

3.10. OUTROS EQUIPAMENTOS, DISPOSITIVOS, MATERIAIS E PUBLICAÇÕES

3.10. 1. LUZES E INSTALAÇÕES ELÉTRICA

Além de cumprir o preconizado na NORMAM-321/DPC, deverão ser observadas as seguintes orientações:

a) Todas as embarcações que possuírem mastros deverão ser dotadas de luzes de navegação, homologadas pela DPC, com seus respectivos certificados.

3.10. 2. USO DE SIRENE EM EMBARCAÇÕES

A instalação de sirenes somente é permitida em embarcações que pertençam a órgãos municipais, estaduais ou federais.

3.10. 3. MARCAÇÃO DO NÚMERO DE INSCRIÇÃO NO COSTADO

Todas as embarcações classificadas para atividade ou serviço de passageiro, pesca, esporte e recreio, carga, empurrador/rebocador e apoio portuário, devem ter o número de inscrição marcado no costado da embarcação, de modo visível e durável, em ambos os bordos e na cor contrastante a do costado, além das marcações já previstas nas NORMAM-201/DPC, NORMAM-202/DPC e NORMAM-211/DPC.

3.11. USO DE UNIFORME

Deverá seguir o que previsto na NORMAM-111/DPC.

3.12. ARQUEAÇÃO BRUTA (AB) MAIOR QUE 20

Os tripulantes de embarcações de passageiros e cargas deverão estar uniformizados, conforme especificado nas Normas da Autoridade Marítima para Uso de Uniformes da Marinha Mercante Nacional (NORMAM-111/DPC)

3.13. ARQUEAÇÃO BRUTA (AB) MENOR QUE 20

Os Tripulantes das embarcações estão dispensadas do uso de uniforme previsto na NORMAM-111/DPC, sendo o mínimo exigido o uso de camiseta meia manga com nome e categoria do aquaviário, bermuda ou calça jeans e sapato/tênis.

3.14. SISTEMAS DE COMBUSTÍVEL

Os sistemas de combustível de qualquer embarcação com AB maior que 20 deverão atender aos seguintes requisitos:

I) Não poderão ser utilizados combustíveis com ponto de fulgor inferior a 60° C (como álcool ou gasolina no interior da praça de máquinas);

II) Nenhum tanque ou rede de combustível deverá estar posicionado em local onde qualquer derramamento ou vazamento dele proveniente venha constituir risco de incêndio pelo contato com superfícies aquecidas ou equipamentos elétricos; e

III) Na saída de cada tanque de combustível e no indicador de nível deverá haver no mínimo uma válvula de fechamento na parte inferior, capaz de interromper o fluxo da rede.

3.15. REQUISITOS ADICIONAIS PARA EMBARCAÇÕES QUE OPERAM EM COMBOIOS

Todos os empurradores com AB >20, além dos requisitos dispostos no item 4.5 da NORMAM-202/DPC, deverá também observar o contido no item 4.24 da NORMAM-202/DPC.

3.16. PORTE OBRIGATÓRIO DE MATERIAL DE SALVATAGEM

As dotações de equipamentos e materiais para embarcações estão estabelecidas nas Normas da Autoridade Marítima para Embarcações Empregadas na Navegação Interior (NORMAM-202/DPC), Normas da Autoridade Marítima para Amadores, Embarcações de Esporte e/ou Recreio e para Cadastramento e Funcionamento das Marinas, Clubes e Entidades Desportivas Náuticas (NORMAM-211/DPC) e Normas da Autoridade Marítima para Homologação de Material (NORMAM-321/DPC). Entretanto, considerando as peculiaridades regionais dos rios da jurisdição da CFAOC e OM subordinadas, algumas exigências adicionais poderão ser impostas.

3.17. CARTÃO DE TRIPULAÇÃO DE SEGURANÇA (CTS)

Com o intuito de facilitar ao usuário e possibilitar uma visualização geral sobre a composição do CTS para a navegação interior, são apresentadas a seguir algumas informações que servem como orientação preliminar para emissão do CTS, sem prejuízo do contido na NORMAM-202/DPC, ou de outras necessidades verificadas por ocasião da Perícia para emissão deste documento.

O resultado da perícia para a emissão do CTS poderá modificar os parâmetros relacionados nos subitens abaixo em função das características de operação das embarcações, da tecnologia embarcada que porventura exija menos tripulantes para operar e/ou manter e outros itens observados.

3.17.1. NAVEGAÇÃO INTERIOR (EMBARCAÇÃO DE PASSAGEIRO/CARGA)

SEÇÃO DE CONVÉS	+ 3000 AB	ATÉ 3000 AB	ATÉ 750 AB	ATÉ 300 AB	ATÉ 50 AB	ATÉ 10 AB	MIÚDAS
COMANDO	CFL	PLF	MFL	CMF	MFC (6)	MAF	MAF
IMEDIATO	PLF	MFL/ CMF (4) (5)	CMF (4)	-	-	-	-
SUBALTERNO DE QUARTO	CMF	CMF/ MFC (5)	MFC	MFC	MFC/MAF (7)	MAF (1)	-
SERVIÇOS GERAIS	MAF (1)	MAF (4)	MAF (4)	MAF	MAF (1)	-	-
SERVIÇO CÂMARA	CZA (2)	CZA (2)	CZA (2)	CZA (2)	CZA (2)	-	-
	TAA (2) (8)	TAA (2) (8)	TAA (2) (8)	TAA (2)(8)	-	-	-
SEÇÃO SAÚDE	ASA (3)	ASA (3)	ASA (3)	ASA (3)	-	-	-
SEÇÃO DE MÁQUINAS		ATÉ 3000 KW	ATÉ 750 KW	ATÉ 500 KW	ATÉ 150 KW		ATÉ 37KW (50HP)
CHEMAQ		CTF	CTF	MFM	MMA		-

SUBCHEMAQ	-	-	-	-	-
SERV. DE QUARTO	MFM (4)	MFM (4)	MMA (1)	MMA (1)	-
SERV. GERAIS	MMA (1)	-	-	-	-

Observações:

(1) Dispensado para singradura inferior a 12 horas (de acordo com a NORMAM-02/DPC);

(2) Dispensado para singradura inferior a 12 horas e que trafeguem em área onde seja possível o apoio de rancho ou em navegação no Quadro (de acordo com a NORMAM-02/DPC);

(3) Obrigatório para embarcações com singradura maior de 12 horas e que transportem mais de 100 passageiros (de acordo com a NORMAM-202/DPC);

(4) Dispensado para navegação de travessia e de apoio portuário;

(5) Para embarcações até 1600AB;

(6) Para embarcações de passageiros, somente após 1 ano de embarque;

(7) MFC para embarcação com propulsão com potência acima de 500KW, que realize singradura superior a 12 horas e transporte mais 60 passageiros, caso não atenda deverá armar um MAF;

(8) Não havendo disponibilidade de TAA na jurisdição, pode ser substituído por MAF (Dispensado para navegação no Quadro);

(9) Considerar a singradura como sendo o total de horas navegadas entre o porto de origem e o porto de destino final sem escalas; e

(10) para aplicação dessa norma são consideradas embarcações miúdas aquelas: com comprimento inferior ou igual a (5) metros; ou com comprimento total inferior a oito (8) metros que apresentem as seguintes características**:** convés aberto ou convés fechado, sem cabine habitável e sem propulsão mecânica fixa e que, caso utilizem motor de popa, este não exceda 50HP. Considera-se cabine habitável aquela que possui condições de habitabilidade.

3.17.2. NAVEGAÇÃO INTERIOR (COMBOIO)

AB (COMBOIO)	COMANDANTE	IMEDIATO
ATÉ 300	CMF	-
ACIMA DE 300 até 750	MFL	CMF
ACIMA DE 750 até 3000	PLF	MFL
ACIMA DE 3000	CFL	PLF

3.17.3. NAVEGAÇÃO INTERIOR (EMBARCAÇÕES DE PESCA):

SEÇÃO DE CONVÉS	ATÉ 750 AB	ATÉ 300 AB	ATÉ 50 AB	ATÉ 10 AB
COMANDO	PPI	CPI	PEP	POP
SERVIÇO DE GERAIS	PEP	PEP	POP	-
SERVIÇOS QUARTO	POP	POP	POP	-
SEÇÃO DE MÁQUINAS	ATÉ 3000 KW	ATÉ 750 KW	ATÉ 500 KW	ATÉ 150 KW
	CTF	CTF/MNM	CMP	MOP

CAPÍTULO 4

PROCEDIMENTOS PARA NAVIOS E EMBARCAÇÕES NO PORTO

SEÇÃO I

PROCEDIMENTOS PARA O TRÁFEGO E PERMANÊNCIA NO PORTO

4.1. TRÁFEGO NO PORTO

O tráfego no porto obedecerá ao preconizado nas Normas da Autoridade Marítima para Operação de Embarcações Estrangeiras em Águas Jurisdicionais Brasileiras (NORMAM-2023/DPC) e Normas da Autoridade Marítima para Tráfego e Permanência de Embarcações em Águas Jurisdicionais Brasileiras (NORMAM-204/DPC), bem como as regras previstas em convenções internacionais ratificadas pelo país, e aquelas emitidas pela Administração do porto. Especial atenção à presença de embarcações de pequeno porte, principalmente no período noturno ou em baixa visibilidade. Usar sinais sonoros e iluminar eventualmente a derrota com holofotes são providências recomendadas.

Os navios mercantes que demandarem os portos da jurisdição da CFAOC e que tenham sido inspecionados em algum porto no âmbito do acordo de “Viña Del Mar” há mais de seis meses ou estejam em condições materiais não condizentes com a salva guarda da vida humana, a prevenção da poluição e a segurança da navegação devem ser, prioritariamente, submetidos à inspeção do “Port State Control”.

Cabe ao Capitão dos Portos da Amazônia Ocidental coordenar com a Autoridade Portuária, ou administração dos portos e terminais, o estabelecimento de limitações operacionais nos portos/terminais de sua jurisdição, tais como o calado máximo recomendado e a velocidade de evolução nos trechos navegáveis, canais de acesso e áreas portuárias.

Cabe à administração do porto ou terminal fixar, com base na documentação pertinente ou no consenso obtido, o limite da área sob a responsabilidade de cada administração para efeito de divulgação dos calados máximos recomendados, nos acessos e berços e velocidades de trânsito. Especificamente para os portos da área de jurisdição da CFAOC e OM subordinadas, as restrições operacionais são detalhadas nos **Anexos 1-A a 1-GGG**, sendo obrigatório o seu estudo.

O Capitão dos Portos definirá os trechos onde tais responsabilidades estiverem a cargo da Autoridade Marítima.

Por provocação da administração do porto ou terminal, poderá ocorrer reunião extraordinária, com o propósito de promover alterações nas limitações operacionais estabelecidas nestas normas, ocasião esta que, a critério do Capitão dos Portos, os práticos poderão ser convidados para assessoramento. Entretanto, as alterações somente serão efetivadas após a aprovação pelo Representante da Autoridade Marítima.

Todas as embarcações com AB > 20 atracadas, fundeadas e abarrancadas na área de jurisdição da Amazônia Ocidental deverão manter a bordo tripulação de forma qualitativa e quantitativa suficiente para as possíveis manobras que poderão ser realizadas, conforme itens 2.3 desta Norma e ademais, com o intuito de prevenir qualquer acidente com vistas à manutenção da segurança da navegação, à preservação da vida humana de passageiros, tripulantes e vigilantes e à prevenção da poluição hídrica; bem como, a verificação do cumprimento das normas da autoridade marítima pelos inspetores navais/vistoriadores navais.

4.2. EMPRESAS DE PRATICAGEM DA AMAZÔNIA OCIDENTAL

A ATALAIA coordenadora do serviço de Praticagem Informará os navios previstos para serem manobrados no dia seguinte por meio de comunicação à CFAOC através do e-mail (cfaoc.secom@marinha.mil.br e cfaoc.despacho@marinha.mil.br). Os seguintes dados poderão ser fornecidos:

- Nome do navio;
- Porto de origem ou destino;
- Horário previsto de chegada ou saída; e
- Tipo de carga.

4.3. AGÊNCIAS MARÍTIMAS

As Agências Marítimas informarão**, em até 72 horas antes da chegada do navio** no porto ou terminal, por e-mail (cfaoc.despacho@marinha), os seguintes dados:

- Nome e número IMO;
- Armador;
- Ano de construção ou idade;
- Tipo de navio;
- Bandeira;

- Sociedade Classificadora; e
- Seguradora.

As Agências Marítima deverão, ainda, transmitir todas as informações necessárias aos Comandantes dos Navios estrangeiros quanto aos requisitos para operação em AJB, em especial quanto à Praticagem obrigatória, conforme estipulado na NORMAM-311/DPC.

4.4. COMANDANTE DE EMBARCAÇÃO ESTRANGEIRA

Aquelas que não são representadas por agências marítimas deverão informar, com **até 24 horas de antecedência**, a sua chegada ou necessidade de fundear em águas jurisdicionais brasileiras (AJB), bem como o motivo porque vão fazê-lo. Em caso de fundeio de emergência ou arribada, deverão informar tão logo seja possível. Após a sua atracação, o navio deverá cumprir os procedimentos previstos para a legalização de seu despacho nas Águas Jurisdicionais Brasileiras (AJB).

4.5. PROIBIÇÕES

Manter tráfego de embarcações miúdas entre os navios de longo curso, cabotagem e/ou estrangeiras, e pontos de terra não alfandegados, bem como manter tal tráfego antes das visitas obrigatórias.

I. Lançar lixo, detritos, fazer esgoto de porão ou de tanques que contenham poluentes, bem como permitir situações que favoreçam sua queda acidental nas águas.

II. Manter embarcações a contrabordo sem a devida iluminação.

III. Arriar embarcações de salvatagem para finalidade diferente da prevista, sem a autorização da Capitania.

4.6. CANAL DE ACESSO E SISTEMA DE BALIZAMENTO

Observar as publicações na página do Centro de Hidrografia da Marinha (https://www.-mar.mil.br/dhn/chm/box-publicacoes/publicacoes/publicacoes.htm), em especial o catálogo de cartas e publicações, CARTA 12000 Símbolos, Abreviaturas e Termos usados nas Cartas Náuticas, Roteiro Costa Norte, Lista de sinais cegos, Avisos-Rádio Náuticos e Avisos aos Nave-gantes.

4.7. ENTRADA, DESPACHO E SAÍDA DE EMBARCAÇÕES

As embarcações que demandarem os portos e terminais da área de jurisdição da CFAOC e Agências subordinadas e que não estiverem abrangidas pelo sistema Porto Sem Papel (PSP) deverão cumprir os procedimentos abaixo estabelecidos, em complemento às Normas da Autoridade Marítima para Tráfego e Permanência de Embarcações em Águas Jurisdicionais Brasileiras (NORMAM-204/DPC), referente aos procedimentos de entrada, despacho e saída.

4.7.1. ENTRADA DA EMBARCAÇÃO

4.7.2. AVISO DE ENTRADA

Em complemento as informações previstas no Aviso de Entrada – Navegação Interior (Anexo 1-H da NORMAM-204/DPC), para as embarcações onde os Serviços de Praticagem sejam obrigatórios, deverá constar, no campo observações, o nome dos práticos que atenderam o navio.

4.7.3. ENTRADA DE EMBARCAÇÃO ESTRANGEIRA DE ESPORTE E/OU RECREIO

Para a entrada de embarcações estrangeiras de esporte e recreio será observado o contido no item 1.16.1, da NORMAM-211/DPC, não havendo normas complementares desta Capitania.

4.7.4. SAÍDA DA EMBARCAÇÃO

O Pedido de Despacho e Aviso de Saída – Navegação Interior (Anexo 1-I da NORMAM-204/DPC) de embarcações será realizado conforme a NORMAM-204/DPC, ressalvadas as determinações abaixo especificadas:

4.7.5. PEDIDO DE DESPACHO

São obrigadas a despachar as seguintes embarcações:

5. de bandeira estrangeira;
6. com Arqueação Bruta (AB) $\geq$ 20;
7. de pesca com AB > 10;
8. em atividade comercial de transporte de passageiros com, no mínimo, 10 passageiros; e
9. todas as embarcações que realizam navegação de travessia e turismo náutico na

mesma área portuária.

Além dos documentos previstos no Item 1.1 da NORMAM-204/DPC, é obrigatória a apresentação dos seguintes documentos ou seus substitutos previstos nas NORMAM:

I) Cartão de Tripulação de Segurança (CTS), quando aplicável à embarcação;

II) Certificado de Segurança da Navegação (CSN);

III) Seguro DPEM, quando houver obrigatoriedade;

IV) Provisão de Registro de Propriedade Marítima (PRPM) ou o Documento Provisório de Propriedade (DPP) ou o Título de Inscrição de Embarcação (TIE), conforme a AB da embarcação;

V) Certificado Nacional de Borda Livre (CNBL), quando aplicável à embarcação e demais 6) Certificados específicos previstos nas Normas da Autoridade Marítima;

VI) Caderneta de Inscrição e Registro (CIR) e Atestado de Saúde Ocupacional (ASO) de todos os tripulantes na validade; e

O Pedido de Despacho da embarcação deverá ser solicitado por e-mail (despacho.cfaoc@mar.mil.br) na CFAOC ou diretamente nas Agências subordinadas, devendo ser enviados os documentos conforme acima especificados. Os pedidos de despacho serão realizados até as 17h00.

No que tange aos comboios (empurrador e balsa), fica facultado aos armadores, proprietários ou prepostos alterar as balsas do comboio despachado inicialmente, desde que apresentem, antes da saída, um novo Aviso de Saída – Navegação Interior (antiga Declaração Geral) devidamente atualizado, e que a tonelagem do conjunto alterado esteja condizente com a categoria dos tripulantes armados no empurrador, sendo emitido pelo Órgão de Despacho (OD), neste caso um novo Passe de Saída – Por Período (Anexo 1-F da NORMAM-204/DPC).

No período de validade dos Despachos, os armadores ou seus prepostos deverão encaminhar, obrigatoriamente, à CFAOC e Agências subordinadas, o Aviso de Entrada ou o Aviso de Saída das suas respectivas embarcações quando atracando ou desatracando nos Portos e Terminais no prazo máximo de quatro (4) horas ao Órgão de Despacho (OD), após a atracação ou saída das mesmas, não a isentando de apresentarem os respectivos avisos atualizados à Equipe de Inspeção Naval, por ocasião da abordagem.

As alterações de Tripulantes ou Passageiros serão apresentados por meios das Listas de Tripulante e Passageiros anexos aos Avisos de Entrada e Saída, em até meia hora após o

suspender ou atracar, com a apresentação destes documentos, não será necessário apresentar um novo Despacho, exceto para as embarcações que realizam navegação de travessia e turismo náutico na mesma área portuária, que estão dispensadas, contudo devem manter arquivado tais documentos para apresentar a Capitania, caso solicitado.

4.7.6. VALIDADE DO DESPACHO

a) A tramitação de informações sobre despacho de embarcações, entre o representante legal da embarcação e o OD (CFAOC) deverá ocorrer na seguinte ordem:

I) Via Porto Sem Papel (PSP), quando de uso obrigatório, à medida que forem sendo implantados;

II) Via e-mail (despacho.cfaoc@mar.mil.br), a qualquer tempo e para todas as embarcações, exceto as que transportam passageiros, com validade até o próximo porto; e

III) Diretamente no Grupo de Atendimento ao Público (GAP), quando não houver disponibilidade das opções acima, nos horários das 08h15 às 11h30 e das 13h15 às 17h00.

b) A validade do despacho poderá ser concedida da seguinte forma:

I) Até o próximo porto: para as embarcações empregadas na navegação de longo curso.

II) Por período de até trinta dias, dependendo da validade dos documentos apresentados, para as embarcações que realizam navegação de travessia ou turismo náutico na mesma área portuária.

III) Por período de até sessenta dias, dependendo da validade dos documentos apresentados, para as embarcações empregadas na navegação interior em tráfego na área de jurisdição desta Capitania Fluvial.

4.7.7. DISPENSA DE DESPACHO

a) Embarcações de Esporte e/ou Recreio, de qualquer porte;

b) Navios de Guerra de qualquer nacionalidade;

c) Navios de Estado, não exercendo atividades comerciais;

d) As embarcações de passageiros com menos de 10 passageiros, que trafeguem dentro do Quadro;

e) Quando a embarcação estiver se movimentando entre portos da mesma área portuária, não será necessário realizar o despacho, devendo ser apresentado Registro de

Movimentação da Embarcação (Anexo 1-J da NORMAM-204/DPC); e

f) Embarcações que fazem apoio logístico a navios.

4.7.8. AVISO DE SAÍDA

Em complemento as informações previstas no Aviso de Saída (Anexo 1-O da NORMAM-204/DPC), para as embarcações onde os Serviços de Praticagem sejam obrigatórios, deverá constar no campo “observação” o nome dos práticos que atenderam o navio.

4.7.9. ENTRADA, PERMANÊNCIA E SAÍDA DE EMBARCAÇÃO ESTRANGEIRA DE ESPORTE E/OU RECREIO

Para a entrada, permanência e saída de embarcações estrangeiras de esporte e/ou recreio será observado o contido no Anexos 1-A/1-B da NORMAM-211/DPC.

4.7.10. PORTO SEM PAPEL (PSP)

Projeto gerenciado pela Secretaria Especial de Portos da Presidência da República (SEP/PR), que tem por objetivo promover a desburocratização dos procedimentos de estadia dos navios nos portos brasileiros, de forma a aperfeiçoar os processos de importação e exportação, a partir de um portal de informações portuárias, integrando num único banco de dados as informações de interesse dos agentes de navegação e dos diversos órgãos públicos que operacionalizam e gerenciam as estadias de embarcações nos portos brasileiros.

A tramitação de documentos pelo sistema PORTO SEM PAPEL obedecerá ao contido no Item 1.16 NORMAM-204/DPC.

4.7.11. EMBARQUE DE PESSOAL NÃO TRIPULANTE

O embarque e desembarque de não tripulantes será feito mediante inclusão dos respectivos nomes no item Lista de Passageiros dos Avisos de Entrada/Saída, apresentados ao OD, desde que a embarcação esteja autorizada a transportar passageiros.

Os profissionais que realizam o serviço de segurança nas embarcações que trafegam nos rios da Amazônia ocidental, compõem os prestadores de serviço embarcados, sendo extremamente importante para a segurança da embarcação, demais tripulação e passageiros, devido ao grande risco de ataques por parte de facções criminosas que utilizam

a Bacia Amazônica para a realização de crimes transfronteiriços, como tráfego de drogas e armas; por este motivo, deverão ser lançados nas observações dos Avisos de Entrada/Saída/Despacho e no Livro de Registro de Funcionários, como prestadores de serviço embarcados, a fim de os garantir os direitos trabalhistas, além disso, deverá ser disponibilizado camarote adequado, conforme previsto no Anexo 3-M (Requisitos de Habitabilidade) da NORMAM 202/DPC.

4.8. FERROS E AMARRAÇÃO

Não é permitido lançar ferro em local onde possa ocorrer prejuízo para o tráfego de embarcações, nas proximidades de portos e terminais, vias navegáveis e em locais que possam causar danos às canalizações e cabos submarinos. Na ocorrência de desrespeito a esta regra, o infrator estará sujeito, além das penalidades previstas, a reparar os danos ou prejuízos causados.

Os navios mercantes somente poderão trafegar, nas águas interiores da área de jurisdição da CFAOC, com dois ferros operando normalmente.

As embarcações, quando em movimento para atracação nos portos, deverão manter um dos ferros fora do escovém, acima da linha de flutuação, com possibilidade de ser largado em caso de emergência.

4.9. TRANSPORTE DE MATERIAL E PESSOAL

Somente as embarcações de pequeno porte, autorizadas pela Capitania, poderão trafegar entre navios mercantes (fundeados, atracados ou sob máquinas) e pontos de terra, para transporte de pessoal e material. O embarque e o desembarque em terra somente poderão ser efetuados em um dos pontos fiscais, em obediência à regulamentação da Agência Nacional de Vigilância Sanitária (ANVISA), Receita Federal e Polícia Federal.

4.10. REPAROS

É proibido ao navio, quando atracado, reparo que o impossibilite de manobrar, salvo em situação especial e desde que obtida a concordância da Administração do Porto ou Terminal. A movimentação de navios de ou para área de fundeio, quando impossibilitados de manobrarem com seus próprios recursos, deverá ser executada utilizando dispositivo

especial dos rebocadores, adequado à situação de rebocado sem propulsão.

4.11. LIBERAÇÃO DE EMBARCAÇÕES APREENDIDAS:

As liberações das embarcações apreendidas serão efetuadas após sanadas e verificadas todas as não conformidades que ensejaram a apreensão da embarcação nesta Capitania Fluvial ou em qualquer terminal portuário público ou privado, Marinas, ou qualquer localidade na qual a embarcação esteja apreendida por meio do fiel depositário.

SEÇÃO II

SERVIÇO DE REBOCADORES

4.12. CONDIÇÕES DE USO DE REBOCADORES (USO OBRIGATÓRIO E FACULTATIVO)

O emprego de empurradores é obrigatório nos portos e terminais da jurisdição da CFAOC e OM subordinadas para embarcações acima de 2.000 TPB.

Somente em casos excepcionais, em que o Capitão dos Portos tenha sido consultado previamente pelos práticos da Zona de Praticagem 02 (Itacoatiara-Tabatinga), com antecedência mínima de 72 h do início da manobra, poderá ser dispensada a utilização de rebocadores para manobra de embarcações acima de 2.000 TPB.

A referência utilizada para a definição da quantidade necessária de “BOLLARD PULL” para cada manobra, em cada Terminal Portuário, é a publicação *Tug Use in Port - 4th Edition: A Practical Guide*, que não entra no mérito do mínimo de capacidade que cada rebocador deve ter, listando apenas o total de BP dos rebocadores. Ainda assim, por questões de segurança e após ouvida a comunidade marítima/fluvial local, não será admitido a utilização de rebocadores com BP menor do que 50. Na perspectiva de avaliação de riscos, considera-se inaceitável o risco de avaria de um rebocador de maior potência, restando disponível apenas aquele com menos de 50 BP. Tal situação impossibilitaria a realização da manobra, podendo mesmo causar um acidente com grandes impactos para pessoas, estruturas ou meio ambiente.

4.12.1. REQUISITOS PARA OPERAR

Todas as embarcações classificadas quanto ao serviço e/ou atividade como rebocadores, com potência instalada superior a 300HP, deverão possuir o CERTIFICADO DE

TRAÇÃO ESTÁTICA LONGITUDINAL, homologado pela DPC, de acordo com instruções específicas. Os rebocadores serão reconhecidos pelos valores nominais constantes desse Certificado.

Os rebocadores com potência instalada igual ou inferior a 300HP não terão necessidade de possuir o CERTIFICADO DE TRAÇÃO ESTÁTICA LONGITUDINAL. Eles serão reconhecidos pelo “BOLLARD PULL” estimado, isto é, utilizando a regra prática de correspondência de uma tonelada métrica de força de tração para cada 100HP de potência do motor.

Para efeito de segurança da navegação, os rebocadores citados no subitem anterior somente poderão ser empregados em operação de reboque de embarcações de cabotagem e apoio marítimo, caso possuam o referido Certificado de Tração Estática, homologado pela DPC.

Além dos citados acima, deverá ser observado o preconizado no capítulo 3 da NORMAM-204/DPC.

4.12.2. SITUAÇÕES DE MAIOR RISCO

Para situações em que se vislumbra maior risco às manobras deverá ser feito um planejamento prévio com as entidades envolvidas, armador ou seu representante, Autoridade Portuária, praticagem e CFAOC, visando ao correto delineamento das ações para reduzir tais riscos.

4.12.3. RECOMENDAÇÕES SOBRE TIPO E MÉTODO DE EMPREGO DE REBOCADORES

As embarcações que possuem “BOW THRUSTER” e/ou “STERN THRUSTER” em perfeitas condições de funcionamento poderão reduzir os valores requeridos de “BOLLARD PULL” em função do dobro dos valores nominais das potências dos seus dispositivos orgânicos, seguindo-se a regra prática de correspondência (subtrai-se do “BOLLARD PULL” requerido, o dobro da potência do “THRUSTER”, dividido por 100).

Os Comandantes das embarcações, assessorados pelos práticos, escolherão o tipo de dispositivo de reboque e o número de rebocadores a serem empregados em todas as manobras nos portos da jurisdição da CFAOC e OM subordinadas. Deverão, entretanto, observar o número mínimo recomendado de rebocadores para cada Terminal, podendo ser consultada a publicação *TUG USE IN PORT - 4th Edition*, do Captain Henk Hensen – The

Nautical Institute, referência sobre o assunto.

Caberá ao armador, seu preposto, ou Agente Marítimo requisitar os rebocadores necessários às manobras a serem efetuadas.

Os cabos de reboque e outros materiais a serem utilizados nas manobras com os rebocadores deverão ser adequados aos requisitos de segurança para a manobra. O seu fornecimento deverá ser resultado de acordo entre o contratante, armador ou agente, e o contratado, empresa de rebocadores.

Ao Comandante do navio caberá a decisão final quanto à utilização dos materiais adequados à manobra e dispositivos.

4.12.4. SITUAÇÕES DE FORÇA MAIOR

Em caso de força maior, o Capitão dos Portos ou o Agente poderá autorizar manobras fora das regras estabelecidas por esta norma, por meio de requerimento do armador ou responsável pela embarcação, com a concordância do Comandante. A autorização que será concedida, tendo sempre em vista as condições mínimas de segurança da navegação, não eximirá seus requerentes, ou seja, armador, agente marítimo, seu executante e o Comandante, de suas responsabilidades legais.

Entende-se como força maior, neste caso, as situações em que não haja disponibilidade de rebocadores, ou a quantidade ou “BOLLARD PULL” existentes sejam inferiores ao desejável, por motivos que não se possam evitar ou impedir.

Quando, em caso de força maior, for solicitado pelo armador ou responsável pela embarcação e pela Administração Portuária a manobra de navio fora dos procedimentos usuais, para atracação ou desatracação de navio em berço não plenamente adequado ao seu porte, o Capitão dos Portos, ao decidir pela autorização, avaliará a necessidade de que sejam tomadas medidas de segurança complementares, inclusive o emprego de maior número de rebocadores do que o previsto, devendo, neste caso, o Comandante da embarcação e a Autoridade Portuária apresentarem o plano ou croqui para a execução da manobra, assinando Termo de Responsabilidade específico para cada caso.

4.12.5. DISPOSIÇÕES COMPLEMENTARES

Nenhum Comandante autorizará uma manobra com o navio, sob seu comando e responsabilidade, se não estiver convicto de que estão resguardadas as condições

satisfatórias de segurança da navegação.

Recomenda-se que o Comandante troque informações prévias com a praticagem e/ou com os mestres dos rebocadores sobre a manobra a ser realizada, as características da bacia de evolução e as características do próprio navio.

A Força de Tração Estática Longitudinal (BOLLARD PULL) dos rebocadores será medida e atestada conforme instruções específicas baixadas pela Diretoria de Portos e Costas (DPC).

O Anexo 4-A apresenta as empresas de rebocadores, com seus respectivos endereços e telefones, existentes na área de jurisdição desta Capitania Fluvial.

É recomendável, para a segurança das manobras de atracação em todos os portos/terminais, a existência de lanchas ágeis de apoio, confiáveis em potência e manobrabilidade, para conduzirem rapidamente os cabos de amarração dos navios para os "Dolphins", evitando que a demora na passagem das espias possa atrapalhar ou até abortar a manobra.

Em todas as manobras de atracação e desatracação em portos/terminais, é obrigatório o uso de comunicações em VHF entre o navio, o cais e as lanchas de apoio, caso existam, para alar as espias.

SEÇÃO III
SERVIÇO DE PRATICAGEM

4.13. PROPÓSITO

Estabelecer os procedimentos complementares à NORMAM-311/DPC, para o controle, dentre outros aspectos, da qualificação dos Praticantes de Práticos, da manutenção da habilitação de Práticos, bem como dar conhecimento das características da ZP-02 (Itacoatiara-Tabatinga).

4.13.1. SERVIÇO DE PRATICAGEM

a) Consiste no conjunto de atividades profissionais de assessoria ao Comandante, requeridos por força de peculiaridades locais, que dificultem a livre e segura movimentação da embarcação e é constituído do Prático, da Lancha de Prático e da Atalaia (Estação de Praticagem).

b) Essa assessoria ocorre durante a execução de faina de praticagem que envolve a realização de manobras de praticagem e/ou navegação de praticagem assim definidas:

I) Manobras de praticagem: são as manobras de atracar/desatracar, fundear/suspender, amarrar/largar a boia, entrar/sair de dique/carreira e alar ao cais, quando executadas com assessoria do prático.

II) Navegação de praticagem: é a navegação realizada no interior de uma ZP com assessoria de um ou mais práticos. Consiste no conjunto de atividades profissionais de assessoria ao Comandante, requeridos por força de peculiaridades locais, que dificultem a livre e segura movimentação da embarcação e é constituído do prático, da lancha de prático e da atalaia (estação de praticagem).

4.13.2. CARACTERÍSTICAS, ORGANIZAÇÃO DO SERVIÇO DAS ZP DA ÁREA DE JURISDIÇÃO E NÚMERO DE PRÁTICOS NECESSÁRIOS PARA EXECUÇÃO DAS FAINAS DE PRATICAGEM

A ZP-02 compreende a área que se estende de Itacoatiara até Tabatinga, nas quais estão localizados os terminais da Hermasa, Terminais Fluviais do Brasil, Terminal Portuário Novo Remanso, Porto Público de Manaus (compreende o Terminal do Roadway e o Terminal Cais das Duas Torres), Terminal Chibatão, Superterminais, Terminal Moageira, Terminal TSOL e Terminal Cimento Vencemos, abrangendo a jurisdição da CFAOC, da Agência Fluvial de Itacoatiara e da Agência Fluvial de Tefé, além da Capitania Fluvial de Tabatinga (não subordinada à CFAOC), e inclui os rios Amazonas, Solimões e Negro, bem como seus afluentes.

4.13.3. NÚMERO DE PRÁTICOS NECESSÁRIOS A REALIZAÇÃO DAS FAINAS DE PRATICAGEM

As fainas de navegação de praticagem na ZP-02 requerem a assistência de, no mínimo, dois (2) práticos, tendo em vista as distâncias envolvidas em todos os trechos: Manaus (AM)-Itacoatiara (AM); Manaus (AM)-Coari (AM) e Manaus (AM)-Tabatinga (AM).

4.13.4. CONDIÇÕES MÍNIMAS PARA ALOJAMENTO E CONFORTO TÉRMICO DOS PRÁTICOS A BORDO

Os comandantes de navios, quando em fainas de praticagem na área de jurisdição da CFAOC e suas Agências subordinadas, devem garantir que existam instalações de alojamento adequadas e com o devido conforto térmico para os Práticos a bordo. A

temperatura passadiço e no local de repouso do prático deverá estar dentro do limite de 21° C a 26° C.

4.13.5. PROCEDIMENTOS DIVERSOS

a) As embarcações deverão içar nos mastros os sinais de “Chamada de Prático” e “Calado do Navio”, segundo o Código Internacional de Sinais (CIS), enquanto aguardam a chegada do Prático, fundeadas ou sob máquinas, no ponto de espera de Prático. Após o embarque, obrigatoriamente, o Sinal de “Prático a Bordo” deverá ser içado, como estabelecido no CIS.

b) Os canais VHF 11 e 78 são de uso preferencial dos Práticos durante as manobras.

c) Providências a serem realizadas pelo prático(s):

I) Apresentar-se ao Comandante e solicitar as informações do “Cartão de Informações ao Prático” (Pilot Card), contido no Anexo 4-B, para tomar conhecimento das características de máquinas e de manobrabilidade do navio, sendo o Comandante obrigado a fornecê-lo. Os Agentes Marítimos e de Navegação deverão manter os Comandantes de navios informados sobre esta determinação do Agente da Autoridade Marítima, enviando ao navio, com a devida antecedência, o modelo do “Pilot Card”.

II) Apresentar ao Comandante do navio a sua intenção de manobra, informando as peculiaridades dos trechos a serem navegados.

III) Verificar as cartas náuticas.

IV) Checar os itens da Lista de Verificação do Prático contidas no Anexo 4-C.

V) De posse do “Pilot Card”, os práticos escalados para a realização da faina de praticagem deverão preencher os dados porventura ainda não lançados. Caso haja desacordo com o previsto no item 3.2.2 desta Norma, deficiência de ordem técnica em sistemas e equipamentos, bem como irregularidades ocorridas ou observadas que comprometam a faina de praticagem, a segurança da navegação, a salvaguarda da vida humana no mar e a prevenção da poluição ambiental por parte das embarcações, plataformas e suas instalações de apoio, os práticos deverão comunicá-las à Capitania ou às Agências subordinadas de modo que a faina de praticagem somente tenha início com a autorização do Agente da Autoridade Marítima.

d) Tomar todas as precauções constantes no Item 2.34 da NORMAM 311/DPC, quanto à impossibilidade de desembarque de prático.

4.14. ESCALA ÚNICA DE RODÍZIO PARA PRÁTICOS

a) O Representante Único do Serviço de Praticagem da ZP-02 junto ao Capitão dos Portos da Amazônia Ocidental ("Representante") será responsável pela elaboração e controle da Escala de Rodízio Única de Serviço de Prático, de acordo com os itens 2.26 e 2.27 da NORMAM-311/DPC, sendo que tal responsabilidade ficará a cargo de um prático, que será escolhido, conforme item 1.20 da NORMAM 311/DPC, e nomeado por Portaria desta Capitania Fluvial.

b) A Representante pela elaboração e controle da Escala de Rodízio Única de Serviço de Prático ("Escala"), nos meses supracitados, compete às seguintes tarefas:

I) Enviar a "Escala" à Capitania Fluvial da Amazônia Ocidental (CFAOC) mensalmente, com cinco (5) dias úteis de antecedência da entrada em vigor de acordo com o item 2.27 da NORMAM-311/DPC, por meio do e-mail (cfaoc.secom@marinha.mil.br);

II) Discriminar na "Escala", obrigatoriamente, os Práticos que estão em período de escala e em período de Indisponibilidade, de acordo o item 2.26 da NORMAM-311/DPC;

III) Participar tempestivamente eventuais alterações na "Escala", para ratificação da CFAOC, de acordo com o item 2.27 da NORMAM-311/DPC;

IV) Comunicar tempestivamente, por escrito, à CFAOC os casos de manobras realizadas por Práticos em condição de fadiga, por descumprimento das regras gerais, constantes no item 2.27 da NORMAM-311/DPC; e

V) Comunicar tempestivamente, por escrito, à CFAOC o descumprimento dos números mínimos de manobras estabelecidos, conforme descrimina quantitativamente no Anexo 2-F da NORMAM-311/DPC e qualitativamente no item 4.19.2 desta Norma.

c) A Escala de Rodízio será definida por meio da Portaria, assinada pelo Capitão dos Portos, após reunião ou Ofício com a concordância das Empresas de Praticagem da ZP-02.

d) A Escala de Rodízio Única (ERU) da Zona de Praticagem ZP-02 será composta, diariamente, por 19 (dezenove) Práticos "em Serviço" e por 02 (dois) Práticos "em Prontidão".

e) O tempo máximo de atendimento para que um Prático "em Prontidão" se apresente à atalaia, no caso de seu acionamento pelo RUSP, será de 12 horas. Tal acionamento deverá ser formalmente informado em até 24 horas após o ocorrido.

f) Estão estabelecidos os seguintes procedimentos acordados entre as empresas de

praticagem, a saber:

I) A “Escala” funcionará de acordo com o contido nas regras gerais estabelecidas nesta Norma;

II) Um navio que se destine à Tabatinga será escalado para a empresa de praticagem, que estiver na vez da rodada, que contemple este trecho de navegação, iniciando seu atendimento desde Itacoatiara até Tabatinga e vice-versa, não contando este serviço como sendo da escala de Itacoatiara, mas de Tabatinga;

III) O mesmo procedimento do inciso anterior será observado quanto à escala de Coari, ou seja, quando navios de Gás Liquefeito de Petróleo (GLP) ou navios petroleiros forem requisitados, seguirão a rodada do trecho de Coari, não interferindo na escala de Itacoatiara, mesmo com os navios de GLP entrando na ZP-02;

IV) A escala de Itacoatiara será atendida de acordo com a rodada estipulada, sempre em grau de preferência abaixo das escalas de Tabatinga e Coari, respectivamente. Nos casos em que navios petroleiros forem requisitados no trecho Itacoatiara x Manaus e, posteriormente, no trecho Manaus x Coari, deverá ser efetuada nova distribuição do serviço, de acordo com a escala de Coari;

V) As requisições dos serviços de praticagem serão recebidas nos centros de recebimento de requisições das empresas de praticagem, cabendo a coordenação desses serviços, junto à CFAOC, ao “Representante”;

VI) Cópias de todas as requisições serão enviadas pelo “Representante” à outra empresa de praticagem, via fax ou correspondência eletrônica, imediatamente após o seu recebimento, para efetiva conferência, com o propósito de manter a total transparência e controle da “Escala”;

VII) O controle dos serviços de praticagem seguirá a cronologia dos ETA em Itacoatiara, quando da entrada na ZP-02, sendo distribuídos com antecedência de 24 horas em relação ao ETA em Itacoatiara. Caso haja uma informação adicional no período anterior às 24 horas, esta deverá ser disseminada, imediatamente, como forma de previsão e facilitação de logística e programação;

VIII) O “Representante”, ao cruzar às 24 horas para o ETA em Itacoatiara e após ter sido escalada a empresa de praticagem que atenderá o navio, deverá informar à Agência Requisitante quanto a esse procedimento, ficando esta ciente de qual empresa de praticagem atenderá o seu navio;

IX) Navios que, por algum problema, encaminhem requisições fora do prazo, seguirão o procedimento supracitado, acompanhando a rodada da “Escala”;

X) As alterações ocorridas no ETA de navio, com menos de 24 horas de antecedência, para o qual já tenha sido designada a empresa de praticagem para a realização do pertinente serviço, não modificará a rodada, ficando o atendimento a cargo da empresa já escalada;

XI) Os navios petroleiros terão como início de sua faina para Coari a data de sua requisição para viagem;

XII) Os navios de GLP que escalarem MANAUS/REAM, em seu regresso, após terem empreendido viagem a Coari, seguirão o mesmo procedimento do inciso anterior, caracterizando o atendimento pela empresa de praticagem que estiver na vez da rodada para um novo serviço. Caso esta atracação seja somente uma escalada em Manaus, seguindo depois para Itacoatiara, o atendimento continuará com a empresa de praticagem;

XIII) O atendimento dos navios só será efetivado quando a requisição para os serviços for solicitada documentalmente, via fax e/ou correspondência eletrônica, com o intuito de manter a transparência dos procedimentos e evitar possíveis erros e omissões;

XIV) Caso seja constatada falta de Práticos de uma das empresas, devidamente comprovada, para o atendimento do serviço requisitado, a situação será adaptada pelo “Representante” para a solução do problema, visando não comprometer o atendimento na ZP-02, respeitando a essencialidade do serviço, não sendo necessária a compensação para estes casos. A CFAOC deverá ser informada tempestivamente sobre tais ocorrências pelo “Representante”;

XV) O controle das rodadas acima descrito será realizado pelo “Representante”, que informará no corpo da requisição a rodada correspondente dos navios atendidos, sendo identificada em qual rodada se encontra, conforme Portaria de Escala de Rodízio em vigor;

XVI) A Atalaia de Itacoatiara do “Representante” da praticagem da ZP-02 junto ao Capitão dos Portos da Amazônia Ocidental monitorará, 24 horas por dia, o movimento dos navios, coordenando o serviço quanto à segurança do embarque/desembarque naquele ponto de troca de Práticos, bem como fornecendo e recebendo todas as informações pertinentes à plena execução dos serviços de praticagem que se fizerem necessários;

XVII) Se o “Representante” manifestar o desejo de ser dispensado do serviço em favor do responsável anterior, isto poderá ser feito, desde que haja a concordância das

empresas de praticagem. Tal procedimento deverá ser apresentado, por escrito, para aprovação do Capitão dos Portos da Amazônia Ocidental, com antecedência mínima de cinco dias úteis da data prevista para a mudança de responsável pela citada tarefa; e

XVIII) Todas as manobras serão contabilizadas na “Escala”, para o acompanhamento da manutenção da habilitação e da não ocorrência de fadiga, de acordo com os itens 2.26 e 2.27 da NORMAM-311/DPC.

g) Toda e qualquer solicitação de serviço, que implique na alteração da “Escala” entre as empresas, será resolvida da mesma maneira que o item da alínea acima.

h) A qualquer tempo, as empresas de praticagem poderão propor alterações aos procedimentos e normas, devidamente acordadas entre as partes, desde que atendam aos requisitos de disponibilidade ininterrupta do serviço de praticagem, da manutenção da habilitação dos Práticos da ZP-02 e da não ocorrência de fadiga desses profissionais, na execução dos serviços.

i) Os casos omissos ou não abrangidos nesta Norma deverão ser levados à apreciação do Capitão dos Portos da Amazônia Ocidental, ao qual caberá exarar sua decisão para cada caso exposto. Esta decisão será transmitida por escrito para as empresas de praticagem, ao “Representante” e ao Comandante do 9º Distrito Naval.

4.15. OBRIGAÇÕES DO COMANDANTE

Os deveres do Comandante da embarcação com relação ao prático encontram-se relacionados no item 2.30 da NORMAM-311/DPC.

4.16. OBRIGAÇÕES DO PRÁTICO E DO PRATICANTE DE PRÁTICO

4.16.1. COMPETE AO PRÁTICO NO DESEMPENHO DAS SUAS FUNÇÕES

As competências ao prático no desempenho das suas funções encontram-se relacionadas no item 2.28.1 da NORMAM-311/DPC.

4.16.2. COMPETE AO PRATICANTE DE PRÁTICO

As competências ao praticante de prático no desempenho das suas funções encontram-se no item 2.29 da NORMAM-311/DPC.

4.17. IMPRATICABILIDADE

a) O Prático deverá comunicar, imediatamente, à CP/DL/AG qualquer fato ou ocorrência que implique em risco à segurança do tráfego aquaviário, à salvaguarda da vida humana, à preservação do meio ambiente ou à faina de praticagem na ZP-01 e ZP-02, tais como:

I) Condições meteorológicas e situações adversas;

II) Acidentes ou fatos da navegação; ou

III) Deficiências técnicas do navio ou da tripulação.

Essas informações subsidiarão o Capitão dos Portos a declarar a impraticabilidade na ZP-02 por meio de Portaria; autorizando, desta forma, que o Serviço de Praticagem não ocorra, ou impeça a entrada ou saída das embarcações, sem que o prático e/ou a Empresa de Praticagem sejam submetidas às sanções administrativas pertinentes.

4.17.1. DECLARAÇÃO DE IMPRATICABILIDADE

VI) Compete à CP declarar a impraticabilidade da ZP.

VII) A impraticabilidade será total quando condições desfavoráveis desaconselharem a realização de quaisquer fainas de praticagem.

VIII) A impraticabilidade será parcial quando restrições à execução de fainas de praticagem se aplicarem tão somente a determinados locais, embarcações, manobras e/ou navegação de praticagem.

4.17.2. PROCEDIMENTOS PARA DECLARAÇÃO DE IMPRATICABILIDADE

a) A Praticagem, por intermédio do Representante Único do Serviço de Praticagem da ZP-02, deverá comunicar imediatamente o fato ou ocorrência a esta Capitania Fluvial.

b) O Representante Único do Serviço de Praticagem deverá encaminhar, formalmente, a esta Capitania Fluvial um relatório sobre o fato/ocorrência observado.

c) Após avaliação dos fatos/ocorrências, o Capitão dos Portos emitirá um parecer quanto à declaração de impraticabilidade total ou parcial e comunicará, via ofício e/ou correspondência eletrônica, às administrações dos Portos e Terminais, às Agências de navegação, aos Armadores e demais integrantes da Comunidade Marítima e interessados da jurisdição. As embarcações que trafegam na região serão informadas por meio de divulgação

no canal VHF 16, bem como a informação será publicada em Aviso aos Navegantes, caso seja necessário.

d) Em casos de problemas relacionados especificamente a navios e que eventualmente sugiram a determinação de impraticabilidade parcial dessa embarcação, o canal de comunicação pelo qual o fato deverá ser informado à CFAOC será através do telefone do CCCAM (Centro de Coordenação e Controle da Autoridade Marítima), constante do Cap. 1 desta norma, bem como pelo e-mail cfaoc.secom@marinha.mil.br.

4.18. QUALIFICAÇÃO DO PRATICANTE DE PRÁTICO

A qualificação do Praticante de Prático (PRP) seguirá um programa de treinamento estabelecido pela CFAOC, denominado Programa de Qualificação do Praticante de Prático, a ser iniciado imediatamente após a Certificação.

As empresas de praticagem realizarão o treinamento dos PRP, por meio dos Práticos Monitores nomeados por Portaria do Capitão dos Portos, os quais farão uso dos seguintes anexos, a fim de cumprirem a Fase de Treinamento e de Qualificação:

I) **Anexo 4-D** – Sinopse do Módulo Inicial da ZP-02;

II) **Anexo 4-E** – Sumário do Módulo Inicial da ZP-02;

III) **Anexo 4-F** – Guia para Organização do Programa de Qualificação para Praticante de Prático;

IV) **Anexo 4-G** – Programa Mínimo de Estágio de Qualificação do PRP;

V) **Anexo 4-H** – Quadro de Resumo Mensal de Manobras / Singradura Acompanhadas/Realizadas por PRP; e

VI) **Anexo 4-I** - Relatório de Manobra/ Singradura.

O Programa Mínimo de Qualificação para PRP compreende duas fases: a **Fase de Treinamento**, com duração mínima de cinco (5) meses, quando o praticante acompanhará as fainas de praticagem, não cabendo o lançamento de grau das manobras, conforme Anexo 4-I; e a **Fase de Qualificação**, com duração mínima de sete (7) meses, quando o PRP realizará as fainas de praticagem, cabendo, nesta etapa, o lançamento do grau da manobras.

Após a realização do módulo inicial, o Praticante de Prático continuará a fase de treinamento, composta de acompanhamento de manobras a bordo de navios. O Praticante de Prático deverá sempre se apresentar para as manobras com os equipamentos de proteção individuais necessários à manutenção de sua segurança, tais como colete salva-vidas, luvas, sa-

patos antiderrapantes, rádio VHF portátil e, se necessário, Portable Pilot Unit (PPU). Tais equipamentos deverão ser fornecidos pela entidade de praticagem à quais o Praticante de Prático estiver subordinado em cada manobra do estágio.

Após a realização de cada manobra acompanhada, o Praticante de Prático deverá estabelecer um apropriado debate técnico com o Prático responsável, a respeito da manobra de acompanhamento ou executada, para eliminação de dúvidas e sedimentação de conhecimentos.

O Prático Monitor será responsável por acompanhar o andamento do programa e o progresso do Praticante de Prático sob sua monitoria, com supervisão do RUSP.

Durante a fase de qualificação, após cada manobra executada, o Prático responsável assinará o Relatório de Manobra, que atribuirá notas, em escala de um a dez, às diversas fases de manobra executada pelo Praticante de Prático.

Os Relatórios de Manobras serão consolidados no Quadro Resumo Mensal de Manobras, que será encaminhado à CFAOC até o dia 10 do mês subsequente.

4.18.1. EXAME DE HABILITAÇÃO PARA PRÁTICO

O exame habilitação para prático será formulado de acordo com o preconizado no item 2.24 da NORMAM-311/DPC e modelos de Portaria desta Norma (Anexos 4-J e 4-K).

4.19. MANUTENÇÃO DA HABILITAÇÃO DO PRÁTICO

O Plano de Manutenção da Habilitação terá o número mínimo de fainas de praticagem estabelecido no item 2.38 da NORMAM-311/DPC.

O não cumprimento do número de fainas previsto implicará no afastamento temporário do Prático por meio de Portaria que será acompanhado pelo Plano de Recuperação da Habilitação (Anexo 4-L).

4.19.1. PLANO DE MANUTENÇÃO DE HABILITAÇÃO DA ZONA DE PRATICAGEM (ZP-02)

Ficam estabelecidos os seguintes números de fainas por Prático, por quadrimestre, para a manutenção da qualificação nos seguintes trechos:

I) Trecho Manaus/Coari: uma (01) viagem em qualquer sentido; e

II) Trecho Manaus/Itacoatiara: oito (08) viagens em qualquer sentido.

Os trechos constantes das alíneas I e II, acima, levarão em consideração, respectivamente, as fainas realizadas até a localidade de Codajás e Terminal Portuário Novo

Remanso (TPNR), somando-se, desta forma, ao quantitativo mínimo para manutenção da habilitação.

4.19.2. FISCALIZAÇÃO DA ESCALA DE RODÍZIO ÚNICA (ERU)

A CFAOC fará o acompanhamento regular quanto ao cumprimento dos requisitos da ERU, da seguinte forma:

a) Verificação, *in loco*, dos Práticos em efetivo Serviço durante uma faina de praticagem, comparando com aqueles constantes da ERU;

b) Controle do acionamento dos Práticos em Prontidão e as motivações;

c) Controle das solicitações de troca de nomes de Prático em "Período de Escala", a ser formalizada através de modelo padronizado constante do Anexo 4-N, desta Norma.

d) Controle dos Práticos que se mantiveram fora da faixa de tolerância estabelecida pela NORMAM-311/DPC e a identificação mensal dos Práticos que tenham incorrido em fadiga.

As inconformidades eventualmente identificadas serão informadas ao RUSP para devidos esclarecimentos e adequações à ERU.

4.19.3. OBRIGAÇÕES DAS PRATICAGENS DA ZP-01 NA ÁREA DE JURISDIÇÃO DA CFAOC

Para realizar controle efetivo das atividades realizadas pelas Praticagens da ZP-01 na área de jurisdição da Capitania Fluvial da Amazônia Ocidental (CFAOC), que compreende o trecho que se estende do Município de Parintins/AM até o Município de Itacoatiara/AM, as Praticagens da ZP-01 deverão enviar todos os documentos administrativos constantes na NORMAM-311/DPC, incluindo a escala de Serviço para a CFAOC, Agência Fluvial de Parintins e Agência Fluvial de Itacoatiara.

SEÇÃO IV
SEGURANÇA ORGÂNICA

4.20. SEGURANÇA DAS EMBARCAÇÕES CONTRA ASSALTOS, ROUBOS E SIMILARES

Os navegantes devem estar atentos à possibilidade de ocorrência de atos de e roubo à mão armada a bordo das embarcações, quando fundeadas ou atracadas. O "Decálogo de

Segurança" anexo 4-M, desta Norma, que sugere precauções a fim de evitar prejuízos aos navios, embarcações e a integridade física de seus tripulantes.

As autoridades competentes para investigar e coibir os ilícitos penais praticados a bordo dos Navios Mercantes são os órgãos de segurança pública estadual e federal, dentre eles a Polícia Federal.

Na ocorrência de roubo, o Comandante da embarcação deverá fazer um relatório circunstanciado dos acontecimentos e dos procedimentos preventivos adotados, o mais minucioso possível, que conterá a descrição dos supostos criminosos, número e tipo de embarcações usadas e meios utilizados para atingirem o convés. O relatório deverá ser encaminhado à Capitania e Agências com jurisdição sobre o porto, para fins de abertura de Inquérito Administrativo.

São responsáveis pelo Registro Policial da Ocorrência os Comandantes, os proprietários ou os armadores do navio, sendo corresponsável o Agente Marítimo. É necessário que o Vigia Portuário, contratado para o serviço de vigilância do navio, preste depoimento à Autoridade Policial sobre o ocorrido.

4.20.1. SEGURANÇA ARMADA

Os armadores ou seus representantes legais, cujas embarcações navegando, atracadas ou fundeadas, visando à defesa de seus tripulantes e a manutenção dos bens de sua propriedade ou sob sua guarda, poderão, sob sua inteira responsabilidade, contratar empresas credenciadas que ofereçam segurança armada ou empregar equipamentos de detecção de intrusos, tais como alarmes, detectores infravermelho, ou quaisquer outros equipamento de segurança.

a) As escoltas armadas deverão cumprir o previsto no inciso III, do § 3 °, do Art. 1° da Lei n° 7.102/1983, combinado com o inciso I, do Art. 52 da Portaria 3233/2021 do Departamento de Polícia Federal.

b) Os membros das escoltas armadas deverão ser identificados e constar no despacho dos referidos navios/embarcações.

4.21. PRESENÇA DE TRIPULANTES

É obrigatória a presença a bordo de um membro da tripulação nos navios atracados e fundeados, guarnecendo equipamento VHF. A Capitania Fluvial da Amazônia Ocidental e suas Agências subordinadas mantêm escuta permanente no canal 16.

SEÇÃO V

MEIO AMBIENTE

4.22. PRESERVAÇÃO AMBIENTAL

Os portos da área de jurisdição desta Capitania não estão em Área de Proteção Ambiental (APA).

No caso de serem criadas Unidades de Conservação (UC) na área de jurisdição desta CP, deve haver uma avaliação conjunta com o Gestor da UC, por ocasião da criação do Plano de Manejo, no tocante às regras de prevenção à poluição ambiental causada por navios, plataformas e suas instalações de apoio.

4.22.1. COMUNICAÇÃO DE INCIDENTE AMBIENTAL

O derramamento de óleo, derivados ou qualquer outro acidente ambiental, ocorrido de forma acidental ou não, de acordo com o Decreto 4.136/2002, deverá ser imediatamente comunicado à Capitania, Delegacia ou Agência com jurisdição sobre a área, pelos meios de comunicação disponibilizados no item 0201.1 desta Normas. Idêntica comunicação deverá ser feita ao IBAMA e às Secretarias de Meio Ambiente dos Estados e Municípios, além do Centro de Defesa Ambiental da Amazônia da Petrobras (Base – Manaus) e ANP. Além disso, devem-se tomar as medidas descritas no item 0203 desta Norma.

4.22.2. PLANO DE EMERGÊNCIA

Na ocorrência de um incidente com óleo, as embarcações envolvidas executarão seu “Plano de Emergência para Poluição por Óleo”, exigido pela MARPOL 73/78, Anexo I, Regra 26, no artigo 3° da Convenção OPRC 90 e nas Normas da Autoridade Marítima para Embarcações Empregadas na Navegação Interior (NORMAM-202/DPC) Capítulo 5, Seção III, de modo a propiciar uma resposta rápida e adequada a um incidente ocorrido a bordo,

neutralizando, ou minimizando tanto quanto possível, os danos ao meio ambiente hídrico, decorrentes de um derramamento de óleo.

4.22.3. CUIDADOS PARA EVITAR POLUIÇÃO

As embarcações deverão recolher o lixo, conforme determina o seu "Plano de Gerenciamento de Lixo", exigido pela MARPOL 73/78, Anexo V, Regra 9, em recipientes adequados, mantendo-os tampado até sua retirada de bordo. A administração do Porto também deverá ser consultada em relação ao recolhimento de lixo.

As embarcações de passageiros deverão possuir recipientes para lixo, devidamente peados, distribuídos por todos os conveses de passageiros, sendo obrigatório, pelo menos, um em cada bordo.

Não é permitido que recipientes de lixo fiquem dependurados pela borda da embarcação ou acumulados no convés principal onde possam vir a rolar para o rio.

É proibido o lançamento no rio de qualquer substância poluente, durante a estadia do navio no porto. As embarcações deverão utilizar as facilidades portuárias disponíveis. Cumprir fielmente o estabelecido na Lei nº 9.966/2000.

A limpeza de tanques e porões, bem como a retirada de objetos contendo produtos químicos deverão ser executada por empresa legalmente habilitada e com consentimento da Administração do Porto e Secretaria de Estado de Meio Ambiente.

4.22.4. RECEBIMENTO E TRANSFERÊNCIA DE COMBUSTÍVEL

As operações de recebimento e transferência de combustível não destinado à carga deverão obedecer, no que couber, ao previsto neste Capítulo e na Seção I do Capítulo 5 da NORMAM-204-DPC, devendo, ainda, serem mantidos fechados todos os embornais no convés do navio. Nas embarcações regionais e principalmente as empregadas no transporte de passageiros, estas operações deverão ocorrer em fundeio, longe dos terminais e pontos de embarque de passageiros e sem passageiros a bordo.

As empresas que executam operações de fornecimento de combustível deverão credenciar-se como Provedoras de Serviço de Bunkering (operação de fornecimento de combustíveis, por meio de transferência entre embarcações, destinado à propulsão, à operação auxiliar de uma embarcação ou à lubrificação do motor ou de suas respectivas máquinas), solicitando o respectivo cadastramento junto à Diretoria de Portos e Costas.

Nos casos de operações de transferência entre embarcações fundeadas ou atracadas a contrabordo, durante todo o período da operação, além de observar os procedimentos previstos na Seção I do Capítulo 5 da NORMAM-204-DPC, deverá ser realizado o lançamento de BARREIRA DE CONTENÇÃO DE ÓLEO (oil boom) na água, antes do início da operação, em quantidade suficiente que possibilite o seu posicionamento entre as embarcações, no setor da proa ou no setor da popa da embarcação prestadora do serviço, conforme a corrente reinante, de tal forma que a seção de barreira lançada seja mantida em formato de "U", tencionada pela corrente, durante todo o transcorrer da operação.

Durante as fainas de carga, descarga ou abastecimento de derivados de petróleo em terminais, deverá ser empregada barreira de contenção de vazamento pelo terminal, em torno do local de abastecimento, conforme disposto na NORMAM-204/DPC.

As instalações flutuantes (pontões) deverão manter kit SOPEP e barreiras e mantas absorventes de óleo a pronto uso, observando o contido no item 6.6.2 do Capítulo 06 desta Norma.

4.22.5. MERCADORIAS PERIGOSAS

São consideradas mercadorias perigosas todas as substâncias assim classificadas pela Convenção Internacional para Salvaguarda da Vida Humana no Mar - SOLAS-74, como os explosivos, gases, líquidos ou sólidos inflamáveis, substâncias comburentes, peróxidos orgânicos, substâncias venenosas, infecciosas, radioativas e corrosivas. O transporte de mercadorias perigosas obedecerá às normas contidas na Convenção Internacional para Salvaguarda da Vida Humana no Mar - SOLAS-74, e instrumentos decorrentes, como o Código IMDG (International Maritime Dangerous Goods Code), para mercadorias perigosas embaladas e o Código IBC (International Code for the Construction and Equipment of Ships carrying Dangerous Chemicals in Bulk), quando transportadas a granel. Deverão ser observadas as disposições previstas nos instrumentos internacionais mencionados, assim como no Capítulo 5 da NORMAM-202/DPC e demais normas previstas na legislação vigente, no que couber.

4.22.6. MANUTENÇÃO DE DALAS E PORÕES

Todas as embarcações que trafegam nos rios da região amazônica deverão manter as dalas e porões das Praças de Máquinas, casas de bombas AV/AR, etc., totalmente esgotados e isentos de quaisquer misturas oleosas.

As Agências Marítimas deverão informar aos Comandantes dos navios por elas agenciados que estes somente poderão demandar as águas interiores da região amazônica

após o cumprimento do disposto no parágrafo anterior.

4.23. EMBARCAÇÕES QUE CHEGAM AO PORTO

A Capitania, suas Agências subordinadas e empresas de Praticagem deverão ser notificada pelo Comandante da embarcação ou seus Agentes Marítimos, de toda carga perigosa que chegar a um Porto/Terminal, seja para descarga ou em trânsito. Esta comunicação deverá ser feita com 48 horas de antecedência da chegada, de acordo com o previsto na NORMAM-202/DPC, conforme aplicável, acrescidos dos seguintes dados:

I) o nome técnico da mercadoria;

II) a classificação quanto ao IMDG-Code;

II) a quantidade; e

IV) destino e ETA da embarcação.

4.23.1. EMBARCAÇÕES QUE DEIXAM O PORTO

Cópia do Manifesto de Carga, tendo em anexo a "Declaração de Mercadorias Perigosas" (Anexo 5-A da NORMAM-202/DPC, conforme aplicável), deverá ser entregue até 24 horas antes da saída da embarcação à Capitania dos Portos. Para os navios de bandeira brasileira, classificados para o transporte de carga e/ou passageiros, deverá ser emitido o Termo de Responsabilidade previsto no Anexo 5-C (NORMAM-02/DPC).

Todas as alterações no Manifesto de Carga, bem como as confirmações de chegada e saída das embarcações deverão ser informadas por e-mail à Capitania.

4.23.2. TRANSPORTE DE ÁLCOOL, PETRÓLEO E SEUS DERIVADOS

As embarcações com AB maior que 10 que transportam ou armazenem álcool, petróleo e seus derivados na área de jurisdição desta Capitania Fluvial devem cumprir os requisitos estabelecidos na Seção III do Capítulo 5 da NORMAM-202/DPC, como também deverá possuir declaração de conformidade para transporte de petróleo e seus derivados, quando carregar mais de 200 m^3.

Todas as operações de transferência de álcool, petróleo e seus derivados realizadas na área de jurisdição desta Capitania Fluvial devem cumprir os requisitos estabelecidos no Capítulo 6 da NORMAM-204/DPC.

Estas normatizações não se aplicam às instalações flutuantes (pontões) que abastecem as embarcações que trafegam ao longo das hidrovias, já previsto no Item 6.2 desta Norma.

SEÇÃO VI
FISCALIZAÇÃO POR AUTORIDADES NACIONAIS

4.24. ENTRADA DA EMBARCAÇÃO

A visita das autoridades do porto, constituída por fiscais da saúde dos portos, de aduana e imigração, é a primeira exigência a ser atendida pelas embarcações que demandam o porto. Compete ao representante do Armador as providências necessárias para sua realização, antes de ser a embarcação liberada para as operações de carga e descarga, de embarque e desembarque de passageiros.

É proibido às lanchas, que estiverem a serviço do Armador ou Agente de Navegação, atracar em embarcação mercante fundeada, que seja procedente de porto estrangeiro, sem prévia liberação da Receita Federal, Polícia Federal e Saúde dos Portos, conforme consta na NORMAM-204/DPC.

4.24.1. ENTRADA DE EMBARCAÇÃO ESTRANGEIRA DE ESPORTE E/OU RECREIO

Para a entrada de embarcações estrangeiras de esporte e recreio será observado o contido nas Normas da Autoridade Marítima para Amadores, Embarcações de Esporte e/ou Recreio e para Cadastramento e Funcionamento das Marinas, Clubes e Entidades Desportivas Náuticas (NORMAM-211/DPC).

4.24.2. LIVRE PRÁTICA

A Livre Prática "*Free Pratique*" poderá ser solicitada via rádio, ou através de mensagem enviada pelos Agentes de Navegação à Vigilância Sanitária, até 24 horas antes da chegada do navio, e deverá ser realizada nos fundeadouros n° 1 ou n° 3 em Manaus e nas áreas de fundeio para os demais portos da jurisdição, dependendo da carga do navio, conforme especificado no item 0505.1 desta Norma.

4.24.3. QUARENTENA

As embarcações cujas condições sanitárias não forem consideradas satisfatórias ou que forem provenientes de regiões onde esteja ocorrendo surto de doença transmissível deverão permanecer em quarentena no fundeadouro nº 2 em Manaus, conforme especificado no capítulo 5 desta Norma, até serem liberadas pela ANVISA.

4.25. SAÍDA DA EMBARCAÇÃO

As embarcações deverão cumprir o previsto no capítulo 1 da NORMAM 204/DPC.

4.26. PORT STATE CONTROL E FLAG STATE CONTROL

As embarcações nacionais e estrangeiras, por ocasião de suas estadias ou passagens pelos fundeadouros da jurisdição da CFAOC ou quaisquer outros, estarão sujeitas a inspeções pelo Controle do Estado do Porto (*Port State Control*) ou Controle do Estado da Bandeira (*Flag State Control*) e deverão permanecer no local até o término das inspeções.

a) Embarcações estrangeiras

As embarcações estrangeiras afretadas, contratadas ou similares, deverão atender o que prescrevem estas normas e as específicas para a permanência de embarcações estrangeiras em Águas Jurisdicionais Brasileiras (AJB) citadas nas NORMAM-203/DPC e NORMAM-204/DPC.

b) Requisito para o início da operação de embarcações de bandeira estrangeira em AJB

Toda embarcação de bandeira estrangeira, com exceção apenas da que for exclusivamente para navegação de longo curso, antes de iniciar a operação deverá obrigatoriamente:

I) Ter sido formalmente autorizado pelo órgão federal competente;

II) Possuir o Atestado de Inscrição Temporário (AIT), à exceção das embarcações estrangeiras em atividade de salvamento; e

III) Estar vinculada a um contrato de arrendamento ou afretamento, celebrado por pessoa física ou jurídica brasileira, seja qual for o prazo desse contrato.

CAPÍTULO 5
PARÂMETROS OPERACIONAIS DO PORTO E PROCEDIMENTOS ESPECIAIS
SEÇÃO I
RESTRIÇÕES OPERACIONAIS

5.1 . CALADO MÁXIMO RECOMENDADO (CALADO OPERACIONAL)

Conduzir uma embarcação com um determinado calado, em local com uma dada profundidade, é fundamentalmente, um problema de navegação, cuja resolução cabe ao Comandante. Para tal, deve munir-se de todas as informações e auxílios possíveis, bem como adotar os procedimentos que a boa técnica recomenda.

Dessa forma, não é suficiente estar com um calado menor que a profundidade de um dado local para nele passar com segurança. Há que ser considerada a velocidade, a largura do canal, a tensa, as condições ambientais e as possíveis alterações de densidade da água, que podem causar variações de calado e/ou alterações na manobrabilidade do navio.

Considerando que as características dos portos nacionais e de seus acessos variam muito, o mesmo ocorrendo com as reações das embarcações em função de suas formas, carga, calado e propulsão, torna-se difícil à fixação de um parâmetro único que estabeleça uma folga mínima segura entre o calado e a profundidade. Assim, nas reuniões técnicas previstas com essa finalidade, são consideradas inúmeras variáveis que permitem recomendar ao navegante um percentual da profundidade, denominado “fator de segurança”, que deverá ser dela abatido, definindo um “calado máximo”.

5.1.1. CALADO MÁXIMO RECOMENDADO NOS TRECHOS DA JURISDIÇÃO

a) Folga Abaixo da Quilha (FAQ)

Considerando que as características das vias navegáveis dos portos e terminais amazônicos e de seus acessos variam muito, o mesmo ocorrendo com as reações das embarcações em função de suas formas, carga, calado e propulsão, a segurança da navegação, com relação à profundidade, pode ser assegurada pela fixação de uma Folga Abaixo da Quilha (FAQ), que garanta, a qualquer tempo, uma margem de segurança adequada para a passagem do navio por uma área considerada crítica. Nos rios da área sob

jurisdição da CFAOC e Agências subordinadas, especificamente nos rios Amazonas, Negro e Solimões, fica estabelecido:

I) 0,5 m como Folga Abaixo da Quilha Mínima (FAQM) a ser observada para navios com cargas a granel.

II) de 0,6 a 1,0 m como Folga Abaixo da Quilha Mínima (FAQM) a ser observada para navios transportando cargas consideradas perigosas e de elevado potencial poluidor, conforme especificado nos itens 4.22.5 desta Norma e Procedimento, que possam provocar danos ao meio ambiente. Essa escala, definida pelo Comandante do Navio, varia conforme o grau de risco envolvido (tripulação sem experiência, equipamentos do navio com baixa confiabilidade, características ambientais e meteorológicas, etc). Quanto maior o risco, mais esse fator se aproxima de 1,0 m e quanto menor o risco, mais ele se aproxima de 0,6 m. Em razão das dificuldades na navegação da região e incertezas envolvidas e considerando o transporte de cargas perigosas, recomenda-se não adotar uma FAQM abaixo 0,9 m.

No que pese a definição de FAQM, Folga Abaixo da Quilha Mínima, ressalta-se que tal parcela será sempre acrescida dos valores correspondentes aos Fatores de Segurança para fins de determinação do CMR – Calado Máximo Recomendado.

b) Estabelecimento de Calado Máximo Recomendado (CMR)

I) O calado máximo de navegação é de responsabilidade de cada Comandante de Navio, que deverá adotar as medidas adequadas a uma navegação segura, respeitada a Folga Abaixo da Quilha Mínima (FAQM) estabelecida; e

II) O CMR para cada trecho considera o valor da profundidade local, a FAQM e o somatório dos fatores de segurança. Nos trechos e áreas portuárias, a divulgação oficial do Calado Máximo Recomendado CMR será feita pela Administração do Porto/Terminal responsável pelo trecho em questão, e no item destas Normas e Procedimentos correspondente ao porto/terminal pertinente, sendo sempre citadas as variações típicas no local.

III) O Calado Máximo Recomendado (CMR), cuja fórmula consta abaixo, será calculado utilizando-se a profundidade local, obtida das publicações náuticas em vigor e corrigidas através das variações dos níveis diários das réguas de medições, subtraindo-se, deste valor, a FAQM e o valor calculado para os Fatores de Segurança (FS).

CMR = P – FAQ
ou
CMR = P – (FAQM + FS)

Onde:
P = profundidade local, corrigida através das variações dos níveis diários e calculada levando-se em conta o Nível de Redução (NR) da Carta Náutica;
FAQ = Folga Abaixo da Quilha, somatório da FAQM e dos Fatores de Segurança (FS).

c) Fatores de Segurança (FS)

O comandante do Navio, visando o cálculo da FAQ, deverá adicionar ao valor da FAQM (0,5 ou 0,6 a 1,0 m) o valor correspondente ao Fator de Segurança (FS), calculado através de variáveis empíricas que caracterizam à Natureza do Fundo, Incertezas de área e Efeito SQUAT, conforme descrição e valores abaixo.

Os cálculos para a determinação dos Fatores de Segurança serão realizados em função do Calado atual do navio, quando se tratar da parcela do efeito Squat, independentemente do trecho em que esteja navegando, e em função da profundidade, quando se tratar da Natureza do Fundo e Incertezas de Área.

I) Natureza do Fundo:

Fundos sólidos, como rocha, tendem a causar maiores danos aos navios, bem como a tornar mais difícil os desencalhes. Em compensação, fundos de lama fluida podem até admitir calados maiores que a profundidade, na ausência de outros fatores de risco (normalmente, camadas de lama fluida de densidade inferior a 1,2 Kg/l não são consideradas nas batimetrias). Os Fatores de Segurança (% do calado) recomendados em função do fundo são:

Lama macia – 2,6%;
Areia – 5,0%; e
Pedra – 8,0%.

Para o cálculo deste Fator de Segurança, deve-se observar as publicações náuticas em vigor, onde são evidenciados os locais com existência de pedras, assim como as publicações periódicas em "Avisos aos Navegantes" ou “Avisos-Rádio Náuticos”, a menos que haja análise de fundo mais recente cujo resultado tenha sido divulgado formalmente pelo Capitão dos Portos.

II) Incertezas da Área

Informações de batimetrias desatualizadas e variações de densidade da água, sejam em razão de chuvas, seja por predominância de rios e movimento dos sedimentos no leito, são fatores que, com base no conhecimento local, devem ser considerados e a eles atribuídos um percentual equivalente à incerteza. Para a área de jurisdição da CFAOC este fator de segurança será de 1,0%.

III) Efeito SQUAT

O deslocamento do navio em águas rasas (até 1,5 vezes o seu calado) causa variações de pressão na massa líquida e afetam a capacidade de governo. Esse fenômeno, denominado efeito SQUAT, é importante para o estabelecimento de um fator de segurança e deve ser considerado em conjunto com a Velocidade. Os seguintes valores aproximados de fator de segurança devem ser considerados:

Velocidade 4 nós – 1,5%;
Velocidade 6 nós – 3,3%;
Velocidade 8 nós – 6,0%; e
Velocidade 10 nós – 9,3%.

Os cálculos para definição desta parcela serão realizados em função do Calado atual do navio, independentemente do trecho em que esteja navegando.

5.1.2. RECOMENDAÇÕES

a) Praticagem

Os Práticos deverão **assessorar** o comandante do navio ao longo de todo trecho, procurando fazer uma navegação com o máximo de segurança, em função do calado, observando a Folga Abaixo da Quilha (FAQ) **estabelecida pelo Comandante** do navio. Quando esta for menor que a FAQM (folga abaixo de quilha mínima) estabelecida no item 5.1.1, recomendada por esta Capitania Fluvial, o Prático deverá alertar o Comandante para o fato.

Caso adotado valor menor que a FAQM, o Prático deverá comunicar o fato ao Capitão dos Portos de maneira imediata, ou assim que possível, que deverá adotar medidas no sentido de investigar quais os motivos que ensejaram tal medida, apontando

responsabilidades, conforme estabelecidas por inquérito administrativo previsto na NORMAM-301/DPC.

Sempre que houver necessidade de sondagens de uma passagem crítica, por lancha, um dos Práticos deverá, obrigatoriamente, permanecer a bordo do navio.

b) Transbordo de Carga

Poucos são os recursos para reduzir o calado quando o navio encontrar um trecho com pouco fundo. O esgoto de água de aguada é proibida nos rios da amazônia. Em tais casos, dentre as providências de apoio a serem solicitadas pelo Comandante ao seu Agente Marítimo, deverá constar obrigatoriamente a necessidade de comunicar aos representantes da Autoridade Marítima da área de jurisdição a necessidade identificada, informando a quantidade e espécie da carga a ser transferida, bem como o nome e características das embarcações para as quais será transferida a carga.

As embarcações envolvidas no transbordo da carga deverão ser regularmente despachadas pela representante de Autoridade Marítima competente e demais autoridades nacionais e as empresas deverão cumprir o previsto na NORMAM-204/DPC.

Em situações normais, os transbordos para balsas deverão ser realizados em áreas portuárias com a devida autorização e apoio do Porto Público ou Privado onde será realizada a operação, sendo necessário comunicar a atividade aos representantes da Autoridade Marítima.

c) Limites operacionais dos Terminais Portuários.

Os limites operacionais dos navios a serem considerados para cada Terminal Portuário, Público ou Privado, são aqueles estabelecidos nas Folhas de Dados de cada um deles, disponíveis para consulta através do endereço eletrônico https://www.marinha.mil.br/cfaoc/.

Ressalta-se que, para fins de viabilidade das manobras de atracação ou desatracação nos referidos Terminais, além de outros parâmetros técnicos estabelecidos, deve-se considerar o Deslocamento (*Displacement*) do navio na condição de carga atual, independentemente do valor de Deslocamento de Projeto desta embarcação, que é aquele previsto na condição de Calado de projeto (calado máximo).

5.2. RESTRIÇÕES DE VELOCIDADE, CRUZAMENTO E ULTRAPASSAGEM

A forma dos canais navegáveis, a profundidade, o tipo de tensa e de margem, afetam o comportamento das embarcações, de modo que a velocidade de trânsito se torna um fator importante para evitar acidentes

Como preconizado no PIANC, o efeito SQUAT depende da velocidade em relação ao fundo. Além disso, o navio sofre também a influência das bordas de um canal, e das embarcações que se cruzam. Dessa forma, o estabelecimento de um fator de segurança para compensar o efeito SQUAT deverá estar relacionado com uma velocidade de evolução da embarcação.

Quando uma embarcação passa próxima à outra, ocorre, também, uma interação hidrodinâmica que afeta a ambas. Desta forma, máxima atenção deve ser dispensada pelos Comandantes das embarcações quando realizando cruzamentos ou ultrapassagens com outras embarcações.

Em função da sinuosidade e demais características intrínsecas dos rios são terminantemente proibidos o uso do piloto automático durante as singraduras nas vias interiores da área de jurisdição.

Outro fator a ser considerado para limitar-se a velocidade de trânsito nas hidrovias refere-se aos possíveis danos que podem ocorrer nas margens e instalações nela localizadas devido às ondas produzidas pelo deslocamento das embarcações.

5.2.1. RESTRIÇÕES DE VELOCIDADE

5.2.2. TRAPICHES, FLUTUANTES, EMBARCAÇÕES E PORTOS ORGANIZADOS

Considerando os possíveis danos que podem ser causados às margens, às embarcações atracadas e às instalações nelas localizadas, é proibida a passagem de embarcações em velocidade superior a cinco nós (velocidade de fundo - VF), em distância inferior a cento e cinquenta metros das margens dos rios, e 5 metros de locais de concentração de trapiches, flutuantes, embarcações e portos organizados.

5.2.3. PETROBRAS NO SOLIMÕES - TSOL

Especial atenção deverá ser observada pelos condutores de embarcações que passarem próximos ao terminal da Petrobras, no rio Solimões - TSOL (próximo ao município de Coari-AM). Os navegantes deverão reduzir ao máximo a velocidade e navegar o mais afastado possível do terminal, preferencialmente próximo à margem esquerda do rio.

5.2.4. CANAIS ESTREITOS, PARANÁS, IGARAPÉS E “FUROS”

Em rios, paranás, igarapés e “furos” de canal estreito, quando a proximidade das margens é inevitável, as embarcações deverão navegar a uma distância mínima de cinquenta (50) metros das margens (quando aplicável) e em velocidade reduzida de no máximo cinco (5) nós, a fim de evitar a deterioração das margens (terras caídas) e possíveis danos as casas flutuantes ou as casas construídas sobre palafitas dos ribeirinhos.

5.3. RESTRIÇÕES DE CRUZAMENTO E ULTRAPASSAGEM

As embarcações navegando em estreitos, furos e paranás de difícil navegação devido aos obstáculos existentes nas respectivas áreas, deverão evitar a ultrapassagem de outras embarcações, reduzindo a velocidade e comunicando àquela que pretende ultrapassar via rádio VHF a sua intenção de manobra. A embarcação de menor porte deverá liberar, se possível, o canal mais profundo para a outra embarcação com maior restrição de manobra.

No caso de cruzamento em situação de rumos opostos, as embarcações, se necessário, devido à diferença de porte entre as mesmas, deverão reduzir a velocidade, mantendo contato rádio e definindo a manobra a ser realizada por ambas.

Na situação de rumos cruzados, deverá ser obedecido o Regulamento Internacional para Evitar Abalroamento no Mar (RIPEAM), com as devidas adaptações para águas interiores, previstas no Capítulo 11 das Normas da Autoridade Marítima para Embarcações Empregadas na Navegação Interior (NORMAM-202/DPC).

5.4. RESTRIÇÕES DE HORÁRIO

Observar o contido na Seção 2 do Capítulo 1.

5.5. RESTRIÇÕES DE PORTE DAS EMBARCAÇÕES

Observar o contido na Seção 2 do Capítulo 1.

5.6. RESTRIÇÕES DE FUNDEIO

5.6.1. ÁREAS DE FUNDEIO PERMITIDO (FUNDEADOUROS)

5.6.1.1. ÁREA DE MANAUS-AM

Na área portuária de Manaus é permitido fundear embarcações nas áreas delimitadas como fundeadouros, contempladas como:

a) Fundeadouro 1 (área de espera para atracação de navios de carga geral),

b) Fundeadouro 2 (área para embarcações em litígio, incluindo quarentena), e

c) Fundeadouro 3, 4, 5 (área de espera para atracação e desgaseificação de navios que transportam derivados de petróleo), especificadas na carta nº 4110, com as coordenadas conforme descrito abaixo:

5.6.1.2. FUNDEADOURO I

PONTO A: Latitude: 03° 07' 08.268''S e Longitude: 060° 03' 44.978''W

PONTO B: Latitude: 03° 07' 21.087''S e Longitude: 060° 03' 54.315''W

PONTO C: Latitude: 03° 07' 48.592''S e Longitude: 060° 02' 50.538''W

PONTO D: Latitude: 03° 08' 01.790''S e Longitude: 060° 03' 04.654''W

5.6.1.3. FUNDEADOURO II

PONTO A: Latitude: 03° 07' 55.520''S e Longitude: 060° 04' 16.320''W

PONTO B: Latitude: 03° 08' 07.080''S e Longitude: 060° 04' 22.800''W

PONTO C: Latitude: 03° 08' 11.690''S e Longitude: 060° 03' 40.790''W

PONTO D: Latitude: 03° 08' 17.520''S e Longitude: 060° 03' 47.920''W

5.6.1.4. FUNDEADOURO III

PONTO A: Latitude: 03° 08' 21.800''S e Longitude: 060° 02' 36.060''W

PONTO B: Latitude: 03° 08' 35.770''S e Longitude: 060° 02' 43.660' 'W

PONTO C: Latitude: 03° 08' 53.520''S e Longitude: 060° 01' 43.140''W

PONTO D: Latitude: 03° 09' 07.780''S e Longitude: 060° 01' 49.840''W

5.6.1.5. FUNDEADOURO IV

PONTO A: Latitude: 03° 10' 11.06''S e Longitude: 059° 59' 58.700''W

PONTO B: Latitude: 03° 10' 29.612''S e Longitude: 060° 00' 09.980''W

PONTO C: Latitude: 03° 10' 33.270''S e Longitude: 059° 59' 09.111''W

PONTO D: Latitude: 03° 10' 54.120''S e Longitude: 059° 59' 17.963''W

5.6.1.6. FUNDEADOURO V

PONTO A: Latitude: 03° 09' 56.340''S e Longitude: 059° 56' 59.820''W

PONTO B: Latitude: 03° 10' 16.610''S e Longitude: 059° 56' 43.150''W

PONTO C: Latitude: 03° 08' 49.630''S e Longitude: 059° 55' 56.420''W

PONTO D: Latitude: 03° 09’ 05.690’’S e Longitude: 059° 55’ 39.040’’W

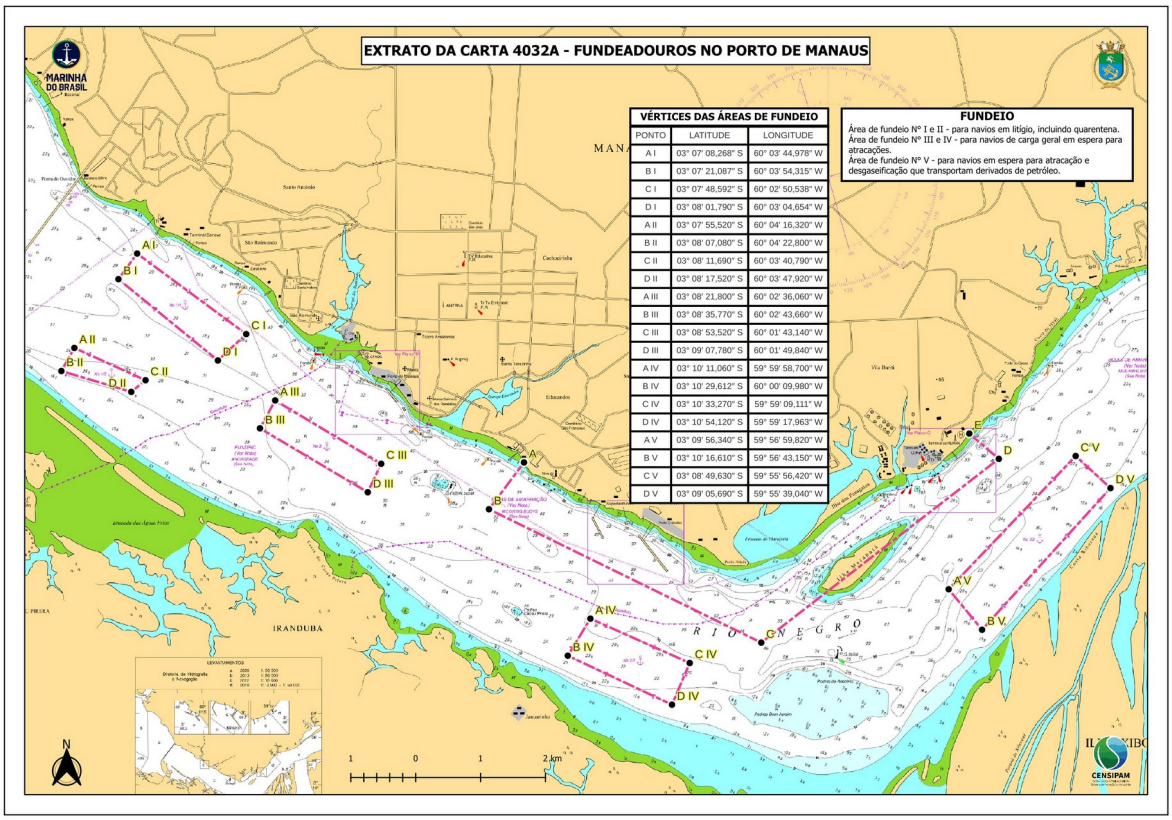

Observação: As operações de transbordo, quando autorizadas, deverão ser realizadas nas áreas previamente estabelecidas pela Capitania.

5.6.2. ÁREA DE ITACOATIARA-AM

A área de fundeio na cidade de Itacoatiara é definida pelas seguintes coordenadas geográficas (Carta Náutica 4106A):

PONTO A Latitude: 03° 09’ 49.20” S e Longitude: 058° 26’ 31.80” W

PONTO B Latitude: 03° 10’ 00.60” S e Longitude: 058° 26’ 02.40” W

PONTO C Latitude: 03° 10’ 18.60” S e Longitude: 058° 25’ 15.00” W

PONTO D: Latitude: 03° 10’ 43.20” S e Longitude: 058° 23’ 57.60” W

PONTO E Latitude: 03° 11' 07.20” S e Longitude: 058° 22’ 28.80” W

PONTO F Latitude: 03° 11’ 45.60” S e Longitude: 058° 20’ 54.00” W

PONTO G Latitude: 03° 12’ 07.20” S e Longitude: 058° 21’ 03.00” W

PONTO H Latitude: 03° 11’ 37.80” S e Longitude: 058° 22’ 38.40” W

PONTO I Latitude: 03° 11’ 12.60” S e Longitude: 058° 24’ 04.80” W

PONTO J Latitude: 03° 10’ 44.40” S e Longitude: 058° 25’ 28.20” W

PONTO K Latitude: 03° 10’ 16.20” S e Longitude: 058° 26’ 14.40” W

PONTO L Latitude: 03° 09’ 59.40” S e Longitude: 058° 26’ 42.00” W

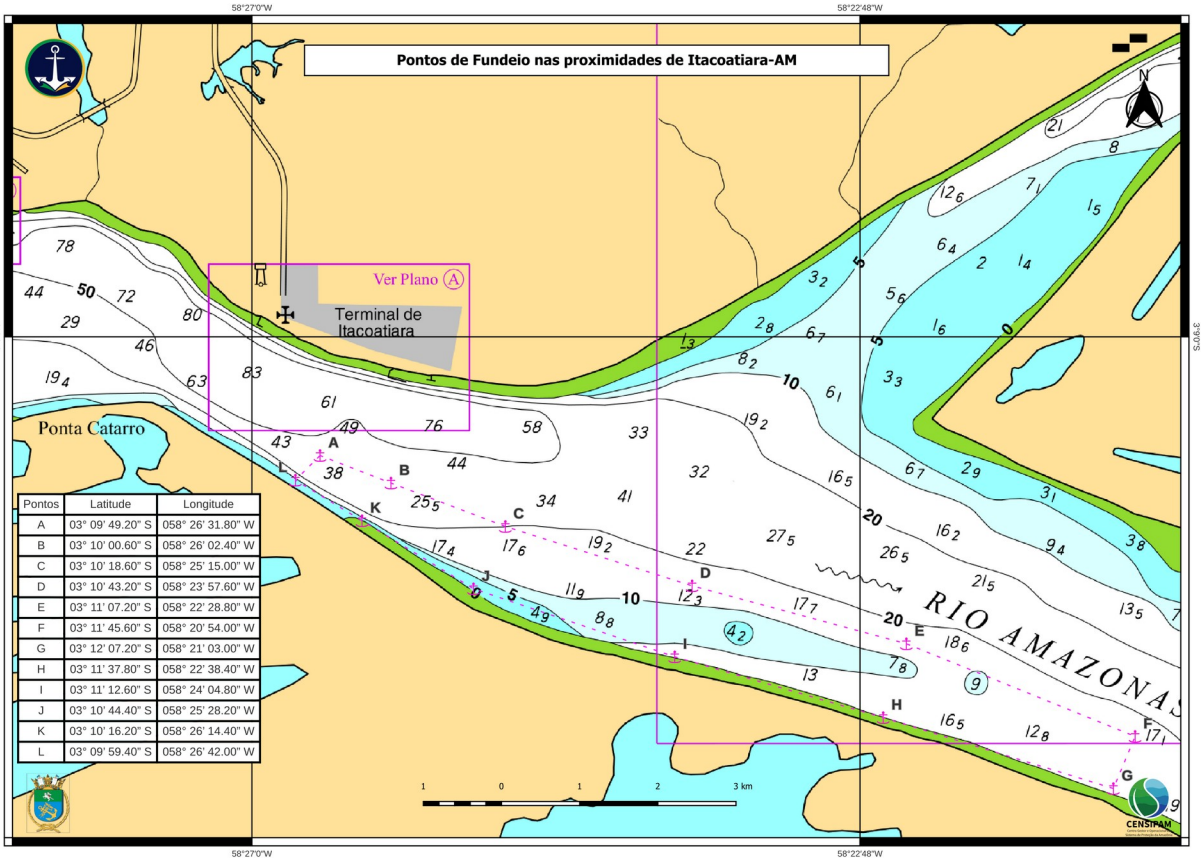

Pontos	Latitude	Longitude
A	03° 09' 49.20" S	058° 26' 31.80" W
B	03° 10' 00.60" S	058° 26' 02.40" W
C	03° 10' 18.60" S	058° 25' 15.00" W
D	03° 10' 43.20" S	058° 23' 57.60" W
E	03° 11' 07.20" S	058° 22' 28.80" W
F	03° 11' 45.60" S	058° 20' 54.00" W
G	03° 12' 07.20" S	058° 21' 03.00" W
H	03° 11' 37.80" S	058° 22' 38.40" W
I	03° 11' 12.60" S	058° 24' 04.80" W
J	03° 10' 44.40" S	058° 25' 28.20" W
K	03° 10' 16.20" S	058° 26' 14.40" W
L	03° 09' 59.40" S	058° 26' 42.00" W

A área de fundeio de Itacoatiara, delimitada pela poligonal descrita acima, atenderá aos navios e Terminais Portuários localizados naquela região, podendo, ainda, em algum ponto específico, ser destinada às operações de transbordo de carga entre navios ou entre navios e balsas. As operações de transbordo de carga dependem de cadastro prévio do Provedor junto à Diretoria de Portos e Costas – DPC, assim como de Autorização de Área pela CFAOC.

5.6.3. ÁREA DE NOVO REMANSO - AM

A área de fundeio na comunidade de Novo Remanso é definida pelas seguintes coordenadas geográficas, **fundeadouros:**

5.6.3.1. FUNDEADOURO I

PONTO A Latitude: 03° 15’ 22.53’’S e Longitude: 059° 04’ 58.80’’W

PONTO B Latitude: 03° 14’ 44.67’’S e Longitude: 059° 03’ 11.90’’W

PONTO C Latitude: 03° 14’ 55.95’’S e Longitude: 059° 03’ 07.60’’W

PONTO D Latitude: 03° 15’ 34.81’’S e Longitude: 059° 04’ 54.49’’W

5.6.3.2. FUNDEADOURO II

PONTO A Latitude: 03° 15’ 12.95’’S e Longitude: 058° 57’ 12.66’’W

PONTO B Latitude: 03° 15’ 44.23’’S e Longitude: 058° 55’ 57.92’’W

PONTO C Latitude: 03° 15’ 55.25’’S e Longitude: 058° 56’ 02.90’’W

PONTO D Latitude: 03° 15’ 24.97’’S e Longitude: 058° 57’ 17.64’’W

5.6.3.3. FUNDEADOURO III

PONTO A Latitude: 03° 15’ 46.25’’S e Longitude: 058° 55’ 53.52’’W

PONTO B Latitude: 03° 16’ 25.56’’S e Longitude: 058° 54’ 42.62’’W

PONTO C Latitude: 03° 16’ 36.96’’S e Longitude: 058° 54’ 48.88’’W

PONTO D Latitude: 03° 15’ 57.65’’S e Longitude: 058° 55’ 59.77’’W

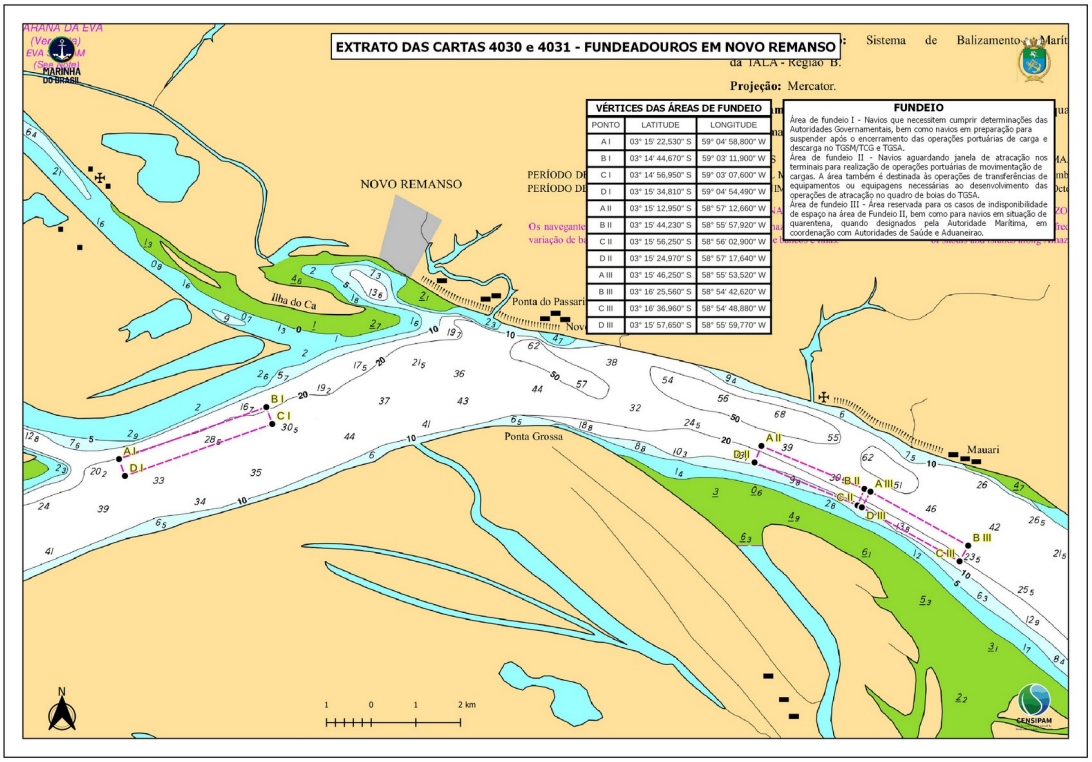

5.6.4. ÁREAS DE FUNDEIO PROIBIDAS

É proibido o fundeio na área delimitada pelas coordenadas contidas na tabela a seguir por se tratarem de áreas para garantir o acesso livre aos Terminais da Moageira (Trigolar), Terminal Super Terminais, Porto de Manaus e o Terminal Chibatão:

PONTO A Latitude: 03° 08’ 52.882’’S e Longitude: 060° 00’ 31.829’’W

PONTO B Latitude: 03° 09’ 16.287’’S e Longitude: 060° 00’ 49.325’’W

PONTO C Latitude: 03° 10’ 23.056’’S e Longitude: 059° 58’ 33.384’’W

PONTO D Latitude: 03° 08’ 51.048’’S e Longitude: 059° 56’ 34.787’’W

PONTO E Latitude: 03° 08’ 38.400’’S e Longitude: 059° 56’ 49.524’’W

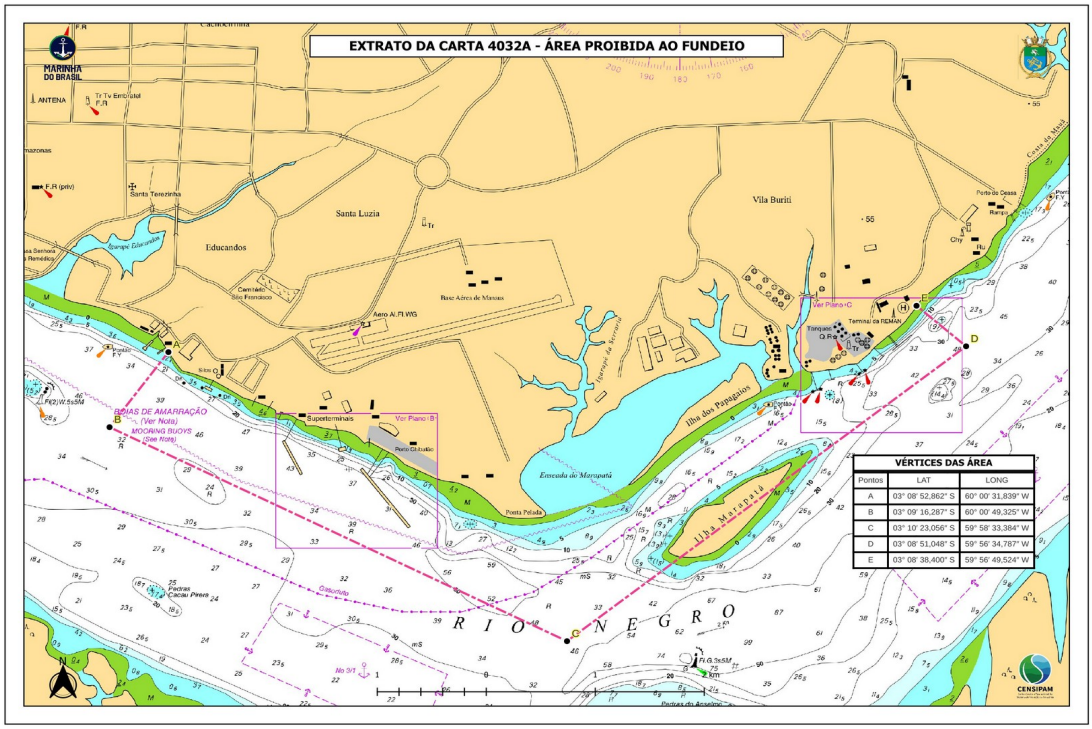

É proibido o fundeio e a abarrancagem de balsas em toda a extensão da Ilha de Marapatá, localizada dentro do Quadro de Manaus-AM. As empresas interessadas deverão apresentar processo de solicitação de implantação de boias de amarração na margem direita do rio Negro.

5.7. RESTRIÇÕES NAS BACIAS DE MANOBRA E OUTRAS RESTRIÇÕES

As bacias de manobras são de uso comum nas áreas de terminais portuários e atracadouros. As acostagens das embarcações nas rampas ou outros locais de embarque e desembarque de passageiros e carga somente será permitida pelo tempo suficiente para os seus embarque e desembarque, ficando proibida a sua permanência no local.

5.8. MONITORAMENTO DAS CONDIÇÕES BATIMÉTRICAS

Deverá ser estabelecido o constante monitoramento das condições batimétricas dos canais de acesso, bacias de evolução e berços, por parte da Autoridade Portuária. Esses valores devem ser mantidos em uma faixa de segurança, tendo como base os Calados Máximos Recomendados (CMR) preestabelecidos.

Para que os parâmetros operacionais originais propostos possam ser mantidos em uso, é necessário verificar periodicamente os níveis batimétricos, e para tanto, a Administração do Porto deverá verificar anualmente as condições batimétricas do porto/terminal sob sua responsabilidade, encaminhando à CFAOC as cópias das medições com os parâmetros encontrados, a fim de subsidiar decisão do Capitão dos Portos quanto à manutenção ou alteração dos CMR.

5.9. PARÂMETROS OPERACIONAIS FORA DA ÁREA DOS PORTOS ORGANIZADOS

5.9.1. RIO MADEIRA

A velocidade máxima permitida, na área compreendida entre o limite de segurança no Rio Madeira, é de 5 nós.

Dimensões máximas operacionais dos comboios no Rio Madeira:

Comprimento: até 150 m, boca: 30 m; e
Calado máximo: Cumprir o determinado no item **5.1.1**.

5.9.2. RIO JURUÁ

Na cheia, acima de Eirunepé, a velocidade do rio varia muito, podendo chegar a 5 nós e dificultando muito a navegação na área e requerendo grande conhecimento e habilidade para garantir uma navegação segura.

Dimensões máximas operacionais dos comboios no Rio Juruá:

- Calado máximo: Cumprir o determinado nos itens 5.1.

a) Características:

CARACTERÍSTICAS				
Situação	**Corrente**	**Batimetria**	**Largura**	**Tráfego**
Cheia	5 nós	7 a 15 m	60 m	Duas (2) faixas de navegação
Vazante	3 nós	3 a 7 m	30 m	Uma (1) faixa de navegação
Calado	Cumprir o determinado no item 5.1.			

b) Fundeadouro:

- Subida: indicado regressar e atracar no Porto de Eirunepé – Lat. 06°40'170"/Long. 069°51'992"; e

- Descida: 06°41'379"/Long. 069°53'428" - margem direita (abarrancagem).

5.10. CALADO AÉREO MÁXIMO ADMITIDO

a) PONTE SOBRE O RIO NEGRO calado aéreo máximo de 45 m.

b) LINHA DE TRANSMISSÃO DE ENERGIA ELÉTRICA NO RIO JURUÁ "1,5 milhas a montante do Porto de Eirunepé, na posição: Lat. 06° 41'150" S e Long. 069° 53' 219" W: calado aéreo máximo de 25 m na cheia.

c) LINHA DE TRANSMISSÃO DE ENERGIA ELÉTRICA SOBRE O PARANÁ DO RAMOS – PARINTINS – AM: na posição: Lat. 02° 41'09.31" S e Long. 056° 42' 15.35" W. Calado aéreo máximo de 23,40 m na cheia.

d) LINHA DE TRANSMISSÃO DE ENERGIA ELÉTRICA SOBRE RIO LIBERDADE – Feijó – Cruzeiro do Sul - AC, na posição: Lat. 07° 47'35.46" S e Long. 072° 1' 7.72" W. Calado aéreo máximo de 25 m na cheia.

e) LINHA DE TRANSMISSÃO DE ENERGIA ELÉTRICA SOBRE RIO LAGOINHA – Feijó – Cruzeiro do Sul - AC, na posição: Lat. 07° 44'13.59" S e Long. 072° 29' 23.58" W. Calado aéreo máximo de 25 m na cheia.

SEÇÃO II

PLATAFORMAS, NAVIOS SONDA, FPSO, FSU, DEMAIS CONSTRUÇÕES E BOIAS DE GRANDE PORTE

5.11. PLATAFORMAS, NAVIOS SONDA, FPSO (*Floating Production Storage and Offloading Unity – Unidade Flutuante de Armazenamento e Transferência)*, FSU (*Floating Storage Unity – Unidade Flutuante de Armazenamento) e* DEMAIS CONSTRUÇÕES QUE VENHAM A ALTERAR SUAS POSIÇÕES NAS ÁGUAS JURISDICIONAIS BRASILEIRAS

5.11.1. ESTABELECIMENTO

O estabelecimento de plataformas de prospecção e produção de petróleo ou gás, de navios-sonda, navios-cisterna, além de gerador de tráfego adicional, constitui obstáculo à navegação, sendo necessário o conhecimento de sua posição exata para divulgação aos navegantes. O mesmo cuidado deve-se ter para o posicionamento de mono boias, poitas e dutos submarinos, a fim de se obter uma navegação segura. Para isto, as companhias responsáveis deverão cumprir o preconizado nas Normas da Autoridade Marítima para Obras, Dragagem, Pesquisa e Lavra de Minerais Sob, Sobre e às Margens das Águas sob Jurisdição Brasileira (NORMAM-303/DPC).

5.11.2. DESLOCAMENTO

Para os deslocamentos de plataformas de prospecção ou produção de petróleo ou gás, navios-sondas, navios cisternas e plataformas de apoio, deverão ser cumpridos o preconizado nas Normas da Autoridade Marítima para Tráfego e Permanência de Embarcações em Águas Jurisdicionais Brasileiras (NORMAM-204/DPC).

5.11.3. MOVIMENTAÇÃO/POSICIONAMENTO

As solicitações de movimentação de embarcações ou plataformas deverão ser efetuadas de acordo com o preconizado na NORMAM-204/DPC.

5.11.4. OPERAÇÕES DE HELICÓPTEROS A BORDO DE PLATAFORMAS E EMBARCAÇÕES

A operação de helicópteros a bordo de embarcações e plataformas somente poderá ser realizada quando o heliponto estiver devidamente homologado, por meio de portaria da Agência Nacional de Aviação Civil e dentro de seu período de validade. O processo de homologação deverá ser cumprido pelo Armador de acordo com a NORMAM-223/DPC.

5.11.5. EMBARCAÇÃO PARA RESGATE

Observar o constante nas Normas da Autoridade Marítima para Homologação de Material (NORMAM-321/DPC).

5.12. RECOMENDAÇÕES PARA FUNDEIO DE PLATAFORMAS E ESTRUTURAS FLUTUANTES EM ÁGUA ABRIGADAS E SEMI ABRIGADAS

Quando do fundeio de plataformas de prospecção e produção de petróleo ou gás, de navios-sonda e navios-cisterna nas proximidades de instalações portuárias, deverá ser informado à CFAOC, ou às Agências subordinadas, conforme a jurisdição, a altura de suas torres em relação ao nível do rio, a fim de evitar interferência com a segurança do tráfego aéreo regional. As autorizações de entrada estarão condicionadas às limitações especificadas após consulta à Força Aérea Brasileira (FAB).

a) Em áreas abrigadas, com grande sensibilidade ambiental, em águas restritas e/ou com grande fluxo de embarcações, as seguintes medidas de segurança para o fundeio de plataformas devem ser adotadas, conforme o caso:

I) As plataformas que fundearão em águas interiores deverão ser apoiadas por rebocadores e embarcações, do tipo e “Bollard Pull” necessário e suficiente visando manter a posição da plataforma ou para o atendimento de casos de emergência, com barreira de contenção instalada, de forma que possa cobrir toda a área em torno da plataforma. No caso dessas plataformas necessitarem atracar deverão permanecer apoiadas por rebocadores, de acordo com o necessário a cada situação, além de permanecerem com barreira de contenção instalada. A CFAOC decidirá sobre o número, o tipo e o método de utilização dos rebocadores, consultando se necessário o prático, o agente de manobra e/ou os demais envolvidos na faina.

II) Quando a plataforma não for propulsada, ou for rebocada por conveniência ou segurança, deverá ser apresentado o Plano de Reboque assinado por Engenheiro Naval, com a respectiva Anotação de Responsabilidade Técnica (ART).

Dependendo da complexidade da manobra, poderá ser exigida pela CFAOC a apresentação de um parecer do Serviço de Praticagem local, a fim de auxiliar na avaliação dos riscos envolvidos.

III) Qualquer movimentação de plataforma deverá contar com anuência prévia da CFAOC.

IV) Quando a entrada/saída, movimentação ou fundeio ocorrer em área do Porto Organizado, deverá ser apresentada a autorização da Autoridade Portuária (AP).

V) Verificar se a infraestrutura portuária suporta as dimensões da unidade que trafegará no canal e bacia de manobra.

VI) Verificar mediante laudo de Engenheiro e teste de tração estática dos cabeços se o cais suporta receber a unidade.

VII) Exigir consulta à Autoridade Aeronáutica, em função do calado aéreo da unidade, quando nas proximidades de aeroportos.

VIII) Exigir plano de fundeio ou plano de amarração, conforme o caso, com ART ou aprovado pela sociedade classificadora.

b) Dependendo de condições especiais de manobra e permanência, o Capitão Fluvial da Amazônia Ocidental poderá, sem prejuízo da segurança da navegação, prevenção da poluição hídrica e ordenamento do tráfego aquaviário, flexibilizar ou adicionar medidas de segurança.

5.13. BOIAS DE GRANDE PORTE

Consideram-se boias de grande porte aquelas com volume superior a 2 m^3 (dois metros cúbicos). As referidas boias representam riscos ao navegante, não somente pelo seu posicionamento, mas também pela possibilidade de garrarem e ficarem à deriva.

5.13.1. IDENTIFICAÇÃO

As boias de grande porte deverão ser identificadas por meio de uma placa com o nome da empresa proprietária, o local de fundeio e a identificação da Capitania.

5.13.2. LANÇAMENTO

O lançamento de boias de grande porte obedecerá ao previsto nas NORMAM-303/DPC. As boias lançadas deverão ser vistoriadas periodicamente por seus proprietários, especialmente no que diz respeito ao aparelho de fundeio, a fim de se evitar que elas garrem. É responsabilidade do proprietário a conservação e manutenção das condições adequadas ao perfeito posicionamento das boias.

5.13.3. PROVIDÊNCIAS NO CASO DE UMA BOIA GARRAR

O navegante ao encontrar uma boia de grande porte à deriva deverá notificar imediatamente ao Comando do 9º Distrito Naval ou à Capitania com jurisdição sobre a área e ao Centro de Hidrografia e Navegação do Noroeste (CHN-9), para divulgação em avisos aos navegantes. As boias de grande porte encontradas à deriva que forem recuperadas pela Marinha serão restituídas ao proprietário, mediante o ressarcimento das despesas realizadas

com o seu reboque, conservação e guarda. O proprietário será notificado para retirar a boia no prazo de 15 (quinze) dias e, caso não a retire, a boia será leiloada conforme a legislação vigente.

5.14. OPERAÇÕES DE MERGULHO

5.14.1. EMPRESAS DE MERGULHO

As empresas de mergulho somente poderão executar suas atividades se estiverem cadastradas na Capitania Fluvial ou Agências, possuindo a Ficha de Cadastro de Empresa de Mergulho e o Certificado de Segurança de Sistemas de Mergulho dentro do prazo de validade, conforme as Normas da Autoridade Marítima para as Atividades Subaquáticas (NORMAM-222/DPC).

a) Para a realização de operações de mergulho na área de jurisdição da CFAOC e Agências subordinadas, além dos procedimentos contidos na NORMAM-222/DPC, deverá ser apresentado pelo representante da empresa de mergulho, com antecedência mínima de 72 horas do pretendido início da operação, um requerimento contendo o seguinte:

I) O planejamento das operações de mergulho e as embarcações envolvidas.

II) O Plano de Contingência para atendimento a situações de emergência, atestado e aprovado por sociedade classificadora credenciada.

III) Indicação da unidade de saúde para encaminhamento de acidentados.

IV) Identificação do supervisor de mergulho, dos mergulhadores e ajudantes de mergulho envolvidos na faina, bem como os seguintes dados:

- Data, horário de início e período da operação.
- Local da realização da faina, citando as coordenadas.
- Permissão da Autoridade Portuária (no caso de área pertencente ao Porto Organizado).
- Motivos da realização da faina.

b) Também deverão ser apresentadas cópias dos seguintes documentos:

I) Carteira de Inscrição e Registro - CIR (na validade), cédula de identidade e CPF de todos os envolvidos na faina.

II)Páginas de identificação do Livro Registro de Mergulho (LRM) de cada mergulhador, devidamente preenchidos e assinados.

III) Atestado de Saúde Ocupacional de cada mergulhador na validade de um ano, assinado por médico credenciado em medicina hiperbárica com identificação do CRM.

IV)Páginas de identificação e registros de trabalhos dos mergulhadores mencionados (Carteira de Trabalho e Previdência Social) ou contrato de prestação dos serviços.

V) Cadastro da Empresa de Mergulho na DPC (autenticada).

VI) Certificado de Vistoria de Equipamentos de Mergulho, com convalidação anual em dia.

VII) Termo de prestação de serviços.

VIII) Documentos e Certificados (conforme cada caso) das embarcações envolvidas na faina.

5.14.2. EMBARCAÇÕES OPERANDO COM MERGULHADORES

Durante as operações de mergulho, as embarcações exibirão a bandeira “ALFA” ou bandeira encarnada com diagonal branca. As demais embarcações deverão se manter afastadas para evitar acidentes com os mergulhadores. Recomenda-se também, que as embarcações se mantenham afastadas de boias e dispositivos flutuantes, já que estes podem indicar a presença de mergulhadores. Especial cuidado deve ser dado a boias encarnadas com diagonal branca.

5.14.3. SÃO OBRIGAÇÕES DO CONTRATANTE

a) Exigir da empresa de mergulho contratada, por meio do instrumento contratual, o fiel cumprimento dos procedimentos estabelecidos nestas Normas.

b) Exigir da empresa de mergulho contratada a manutenção do Certificado De Segurança do Sistema de Mergulho (CSSM), da Ficha de Cadastro da Empresa de Mergulho (FCEM) e da documentação dos componentes da equipe de mergulho na frente de trabalho e dentro do prazo de validade.

c) Disponibilizar todos os meios necessários ao atendimento em casos de emergência, quando solicitado pela empresa de mergulho contratada.

5.14.4. OBRIGAÇÕES DA EMPRESA DE MERGULHO CONTRATADA

I) Garantir à equipe de mergulho os meios adequados para o fiel cumprimento destas Normas;

II) Disponibilizar para a equipe de mergulho, na frente de trabalho, os manuais dos equipamentos, as tabelas de descompressão, o Plano de Operação de Mergulho (POM), o Plano de Contingência (PC), o Programa de Manutenção Planejada (PMP) e demais documentos de uso obrigatório previstos nestas Normas;

III) Indicar por escrito os componentes da equipe de mergulho e suas funções;

IV) Comunicar imediatamente à Capitania e Agência em cuja jurisdição estiver localizada a frente de trabalho, por meio da Comunicação de Acidente de Trabalho (CAT) e de relatório circunstanciado, a ocorrência de acidentes ou situações de risco ocorridas durante as operações de mergulho, com cópia para a caixa postal mergulho@dpc.mar.mil.br;

V) Garantir que os exames médicos dos mergulhadores estejam dentro do prazo de validade;

VI) Garantir os meios necessários para o fiel cumprimento do POM e do PC;

Assegurar que os equipamentos utilizados pela equipe de mergulho estejam em perfeitas condições de funcionamento e devidamente certificados;

VII) Encaminhar a Comunicação de Abertura da Frente de Trabalho (CAFT) e o POM, com a devida antecedência, conforme estabelecido no item 2.7 da NORMAM-222/DPC;

VIII) Efetuar os registros previstos no LRM e na CIR dos mergulhadores;

Manter arquivados, por um período de cinco anos, todos os ROM das operações realizadas pela empresa; e

IX) Manter arquivadas, por um período de cinco anos, todas as gravações de som e imagem captadas por meio de câmera instalada no capacete ou máscara do mergulhador, por ocasião da ocorrência de acidentes ou incidentes durante os mergulhos.

SEÇÃO III

EVENTOS NÁUTICOS ESPECIAIS

5.15. PRINCIPAIS PROCISSÕES MARÍTIMAS E DEMAIS EVENTOS NÁUTICOS NA ÁREA DE JURISDIÇÃO

Na área sob a jurisdição da CFAOC são realizados os seguintes eventos, não tendo datas específicas para sua realização:

- Eventos de cunho folclórico.
- Regatas de embarcações à vela;
- Regatas de embarcações a remo;
- Eventos com moto aquáticas;
- Competições de natação/triátlon; e
- Procissões fluviais religiosas.

5.15.1. INSTRUÇÕES DE CARÁTER GERAL

a) Para a realização de qualquer evento, os organizadores deverão cumprir as orientações contidas no item 1.12.1e Anexo 1-D da NORMAM-211/DPC, quando aplicável.

b) Os interessados deverão comunicar à Capitania Fluvial, com antecedência mínima de 15 dias, a intenção de realizar eventos esportivos náuticos. Tal comunicação deverá conter além do exigido na alínea anterior, pelo menos:

I) Cópia autenticada da documentação das embarcações envolvidas ou original e cópia para autenticação na Capitania (TIE/TIEM/DPP/PRPM); e

II) Cópia autenticada da documentação dos condutores habilitados ou original e cópia para autenticação na Capitania (CHA/CIR/Carteira de Identidade).

5.15.2. INSTRUÇÕES PARA OS ORGANIZADORES

a) Providenciar junto aos órgãos responsáveis competentes para que sejam tomadas as medidas necessárias, com o propósito de garantir a segurança do evento.

b) Deverá ser planejada e definida a evacuação médica de acidentados, desde a sua retirada da água até a remoção para um local preestabelecido em terra.

c) Se o evento interferir com o uso de praias, especialmente se realizado a menos de duzentos (200) metros da linha de base, ou se interferir com qualquer área utilizada por banhistas, as autoridades competentes (Prefeitura Municipal, Corpo de Bombeiros) deverão ser alertadas de modo a que possam ser tomadas as providências necessárias para garantir a integridade física dos frequentadores locais.

d) Conforme o número de embarcações e pessoas envolvidas, dimensões e condições da área de realização deverão ser providas uma ou mais embarcações para apoio ao evento, sendo responsável pelo atendimento aos casos de emergência e para garantir a integridade física dos participantes.

e) As embarcações de apoio e segurança deverão ser guarnecidas por profissionais devidamente habilitados, conforme previsto no respectivo Cartão de Tripulação de Segurança (CTS), Título de Inscrição de Embarcação (TIE) ou Título de Inscrição de Embarcação Miúda (TIEM) e ter características e classificação compatíveis com a área em que operarão, bem como, capacidade para rebocar as embarcações apoiadas.

f) As embarcações de apoio deverão possuir, pelo menos, duas boias circulares ou ferradura, com trinta metros de retinida, coletes salva-vidas suplementares, sinalizadores náuticos, equipamento de comunicações em VHF para contato com equipe de apoio em terra e outros recursos de salvatagem julgados convenientes.

5.15.3. INSTRUÇÕES PARA OS PARTICIPANTES

a) Não entregar a condução da embarcação à pessoa não habilitada.

Não entregar a condução da embarcação à pessoa que tenha ingerido bebida alcoólica.

Cumprir rigorosamente a lotação de passageiros estabelecida na documentação da embarcação.

b) Ter a bordo todo o material de navegação, salvatagem e combate a incêndio que compõe a dotação prevista nas NORMAM e nestas Normas e Procedimentos para a área de navegação onde for realizado o evento, em especial, coletes salva-vidas para todas as pessoas a bordo.

c) Antes de se fazer ao mar, deixar no iate clube ou marina que utiliza ou, ainda, com qualquer pessoa de confiança, relação com o nome de todas as pessoas a bordo, bem como o percurso da viagem que empreenderá.

d) Não movimentar propulsores havendo perigo de acidentes com pessoas na água ou risco de avarias em outras embarcações.

e) Não fazer zigue-zague e nem provocar marolas desnecessárias em áreas restritas ou congestionadas por outras embarcações.

f) Não cortar a proa de outra embarcação em movimento.

g) Não se aproximar demasiadamente de outras embarcações.

h) Manter-se afastado do dispositivo de escolta.

5.15.4. INSTRUÇÕES COMPLEMENTARES PARA EVENTOS TIPO PROCISSÃO FLUVIAL

a) Os organizadores deverão solicitar à Capitania, com no mínimo 30 dias de antecedência, permissão para a realização do evento, cumprindo o preconizado na NORMAM-211/DPC.

b) Balsas que transportam carga não poderão ser improvisadas para realizarem transportes de fiéis (passageiros) em nenhum evento náutico ou procissões fluviais.

c) A critério da CFAOC e Agências poderá ser convocada reunião de coordenação para serem definidos diversos aspectos, dentre eles:

I) O responsável pelo evento.

II) Dados das embarcações de apoio, tendo especial atenção para os detalhes que 3) facilitarão a identificação das mesmas.

III) Estimativa de número de participantes.

IV) Horários (início do evento, concentração, largada e previsão de chegada).

V) Atribuição dos órgãos e meios que cada um disponibilizará.

VI) Definição dos meios de comunicação e divulgação (canal VHF e número dos telefones contato, celulares e fixos).

VII) Divulgação dos principais aspectos relacionados à segurança da navegação, com especial atenção ao contrafluxo e excesso de passageiros.

VIII) Material de salvatagem individual (coletes salva-vidas) e coletivo (balsas rígidas e boias salva-vidas) para todos os participantes embarcados.

IX) Apoio de outras instituições, especialmente, Corpo de Bombeiros e Polícia Militar.

XX) Plano de evacuação médica para o evento.

5.15.5. INSTRUÇÕES PARA A QUEIMA DE FOGOS EM RIOS

A Capitania ou Agência Subordinadas, no uso das atribuições como Agente da Autoridade Marítima, autoriza o fundeio de dispositivos flutuantes, balsas, chatas e outras embarcações para servirem como base de apoio ao lançamento de fogos de artifício, condicionados ao cumprimento dos procedimentos abaixo relacionados, em complemento

ao previsto na NORMAM-211/DPC, a fim de garantir a segurança da navegação, a salvaguarda da vida humana e prevenção da poluição do meio hídrico causado por embarcações.

a) Apresentação de requerimento contendo os documentos abaixo relacionados, com no mínimo 30 dias de antecedência:

I) Memorial descritivo do evento, onde deverá constar o responsável pelo evento, os dados das embarcações empregadas (embarcações de apoio e balsas), procedimentos detalhados de evacuação médica de emergência (incluindo transporte de acidentados desde o rio, por embarcação previamente contratada, para local preestabelecido em terra) e extrato da carta náutica com as posições sugeridas para as embarcações.

II) Memorial descritivo do show pirotécnico, assinado por técnico competente, com firma reconhecida e cópia autenticada do documento de identidade, em duas vias.

III) Certificado de registro da empresa diretamente responsável pela queima de fogos, junto ao Exército Brasileiro.

IV) Documento do responsável pelo evento, declarando a contratação da empresa de queima de fogos para realização do espetáculo ou o respectivo contrato firmado.

V) Autorização da Secretaria municipal de Meio Ambiente.

VI) Autorização do Serviço de Proteção ao Voo do Comando da Aeronáutica.

VII) Autorização do Corpo de Bombeiros.

VIII) Atestado do responsável pelo show de pirotecnia. IX) Documento que ateste a responsabilidade do organizador do evento (responsável) pelo emprego das embarcações a serem utilizadas.

X) Se for o caso, documento do organizador (responsável) que ateste a autorização formal a um eventual coordenador do evento, a fim de tratar do assunto junto à CFAOC.

XI) Termo de responsabilidade assinado pelo responsável pelo evento.

b) A aprovação dependerá das seguintes apreciações da Capitania:

I) Inspeção nos flutuantes e embarcações de apoio pela CFAOC.

II) Distância da orla proposta pelos organizadores do evento, estabelecida em função da potência dos fogos de artifício empregados (normalmente 450 metros).

III) Confirmação do posicionamento das balsas, antes do início da queima de fogos, especialmente no tocante à distância de terra.

IV) Delimitação por boias (com lâmpadas estroboscópicas e espaçadas em 100 metros entre elas) de um perímetro de segurança ao redor das balsas considerando o maior alcance horizontal dos fogos de artifícios em uso.

5.15.6. INSTRUÇÕES PARA EVENTO TIPO FESTA E CONFRATERNIZAÇÃO EM EMBARCAÇÕES

Somente as embarcações classificadas como de apoio ao turismo poderão realizar eventos, festas, confraternizações ou passeios a bordo, condicionados à apresentação dos documentos e cumprimento dos procedimentos abaixo relacionados, a fim de garantir a segurança da navegação, a salvaguarda da vida humana e prevenção da poluição do meio hídrico causado por embarcações:

a) Solicitar pedido de despacho especificamente para o evento;

b) Apresentar plano contemplando os procedimentos operacionais para arrumação de passageiros e local de embarque e desembarque;

c) Apresentar autorização da Autoridade Policial competente;

d) Apresentar declaração do Comandante de que a embarcação não possui carga;

e) Apresentar relação dos tripulantes e pessoal de apoio (extra-rol);

f) Apresentar plano de evacuação médica de emergência (incluindo transporte de acidentados desde o rio, por embarcação previamente contratada, para local preestabelecido em terra);

g) Informar o nome da embarcação de apoio, se for o caso;

h) Apresentar à CFAOC a lista de passageiros, até uma hora após o suspender;

i) O embarque inicial e desembarque final dos passageiros devem ser sempre realizados em cais, píer ou terminal, não podendo ser realizado em praias ou empregando botes de apoio;

j) A prancha de acesso às embarcações de passageiros deve ser provida de balaústres, com, pelo menos, um metro de altura, para prover a necessária segurança aos passageiros e tripulantes;

k) Deverá ser feita uma preleção sucinta sobre normas de segurança, de utilização dos equipamentos de salvatagem e locais de abandono da embarcação, por ocasião do suspender da embarcação;

l) A tripulação deverá estar devidamente uniformizada e portando crachá de identificação com foto, nome e função;

m) Nos eventos com singradura superior a duas horas, deverão ser relacionados todos os passageiros, nominalmente, com identidade e telefone para contato, devendo uma via ser entregue na CFAOC, anexada à lista de passageiros;

n) É responsabilidade do Comandante da embarcação ter a bordo o material de navegação e salvatagem compatível com a singradura a ser realizada e o número de pessoas a bordo;

o) Antes de sair para o passeio ou viagem, o Comandante da embarcação deve tomar conhecimento das previsões meteorológicas disponíveis. Durante o passeio ou viagem, o Comandante deverá estar atento a eventuais sinais de mau tempo, como aumento da intensidade do vento, do estado do rio e a queda acentuada da pressão atmosférica e, caso necessário, proceder ao regresso imediato da embarcação ao porto de origem ou abarrancar em local abrigado e seguro; e

p) Dotar a embarcação com o dobro de combustível previsto para a singradura planejada.

5.15.7. ALUGUEL DE EMBARCAÇÕES E EVENTOS NÁUTICOS

Os procedimentos a serem cumpridos pelas pessoas ou empresas de aluguel de embarcações e organizadores de eventos náuticos estão previstos nas Normas da Autoridade Marítima para Amadores, Embarcações de Esporte e/ou Recreio e para Cadastramento e Funcionamento das Marinas, Clubes e Entidades Desportivas Náuticas (NORMAM-211/DPC).

5.15.8. INSTRUÇÕES COMPLEMENTARES PARA EMPRESAS QUE TRABALHAM COM ALUGUEL DE EMBARCAÇÕES DE ESPORTE E/OU RECREIO

Deverá ser cumprido o preconizado na NORMAM-211/DPC e NORMAM-212/DPC.

5.15.9. COM TRIPULANTE

As empresas que atuam no aluguel de embarcações de esporte e/ou recreio devem tomar todas as providências no tocante ao provimento de todo o material de salvatagem, bem como toda a segurança necessária para aqueles que conduzirão embarcações.

5.15.10. SEM TRIPULANTE

Qualquer embarcação, inclusive veleiro ou moto aquática, somente poderá ser alugada a pessoas que comprovem possuir a devida habilitação. Além disso, toda a

documentação referente à embarcação alugada e respectiva tripulação deverá estar disponível a bordo, para apresentação a inspetores navais, durante as fiscalizações.

5.16. PEDALINHOS, STAND UP, BICICLETAS AQUÁTICAS

5.16.1. PEDALINHOS

No aluguel de pedalinhos, os seguintes procedimentos deverão ser seguidos pela empresa responsável pelos dispositivos:

I) O uso de coletes salva-vidas é obrigatório para todos os usuários.

II) A empresa deverá manter uma embarcação de apoio para prestar socorro aos passageiros dos pedalinhos, em caso de avaria ou emergência.

III) Os pedalinhos só poderão ser utilizados em lagos, lagoas, represas ou águas interiores em que a corrente marítima seja inferior a 0,5 nós.

IV) Os pedalinhos só poderão ser utilizados no período noturno em locais onde haja permanente iluminação.

5.16.2. STAND UP PADDLE

a) Determina-se aos praticantes de “Stand Up Paddle” (SUP):

No aluguel de Stand Up Paddle, os seguintes procedimentos deverão ser seguidos pela empresa responsável pelos dispositivos:

I) O uso de coletes salva-vidas é obrigatório para todos os usuários.

II) A empresa deverá manter uma embarcação de apoio para prestar socorro aos passageiros dos pedalinhos, em caso de avaria ou emergência.

III) Os Stand Up Paddle só poderão ser utilizados nos rios, lagos, lagoas, represas ou águas interiores em que a corrente marítima seja inferior a 3 nós.

IV) Realizar a prática esportiva à luz do dia com regresso às Marinas antes do pôr do sol, tendo em vista que a prancha de SUP não dispõe de iluminação noturna;

V) Navegar em grupo, sempre que possível, e fazendo uso do colete salva-vidas (exceto para praticantes profissionais portando Documento de Identidade e Carteira da Federação de Stand Up Paddle da região e fazendo uso de lancha de apoio), a fim de evitar a obstrução do canal para as demais embarcações e salvaguardar o praticante de SUP;

VI) Realizar as travessias de rios e canais sempre na perpendicular, a fim de navegar na menor distância entre as margens;

VII) Respeitar os limites impostos para a prática esportiva junto às Áreas de Segurança, conforme item 1.8.1 da NORMAM-211/DPC, bem como os portos em atividades portuárias, os Terminais de Uso Privado (TUP) e as Estações de Transbordo de Cargas (ETC); e

VIII) Ao se aproximar das margens, ter atenção aos banhistas e demais embarcações em trânsito.

b) Determina-se aos condutores das embarcações que passem a uma distância segura e velocidade compatível, conforme nos itens 1.8 e 1.9 da NORMAM-211/DPC, a fim de produzir pouco "banzeiro" aos praticantes de Stand Up Paddle.

c) Determina-se às marinas, clubes, entidades desportivas náuticas, estabelecimentos e pessoas físicas que realizam a locação de Stand Up Paddle:

I) Transmitir aos associados e/ou praticantes de Stand Up Paddle as informações acima mencionadas;

II) Colocar à disposição dos seus associados e/ou praticantes, uma embarcação de apoio para a necessidade de socorro imediato e acompanhamento dos grupos de praticantes de Stand Up Paddle nas travessias, onde exista tráfego de embarcação;

III) Ter controle efetivo de seus associados e/ou praticantes e o local para onde se destinam, bem como o regresso destes praticantes de Stand Up Paddle para as Marinas até o pôr do sol; e

IV) Elaborar o Termo de Responsabilidade a ser assinado pelo associado e/ou praticante.

d) Alerta-se que para efeito do previsto no artigo 2° da Lei n° 9.537/1997, que dispõe sobre a Segurança do Tráfego Aquaviário, o equipamento náutico Stand Up Paddle não está sujeito à inscrição na Capitania, Delegacia e Agências.

e) Alerta-se que de acordo com Art. 261 do Código Penal Brasileiro, constituem crime, expor a perigo embarcações ou aeronaves, própria ou alheia, ou praticar qualquer ato a impedir ou dificultar a navegação marítima, fluvial ou aérea. Neste sentido, estas medidas tornam-se necessárias para a segurança da navegação e a salvaguarda da vida humana.

5.16.3. BICICLETAS AQUÁTICAS

No aluguel de Bicicletas Aquáticas, os seguintes procedimentos deverão ser seguidos pela empresa responsável pelos dispositivos:

I) O uso de coletes salva-vidas é obrigatório para todos os usuários.

II) A empresa deverá manter uma embarcação de apoio para prestar socorro aos passageiros dos pedalinhos, em caso de avaria ou emergência.

III) As Bicicletas Aquáticas só poderão ser utilizados nos rios, lagos, lagoas, represas ou águas interiores em que a corrente marítima seja inferior a 3 nós.

IV) As bicicletas aquáticas só poderão ser utilizadas no período noturno se os dispositivos contarem com luzes de navegação (BB e BE e alcançado).

5.17. VISTORIAS ESPECIAIS E PORTABILIDADE DO "PASSE" POR OCASIÃO DO FESTIVAL FOLCLÓRICO DE PARINTINS

A Realização da Vistoria Especial nas embarcações de transporte de passageiros ou de esporte ou recreio, que trafegarem na calha do rio Amazonas, no período do Festival Folclórico de Parintins, visa o cumprimento de requisitos estabelecidos em normas nacionais e internacionais referentes à prevenção da poluição ambiental e às condições de segurança.

A realização da primeira Vistoria Especial é gratuita, sendo as demais indenizadas por GRU estabelecido no "SISTEMA DE CONTROLE DE ARRECADAÇÃO DA AUTORIDADE MARÍTIMA- SCAAM'', o valor refere-se ao serviço de pericia para retirada de exigência de inspeção de "FLAG STATE CONTROL'' para embarcações que operam na navegação interior, atetando-se para o correto preenchimento do valor de Arqueação Bruta (AB) das embarcações. A vistoria tem por finalidade garantir a manutenção da segurança do tráfego aquaviário, a salvaguarda da vida humana e a prevenção da poluição hídrica, em virtude do elevado fluxo de embarcações no rio Amazonas, por ocasião do Festival Folclórico de Parintins e da recorrência ou reincidência das infrações referentes a excessos de passageiros e/ou carga, certificados ou documentos equivalentes vencidos, normas de tráfego e à dotação de material de salvatagem deficiente ou em falta, no período.

O "Passe" é um certificado emitido pelo Agente da Autoridade Marítima indicando que a embarcação passou por Vistoria Especial e visa à redução do tempo de inspeção das embarcações nos postos de fiscalização instalados no rio Amazonas entre os municípios de Manaus-AM e Parintins-AM. **O seu porte é obrigatório e o Comandante da embarcação deverá apresentá-lo por ocasião das abordagens pelos postos de fiscalização em Manaus, Itacoatiara e Parintins e equipes de Inspeção Naval.**

Alerta-se que o não cumprimento desse procedimento sujeita o infrator às penalidades previstas no Art. 25 da Lei nº 9.537/1997 e Art. 23, VI do Decreto 2596/98, que

trata da Segurança do Tráfego Aquaviário (LESTA e RLESTA), por inobservância às normas complementares emitidas pela Autoridade Marítima.

5.18. PLANEJAMENTO, EXECUÇÃO, REGISTRO E APERFEIÇOAMENTO

Para possibilitar um contínuo aperfeiçoamento dos procedimentos operativos que serão implementados internamente, a CFAOC e as Agências possuem um controle em arquivo permanente, contendo ações anteriores, análises e críticas dos eventos náuticos realizados nas áreas de jurisdição.

5.19. CAMPANHAS EDUCATIVAS

Durante a realização das inspeções navais de rotina, da aplicação de cursos de formação de aquaviários, bem como durante a Operação Verão, serão ministradas palestras sobre Segurança do Tráfego Aquaviário, Inscrição de Embarcação, Caderneta de Inscrição e Registro, Carreira do Aquaviário e Habilitação de Arrais Amador, visando incrementar a mentalidade de segurança da navegação nas comunidades da Jurisdição.

CAPÍTULO 6
VIAS NAVEGÁVEIS DA JURISDIÇÃO
SEÇÃO I
CONDIÇÕES DE NAVEGABILIDADE, SINALIZAÇÃO NÁUTICA E NAVEGAÇÃO

6.1. VIAS NAVEGÁVEIS CARTOGRAFADAS

As vias navegáveis cartografadas são as seguintes:

- Rio Amazonas - Cartas náuticas do Rio Amazonas;
- Rio Solimões - Atlas da hidrovia do Rio Solimões – Manaus / Tabatinga; e
- Rio Madeira - Atlas da Hidrovia do Rio Madeira – Itacoatiara / Porto Velho.

No quadro abaixo são apresentadas, resumidamente, as condições de navegabilidade desses rios:

Rio	Trecho navegável	Extensão do trecho navegável (km)	Classificação da via		Prof. máx. em 90% do tempo (m)	Prof. min. em 90% do tempo (m)	Períodos de águas	
			cheia	Vazante			cheia	vazante
Amazonas	Toda a extensão	1.488	A	A	Acima 8,0	6,90	MAR-MAI	SET-DEZ
Solimões	Toda a extensão	1.700	A	A	Acima 8,0	5,00	JAN-JUN	JUL-DEZ
Madeira	Toda a extensão, com restrições na vazante	1.080	A	B	6,8	1,7	DEZ-MAR	ABR-NOV

Classificação da via:

A - rios com mais de 2,10 m de profundidade durante 90% dos dias do ano; e

B - rios de 1,30 a 2,10 m de profundidade durante mais de 90% dos dias do ano.

6.1.1. PRINCIPAIS CARACTERÍSTICAS DO RIO AMAZONAS

O rio Amazonas é navegável durante todo o ano, havendo restrições de navegação

somente na época da seca, que ocorre normalmente nos meses de setembro a dezembro. Nessa época, os navegantes poderão encontrar trechos com visibilidade restrita devido às queimadas. Durante todo o ano poderão encontrar trechos de visibilidade reduzida em função das fortes chuvas e de nevoeiros que ocorrem normalmente pela manhã. Os principais trechos são:

a) **da divisa dos Estados do Amazonas e Pará a Itacoatiara:** as informações sobre as leituras da "régua de nível do rio" podem ser obtidas junto à Agência Nacional de Águas (ANA)

b)de Itacoatiara a Manaus: as informações sobre as leituras da "régua de nível do rio" poderão ser obtidas junto à Agência Nacional de Águas (ANA). Devem-se observar as seguintes limitações à navegação, por ocasião da subida do rio:

I) **Área do Porto de Itacoatiara:** deve-se tomar o máximo de precaução por ocasião da atracação no porto com navios mercantes no período da seca, devido à existência de um alto fundo rochoso nas proximidades do mesmo, ficando estabelecida a Folga Abaixo da Quilha mínima (FAQM) igual a 1,0 metro;

II) **Ponta do Catarro, em frente à cidade de Itacoatiara, na margem direita:** ponto de confluência de tráfego de embarcações, devendo o navegante ter especial atenção. Neste trecho as embarcações de pequeno porte cruzam o rio de margem a margem, e são realizadas as trocas de práticos pelos navios de grande porte;

III**) Passagem da Costa do Tabocal a montante da Ponta do Tabocal:** na carta náutica DHN 4106B corresponde à região na extremidade montante da Ilha das Onças. Importante ponto de confluência de embarcações de todo tipo, onde são registradas profundidades muito reduzidas para a navegação de navios mercantes na época da seca do rio. Os navios de grande porte deverão ter especial atenção à manobra realizada pelas embarcações menores, sendo conveniente estabelecer contato via VHF para definir a manobra a ser realizada pelas embarcações envolvidas. Recomenda-se navegação com atenção redobrada;

IV) **Ponta da Jatuarana:** canal limitado em largura para embarcações de grande porte e área de confluência de embarcações em geral;

V) **Faroletes de Moronas e Jacaré:** são registradas profundidades reduzidas para a navegação de navios mercantes na época da seca dos rios. Recomenda-se navegação com atenção redobrada; e

VI) **Encontro das águas dos rios Negro e Solimões:** importante ponto de confluência de embarcações de todo tipo. Os navios de grande porte deverão ter especial atenção à manobra realizada pelas embarcações menores, sendo conveniente estabelecer contato via VHF para definir a manobra a ser realizada pelas embarcações envolvidas. Recomenda-se navegação com atenção redobrada.

Obs.: No que se refere à velocidade máxima, atentar para o item 5.2

6.1.2. PRINCIPAIS CARACTERÍSTICAS DO RIO SOLIMÕES

O rio Solimões é navegável durante todo o ano, havendo restrições de navegação somente na época da seca, que ocorre normalmente nos meses de agosto a dezembro. Durante todo o ano poderão ser encontrados trechos de visibilidade reduzida em função das fortes chuvas e de nevoeiros, que ocorrem normalmente pela manhã.

O Atlas da Hidrovia do rio Solimões, emitido pela DHN, é a referência para os navegantes. Contudo, como o leito do rio altera-se frequentemente, com mudanças dos canais navegáveis de um ano para o outro devido ao deslocamento dos bancos de areia, os croquis de navegação podem apresentar informações mais atualizadas do que as das cartas náuticas disponíveis. Em virtude dessas mudanças, poderão ocorrer fundeios no trecho entre Manaus e Tabatinga-AM para que a navegação seja realizada com luz do dia e com segurança, medida recomendável. No período da seca, os navios mercantes podem ter que realizar “transbordo” para redução de calado em pontos críticos. As informações sobre as leituras da “régua de nível do rio” podem ser obtidas junto à Agência Fluvial de Tefé.

Os principais trechos são:

a) **de Manaus a Coari:** este trecho deverá ser preferencialmente navegado no período diurno, em virtude dos canais navegáveis apresentarem pouca largura e profundidade. As principais passagens são:

I) **Ilha dos Mouras:** o canal fica limitado para navios de grande porte nas passagens das duas pontas da ilha devido a pouca profundidade na época de seca;

II) **Costa do Caldeirão:** existência de pedral na margem esquerda, a montante da cidade de Iranduba. O pedral é visível na época de seca;

III)**Costa do Calado:** limitada pela profundidade na época da seca para navios de grande porte;

IV) **Farolete de Manacapuru:** passagem limitada devido à existência de pedral

próximo ao farolete e de um banco de areia em frente à cidade, que aflora na seca. No período da seca, as embarcações de grande porte, normalmente, navegam pela margem esquerda, entre o banco e a cidade. Deve-se ter especial atenção ao pedral que fica a jusante do canal. Há rebojos no canal;

V) **Banco da Arraia:** o banco de areia muda frequentemente de lugar, sendo necessário grande conhecimento do local para a navegação segura de navios de grande porte. Durante o período de seca, a navegação torna-se restrita a todos os tipos de embarcações;

VI) **Costa da Ajaratuba:** nas proximidades da comunidade de Porto Estrela, a passagem fica restrita em função da pouca profundidade na época da seca;

VII) **Costa o Ambé, entre a foz do rio Purus e a cidade de Anori:** Na época da seca, apresenta altos-fundos, tipo torrões isolados e em diversos locais, limitando a passagem para navios de grande porte;

VIII) **Jamacanã:** Durante o período da seca a passagem de navios de grande porte fica limitada pelo estreitamento e redução da profundidade do canal; e

IX) **Entre a foz do rio Badajós e a ponta de cima da Ilha da Botija:** deste ponto até a cidade de Coari os bancos mudam de posição constantemente, apresentando baixas profundidades e restringindo a passagem de navios de grande porte na época da seca. A configuração do canal muda de um ano para o outro, sendo necessário conhecimento detalhado da região para executar uma navegação segura.

Neste trecho, em virtude dos canais navegáveis apresentarem pouca largura e profundidade, é necessário que todos os recursos visuais sejam disponibilizados pelo prático, logo, o trecho deverá ser obrigatoriamente navegado com a luz do dia.

b) **De Coari a Fonte Boa:** a navegação neste trecho deverá ser realizada, preferencialmente, no período diurno. As principais passagens são:

I) **Barro Alto:** os bancos mudam de posição constantemente, apresentando baixas profundidades e restringindo a passagem de navios de grande porte na época da seca. A configuração do canal muda de um ano para o outro, sendo necessário conhecimento detalhado da região para executar uma navegação segura;

II) **Ilha do Catuá Grande e Ilha do Camaleão:** no período da seca, normalmente, o canal navegável muda da calha principal para o paraná situado entre a ilha do Camaleão e a margem esquerda, que consta na carta de navegação nº DHN 4150 (HS-B4) como “zona não

hidrografada" (estas alterações variam de ano para ano). A navegação pode ficar restrita devido à redução de profundidade nas passagens;

III) **Entre a foz do rio Japurá e Vila Coadi:** os bancos mudam de posição constantemente, apresentando baixas profundidades e restringindo a passagem de navios de grande porte na época da seca. A configuração do canal muda de um ano para o outro, sendo necessário conhecimento detalhado da região para executar uma navegação segura;

IV) **Ilha do Mari-Mari:** pouca profundidade no período da seca, no trecho compreendido entre a ponta de baixo e a de cima da ilha, restringindo a passagem de navios de grande porte;

V) **Paraná do Macuapanin:** trata-se de um canal novo, ainda em formação devido à mudança do leito do rio. É estreito e possui trechos de pouca profundidade no período da seca; e

VI) Entre o lago Uará e a cidade de Fonte Boa: neste trecho a navegação apresenta uma das maiores limitações do rio Solimões. Os bancos mudam de posição constantemente, apresentando baixas profundidades e restringindo a passagem de navios de grande porte na época da seca. A configuração do canal muda de um ano para o outro, sendo necessário conhecimento detalhado da região para executar uma navegação segura.

Obs.: No que se refere à velocidade máxima, atentar para o item 5.2, desta norma;

6.2. VIAS NAVEGÁVEIS NÃO CARTOGRAFADAS

No quadro abaixo são apresentadas, resumidamente, as condições de navegabilidade dessas vias:

Rio	Trecho navegável	Extensão do trecho navegável (Km)	Classificação da via		Prof. máx. em 90% do Tempo (m)	Prof. min. em 90% do Tempo (m)	Períodos de águas	
			cheia	vazante			cheia	vazante

Urucu	Toda a extensão, na cheia	430,0	A	-	5,0	0,5	DEZ-FEV	AGO-NOV
Negro	Toda a extensão, na cheia	562,0	A	-	60,0	1,0	DEZ-JUL	AGO-NOV
Branco	Toda a extensão, com restrições na vazante	550,0	A	B	5,0	2,0	ABR-JUN	SET-MAR
Purus	Toda a extensão, com restrições na vazante	3.212,8	A	B	5,0	2,0	NOV-ABR	MAI-OUT
Juruá	Toda a extensão, com restrições na vazante	1667,7	A	B	5,0	2,0	NOV-MAR	ABR-OUT
Japurá	Toda a extensão, com restrições na vazante	2.407,6	A	B	4,0	1,2	ABR-JUN	JUL-FEV

Classificação da via:

A - rios com mais de 2,10m de profundidade durante 90% dos dias do ano; e

B - rios de 1,30m a 2,10m de profundidade durante mais de 90% dos dias do ano.

6.2.1. RIO MAUÉS AÇU, PARANÁS DO RAMOS e URARIÁ

O rio Maués Açu possui águas escuras que se prestam para a aguada. Deve-se ter muita atenção ao demandar a cidade de Maués a partir do Paraná do Urariá, pois, na

vazante, é estreito e existem pedrais na margem direita do rio, bem como bancos de areia no lado esquerdo do canal.

Os Paranás do Ramos e Urariá são regulados pelos rios Amazonas, Madeira, Maués Açu, Canumã e Abacaxis, acompanhando o regime desses rios, principalmente do Amazonas. O período de cheia é entre os meses de maio a junho e a vazante (com possibilidade de seca) de setembro a outubro.

O Paraná do Ramos liga a Vila Amazônia (5 milhas náuticas a jusante de Parintins) até a ilha do Panuma, cerca de 30 milhas náuticas a jusante da cidade de Itacoatiara. No período da cheia, a utilização desse paraná diminui a distância a ser percorrida, tendo em vista a quantidade de lixos, troncos que descem pela calha principal, bem como a correntada.

O Paraná do Urariá, juntamente com o Paraná do Ramos, permite a ligação do rio Amazonas com o rio Madeira. Ele recebe águas dos rios Maués Açu, Abacaxis e Canumã. Entretanto, na vazante, no trecho do Paraná do Urariá até a calha principal, não é navegável, apresentado uma profundidade com aproximadamente 0,6 metros, não se conseguindo atingir o rio Madeira, pois sua largura é muito estreita (80 metros) e normalmente se formam praias.

Pelo Paraná do Ramos se atinge também o Amazonas pelos Paranás do Limão Grande e do Limãozinho (também chamado, impropriamente, de Furo do Limão), que sai a montante de Parintins e só é navegável por embarcações de pequeno porte. Na boca desse paraná são encontradas as menores profundidades (2,0m) de todo o trecho.

6.2.2. RIO URUCU

Trata-se de um rio muito estreito, pouco profundo, extremamente sinuoso, com inúmeras curvas de pequeno raio de curvatura. Possui grande número de troncos submersos e grande quantidade de vegetação aquática no seu leito. Apresenta um sistema de balizamento deficiente, tanto no próprio rio, como no lago de Coari.

Normas especiais para o tráfego neste rio encontram-se especificadas no Art. 6.4 desta norma.

6.2.3. RIO NEGRO

Principal afluente da margem esquerda do rio Amazonas, e seu formador, na sua confluência com o rio Solimões. É coberto por croquis emitidos pela DHN até a cidade de

Santa Isabel do Rio Negro-AM. O seu leito é de natureza rochosa e areia, indicando poucas mudanças acima da cidade de Novo Airão-AM, sendo considerado confiáveis para navegação. Muitas pedras já se encontram cartografadas no croqui. A natureza do fundo inspira especial cuidado quanto ao fundeio, a fim de não se perder o ferro que tenha unhado em uma pedra. Assim, sempre que possível, a abarrancagem é preferível.

A variação do nível das águas entre a cheia e a vazante é de 10,0m a 16,0m. A água é escura, limpa e boa para aguada, desde que colhidas acima das vilas e povoados. Tendo em vista o rio atravessar várias regiões fisiográficas com características climáticas peculiares, a época das cheias ou das secas não ocorre ao longo de todo o trecho. Assim, como regra pode dizer que o rio começa a encher, na sua parte alta, dois meses antes do rio Amazonas, isto é, outubro/novembro, e a vazante também ocorre com essa antecedência. No meio do trecho, nas proximidades de Barcelos-AM, os estados de cheia máxima e seca coincidem com as épocas das mesmas nas proximidades de Manaus. Assim, apresenta-se, estatisticamente, um quadro resumo da lâmina d`água esperada:

Trecho do Rio	**Enchente**	**Vazante**	**Lâmina máxima d´água esperada**	**Lâmina mínima d´água esperada**
São Gabriel da Cachoeira à Santa Isabel do Rio Negro	novembro / dezembro	maio / junho	Muito variável	Muito variável
Barcelos à Moura	dezembro / janeiro	junho / julho	5,0 metros	1,0 metros
Moura à foz	janeiro / março	julho / agosto	10,0 metros	3,0 metros

Os repiquetes ocorrem nas seguintes épocas:

a) Novo Airão - meses de novembro e dezembro;

b) Barcelos - meses de novembro e dezembro; e

c) Santa Isabel - meses de janeiro e abril, com variação de até 2m diários.

As informações sobre as leituras da “régua de nível do rio” em Manaus podem ser obtidas junto à CFAOC.

Os principais trechos do rio são:

a) **Entre Manaus e a foz do rio Branco**: com extensão aproximada de 145 milhas náuticas, e largura variando entre 1 e 13 milhas náuticas. O mesmo ocorre com a profundidade, que varia de 3,0 a 60,0 metros. É recomendável a navegação pelos paranás do Jacaré e do Cantagalo, de forma a evitar as pedras existentes na calha principal. As principais passagens são:

I) **Ponte sobre o rio Negro, em Manaus:** para a sua transposição deverão ser observadas as seguintes limitações:

- Embarcações acima de 2.000 TPB somente poderão utilizar os canais principais para transposição da ponte, no período diurno, em boas condições meteorológicas, com boa visibilidade, com auxílio de rebocadores e, nos casos previstos nas Normas da Autoridade Marítima, com prático embarcado; e

- As demais embarcações, menores que 2.000 TPB, deverão utilizar os canais secundários.

Dados dos vãos principais da Ponte sobre o Rio Negro são:

- Altura: 2 Centrais (um para subir e outro para descer o rio) - 55 metros; e

- Largura: 2 Centrais (um para subir e outro para descer o rio) - 200 metros.

Obs.: As embarcações com calado aéreo superior ao indicado acima não poderão trafegar sob a ponte.

II)**Arquipélago das Anavilhanas:** maior arquipélago fluvial do mundo, com mais de oitocentas ilhas, sendo muito difícil reconhecer as margens. As ilhas são longas e estreitas, confundindo o navegante, que deverá seguir os croquis e evitar a travessia noturna quando não tiver conhecimento profundo da área. Devido à sua beleza e à curiosidade dos turistas, várias embarcações já se perderam ou se acidentaram na região.

b) Entre a foz do rio Branco e Camanaus: com 244 milhas náuticas de extensão. Todo o trecho deve ser navegado exclusivamente em período diurno, com o concurso de navegantes que já o tenham percorrido, e com a embarcação sem restrições de máquinas.

A largura do rio também é irregular neste trecho, podendo variar de 0,8 a 90 milhas náuticas (Barcelos). As profundidades variam ao longo do trecho de acordo com a época do ano e, em certas épocas do ano, limitam a navegação para embarcações de médio porte (2 m de calado). As principais passagens são:

I) **Entre as milhagens 255 e 255 do croqui do rio Negro:** existe canal navegável junto à margem esquerda, em zona não hidrografada. Só deve ser demandado com

detalhado conhecimento do local;

II) **Paraná de São Tomé:** a passagem deve ser evitada em face do perigo oferecido pelas pedras;

III) **Passagem entre as ilhas Chile e Mananiá:** as pedras na posição 00°25,280'S/065°06,600'W devem ser deixadas por bombordo na subida, passando-se próximo da margem esquerda a cerca de 150 jardas, e em seguida junto à ponta montante da Ilha do Chile, passando-se próximo à Ilha do Mananiá a cerca de 50 jardas;

IV) **Passagem do Ábada:** é feita deixando-se a ilha por boreste, na subida. Foram identificadas pedras nas seguintes posições, que devem ser deixadas por bombordo:

- 00°18',18 S / 065°29',73 W;
- 00°18',46 S / 065°31',45 W; e
- 00°18',17 S / 065°30',93 W.

O trecho é considerado especialmente crítico na descida, devido à manobra bastante fechada que se deve fazer para entrar no Paraná, e à existência de uma ponta de pedra a se projetar para o canal;

V) **Passagem do Massarambi:** constitui-se num trecho perigoso de 5 milhas de extensão com inúmeras pedras em todo o percurso, porém relativamente reto (sem curvas). A água corre farta numa passagem particularmente estreita (cerca de 13m de largura) entre duas pedras, formando fortes rebojos e pontas d'água que podem afetar o governo da embarcação. Neste trecho as máquinas devem ser empregadas a toda força. É mais perigoso na subida, pois o rebojo ocasionado pelas pedras (e que causam desgoverno) tem que ser vencido antes da passagem pelas pedras propriamente ditas. Quando se desce, conhecendo-se a passagem, se ocorrer o desgoverno, a embarcação pode até rabear um pouco, mas já estará safa das pedras que já ficaram a montante;

VI) **Passagem da ilha do Pinto:** curto trecho de navegação sinuosa, para vencer três pedras que ficam no meio do canal;

VII) **Proximidades de Camanaus:** a partir de 10 milhas náuticas a jusante de Camanaus é muito difícil navegar em meio à grande quantidade de pedras que ficam no leito do canal, tendo ocorrido diversos acidentes com empurradores e balsas. Na época das cheias as embarcações passam por cima das pedras;

C) **Entre Camanaus, São Gabriel da Cachoeira e Cucuí:** neste trecho o rio é típico de corredeiras, sendo possível navegar somente no período de cheia, com embarcações com

motores de grande potência e alta velocidade, capazes de superar a correntada, que chega a atingir aproximadamente 13 nós. Além disso, todo o trecho deve ser navegado exclusivamente em período diurno, com o concurso de navegantes com conhecimento detalhado do local. Não é recomendável a investida por embarcações de deslocamento superior a 500 TPB ou de boca maior que 9 metros. Nos trechos críticos assinalados os motores deverão ser empregados a toda força:

I) **Acesso a São Gabriel da Cachoeira:** só pode ser feito vencendo-se as corredeiras de Camanaus e montando-se as passagens do Tinhana (correnteza de aproximadamente 9 nós) e de Furnas (forte correntada e trecho em curva). Esse percurso tem uma extensão total de cerca de 10 milhas náuticas e, devido a força das águas e as curvas, a maioria das embarcações de linha e os comboios permanecem em Camanaus, de onde parte a estrada de 23 km até a cidade de São Gabriel da Cachoeira.

Subindo o rio, próximo à margem esquerda, logo a uma milha do porto de Camanaus, cruza-se o rio até a metade de sua largura, contornando uma ilha, para em seguida voltar à margem esquerda, subindo as corredeiras. A forte correntada, os rebojos e rodamoinhos que se formam tornam muito difíceis o governo das embarcações. Em determinadas ocasiões, a embarcação pode apresentar banda para os bordos devido ao forte rebojo, contornando-se a ilha no meio do rio.

A montante das corredeiras de Tucubá, a existência de pequenas ilhotas de pedra e pedras submersas obrigam o navegante a alterar constantemente o rumo da embarcação nas 10 milhas que separam Camanaus de São Gabriel da Cachoeira. Estas alterações frequentes de rumo tornam-se muito difíceis devido à força da água que desce e aos rebojos que se formam. Já próximo de São Gabriel da Cachoeira, a passagem de Furnas, junto à margem esquerda do rio, apresenta as mesmas características e as mesmas dificuldades das corredeiras de Tucubá.

Descendo o rio, a maior dificuldade encontrada é na passagem de Furnas, devido à correntada que se pega pelo través, aos rebojos e remansos que se formam, obrigando a constante vigilância no governo da embarcação. Ainda na descida, passa-se pelo Tinhana, local com boa profundidade próximo à margem direita, onde a correntada é muito forte. A descida por esta passagem é mais fácil, pois evita as grandes alterações de rumo feitas na subida, quando se ultrapassa as corredeiras de Tucubá, contornando-se uma ilha no meio do rio.

II) **Corredeiras de Curucuri:** localizada a jusante da igreja de São Gabriel da Cachoeira, sobe-se junto à margem esquerda, passando próximo a uma pedra que desvia o curso do rio, dando origem a uma correntada muito forte. O governo é extremamente difícil e o avanço é lento em face da força da corrente. Após as corredeiras de Curucuri, com toda a força dos motores investe-se para a margem direita em direção à ilha Uacará. Próximo à ponta de Buiacanga a correntada é muito forte, causando os mesmos problemas já descritos no que diz respeito ao governo das embarcações. A descida é mais fácil que a subida, pois a correntada conduz a embarcação.

III) **Corredeiras de Fortaleza:** A partir da ponta de Buiacanga, volta-se mais uma vez para a margem esquerda, ultrapassando-se estas corredeiras, onde o rio Negro apresenta sua menor largura, cerca de 300 m. Toda a água do Negro passa por essa garganta. A força da água descendo, somada aos rebojos e rodamoinhos que se formam dificultam muito o governo da embarcação, e o avanço é muito lento. Nas cruzadas de margem a margem e ultrapassagem das corredeiras, em determinadas ocasiões, mesmo com o leme todo carregado para um bordo, o navio ainda tende para o bordo oposto, obrigando o navegante a usar a reserva de seus motores para auxiliar no seu governo. Na cheia, o menor fundo registrado no trecho é de 4 metros. Na descida, não há maiores dificuldades.

IV) **Das corredeiras de Fortaleza até a foz do rio Uaupés:** a correntada ainda é bastante forte, sendo estimada entre 3 a 5 nós de intensidade. As inúmeras pedras que afloram, somadas a outras submersas, exigem um sinuseio constante do navio, que é dificultado pela correntada e pelos rebojos que se formam. Cuidado ainda maior deve se ter nas proximidades da ilha das Flores, onde os fenômenos descritos apresentam-se com maior intensidade. Na descida, o perigo é ainda maior pela grande dificuldade de manutenção do rumo pretendido.

V) **Entre a foz do rio Uaupés e Cucuí:** a correnteza reduz-se para 2 ou 3 nós, o rio é largo e calmo, deixando de aparecer as ilhotas de pedras e as pedras submersas.

6.2.4.- RIO BRANCO

A navegação no rio Branco (afluente da margem esquerda do rio Negro, principal rio do Estado de Roraima) não segue as regras gerais de “lixo” e “envolvente”, pois o rio possui vários bancos em seu leito, formando um canal entre eles. Não há referências visíveis entre as guinadas de margem a margem e, por isso, é imprescindível dispor de navegantes com

conhecimento atualizado da região.

É obrigatório o acompanhamento diário da variação do nível do rio segundo as réguas de Boa Vista-RR e Caracaraí-RR, mantidas pela Companhia de Pesquisa de Recursos Minerais (CPRM, Serviço Geológico do Brasil). Em Boa Vista, a leitura da régua é feita pela Companhia de Água e Esgoto de Roraima (CAER), e em Caracaraí pela Associação dos Pescadores. A subida ou descida no nível do rio observada em Boa Vista demora cerca de 2 dias para chegar a Caracaraí.

O rio é dividido em três trechos: Baixo, Médio e Alto Rio Branco.

a) Baixo Rio Branco: principal trecho navegável, entre a foz e as Corredeiras do Bem-Querer (ou de Caracaraí), no município de Caracaraí**.** Neste trecho, com extensão de 237 milhas náuticas, o rio varia a sua largura de 700m a 4.000m. Ocorrem marcantes variações de profundidade e encontram-se grandes praias e ilhas de areia grossa, que mudam constantemente de posição. O canal navegável é muito sinuoso. Dependendo do nível das águas pode ocorrer a mudança do canal navegável, e trechos antes navegáveis encontrarem-se fechados no ano seguinte. Os desmoronamentos são frequentes, fornecendo assim material que, não podendo ser transportado pela correnteza, assoreia o fundo do rio, formando bancos e ilhas que podem obstruir o canal navegável. O fundo é de areia e rochas. As águas são pouco barrentas, apresentando coloração clara, sendo boa para aguada.

O período de enchente nesse trecho de rio vai de maio a agosto e o de vazante de setembro a março, podendo-se considerar abril como o mês de transição, sendo observadas profundidades variando de 5,0m a 2,0m. Os repiquetes ocorrem de junho a agosto, com uma variação de até 3,0m em Caracaraí.

As passagens consideradas críticas são:

I)<u>Proximidades de Santa Maria do Boiaçu</u>: existência de um colar de pedras bem à esquerda de quem sobe o rio, próximo a um furo;

II) <u>Proximidades das Ilhas de Mariri:</u> existência de pedras entre elas e as ilhas Aliança e Japuri; e

III) <u>Ponte da Rodovia BR-174:</u> cruza o rio 3 milhas a jusante de Caracaraí. Para a transposição segura, sob o vão mais alto, próximo à margem esquerda, deve ser acompanhada a régua fluviométrica de Caracaraí. A altura máxima do navio deve ser

calculada pela expressão:

A = 26 - R, onde A é a altura máxima do navio, e R é a leitura da régua em Caracaraí, em metros. Por exemplo: se a régua em Caracaraí medir 9,0m, o navio deverá ter no máximo 17m de altura, a partir da linha d'água, para a passagem segura.

b) Médio Rio Branco: é o trecho mais crítico para a demanda a Boa Vista. Corresponde ao trecho encachoeirado de 24 km (13 milhas) de extensão, a montante de Caracaraí. As Corredeiras do Bem-Querer impedem a navegação na calha principal do rio. O único canal alternativo é o furo do Cojubim, onde a Marinha do Brasil efetuou derrocamento nos anos de 1970 que melhorou parcialmente a navegabilidade. A correnteza pode atingir 7 nós e há diversas pedras próximas à superfície.

O furo do Cojubim deve ser investido somente nas seguintes condições:

- Em período diurno;

- Com tempo bom e boas condições de visibilidade;

- Se a leitura da régua em Boa Vista estiver subindo;

- Com navegantes que já realizaram a passagem anteriormente, e que tenham detalhado conhecimento do local;

- Comboios de mais de uma balsa devem ser desmembrados e passar balsa por balsa;

- Extrema precaução quanto ao cruzamento de outras embarcações no sentido oposto (chamada geral no canal 16 VHF); e

- A descida do Furo do Cojubim requer cautela quanto à possibilidade de perda de governo (deve-se manobrar com máquinas).

c) Alto Rio Branco: trecho compreendido entre a boca montante do furo do Cojubim e os formadores do rio Branco (rios Uariquera e Tacutu). Navegável até Boa Vista, na cheia. Apesar de considerado um trecho seguro, ainda assim é recomendável a orientação de navegante com detalhado conhecimento do local, devido a ocorrência de baixas profundidades e pedras submersas. A ponte dos Macuxis, em Boa Vista, limita a subida de navios além deste ponto, possível apenas para pequenas embarcações.

6.2.5. RIO PURUS

É um rio muito sinuoso, que muda o leito frequentemente. Ocorrem profundas modificações no canal navegável após as cheias, quando também o rio fica obstruído por árvores caídas. Antigos braços do rio, ensacados, formam lagos ao longo da hidrovia. Nas cheias também deve-se ter bastante atenção à grande quantidade de troncos transportados pela correnteza, que podem avariar eixos e hélices. Há ocorrências de pedras que afloram mesmo na cheia, a maioria delas cartografada no croqui expedido pela DHN, além de torrões e curvas fechadas, com rebojos e remansos.

A foz é em forma de delta, com muitos canais e furos. A água é branca ou barrenta e o leito é de barro ou lama e pedras em alguns trechos. Determinados trechos, dependendo da época do ano, apresentam cor cinza ou preta, sofrendo influência de seus afluentes maiores. Obedece a lei da envolvente em quase todo o seu percurso até o Estado do Acre. É possível fazer aguada em alguns afluentes de águas claras ou escuras.

As informações sobre as leituras da "régua de nível do rio" poderão ser obtidas junto à Agência Fluvial de Boca do Acre.

Os seguintes trechos são de interesse à navegação, com as distâncias em milhas, a partir da foz, referenciada no croqui da DHN:

a) **Baixo Purus:** da foz no rio Solimões até a foz do rio Ituxi, na cidade de Lábrea-AM, com 685 milhas náuticas de extensão. As principais passagens são:

I) Furo das Três Bocas: a 207 milhas da foz, possibilita encurtar a navegação em 13 milhas em relação à feita na calha principal. Nos últimos anos o furo tem se alargado, em processo de se tornar nova calha principal; e

II) Ensacado e praia do Cassiam: na milhagem 493, na curva mais fechada que a lançada no croqui da DHN, e a existência de fortes rebojos na localidade de Cassiam (05° 51,7'S/064° 29,5'W).

6.2.6. RIO JURUÁ

O rio Juruá é o rio mais sinuoso da Bacia Amazônica. Seu leito sofre grandes mutações e o nível das águas altera-se devido aos repiquetes rápidos. A sinuosidade dá margem à formação de inúmeros sacados que vão alterando o curso do rio e criando novos caminhos. Deve-se ter muita atenção para não se sair da calha principal (que pode alterar de um ano para outro) e entrar num sacado não mais navegável.

A largura média do trecho entre sua foz e a do rio Tarauacá é de 140m; nos estirões

varia de 100m a 120m e nas curvas acentuadas entre 80m a 120m. A variação do nível das águas na foz do rio, entre uma enchente e a vazante consecutiva, pode atingir de 8m a 16 m. Subindo o rio, a partir da cidade de Eirunepé, as dificuldades de navegação aumentam, devendo-se ter atenção ainda aos inúmeros troncos espetados nas margens.

Na navegação deve-se sempre observar a lei da envolvente. As águas do Juruá são brancas ou barrentas, dependendo da estação das chuvas. O fundo é, em grande parte de sua extensão, de lama. Acima de Eirunepé-AM a velocidade do rio varia muito, podendo chegar a 5 nós, dificultando muito a navegação na área, requerendo grande conhecimento e habilidade para garantir uma navegação segura.

São considerados trechos do rio de interesse para a navegação o Baixo e o Médio Juruá. O Baixo Juruá compreende o trecho da foz até a confluência com o rio Tarauacá, com uma extensão de 474 milhas náuticas. O Médio Juruá compreende o trecho entre a foz do rio Tarauacá e a foz do rio Breu, no Estado do Acre, com uma extensão de 690 milhas náuticas. As informações sobre as leituras da "régua de nível do rio" poderão ser obtidas junto à Agência Fluvial de Eirunepé.

a) Entre a foz e Eirunepé: este trecho possui, aproximadamente, 900 milhas náuticas, onde se pode navegar mais facilmente, embora exija cuidados especiais devido a sua sinuosidade e aos troncos que descem o rio no meio do lixo. Pode-se navegar à noite, embora não seja recomendável. Na enchente, a profundidade média esperada é de 5,0m, permitindo comboios com até 60m de comprimento. As principais passagens são:

I) Praia do Muncuba: a 154 milhas da foz. A praia fechou a calha principal do rio lançada no croqui de navegação da DHN, que ficou ensacada, mudando a configuração do rio. A volta rápida formada liga as milhagens 154 e 156. Na seca, este trecho deve ser demandado no período diurno;

II) Barreira do Japó: a 166 milhas náuticas da foz existem pedras. Deve-se navegar do meio do rio para a margem esquerda;

III) Barreiras do Baçururu: a 210 milhas náuticas da foz existem pedras. Deve-se navegar do meio do rio para a margem esquerda;

IV) Montesuma: a 471 milhas náuticas da foz existem navegar no meio do rio existem pedras na margem direita;

V) Paraoá: a 509 milhas náuticas da foz existem pedras. Deve-se navegar junto a margem esquerda;

VI) Pedras do Chibauá: a 595 milhas náuticas da foz existem pedras. Deve-se navegar do meio do rio para a margem esquerda;

VII) Itamarati: a 690 milhas náuticas da foz existe varadouro estreito, com forte correntada, redução de 14 milhas, no percurso;

VIII) Extrema: a 718 milhas náuticas da foz existem pedras, navegar colado à margem direita;

IX) Cantagalo: a 730 milhas náuticas da foz existem pedras, navegar próximo à margem direita;

b) Entre Eirunepé e Porto Walter: Este trecho tem aproximadamente 480 milhas náuticas, com curvas fechadas e largura estreita, além de muitos troncos descendo o rio. Desta forma, deve-se evitar viagem noturna. Na cheia possui profundidade média de 4,0m até Cruzeiro do Sul-AC (2,0 m na vazante), não recomendando comboios com tamanho superior a 45m. Ter atenção aos repiquetes, uma vez que, deixando de chover apenas um dia, o nível do rio pode baixar em cerca de dois metros. O trecho entre Cruzeiro do Sul e Porto Walter só pode ser navegado com segurança na cheia do rio, sendo de largura muito estreita e com forte correnteza. Na época da cheia é possível chegar-se ao rio Breu, na fronteira. As principais passagens são:

I) Paraná do Javi: estreito, não deve ser investido na seca;

II) Curva da Colônia "Rodrigues Alves": a 12 minhas náuticas a montante de Cruzeiro do Sul, onde ocorre estreitamento e curva fechada;

III)Curva "13 de Maio": a 20 milhas náuticas a montante de Cruzeiro do Sul, onde ocorre estreitamento - curva muito fechada.

6.2.7. RIO JAPURÁ

Suas condições de navegação se assemelham muito com as do rio Solimões. É bastante largo em vários pontos, e possui um grande número de ilhas e de passagens. É conhecido como "rio das surpresas" pelos ribeirinhos locais, por não ter bem definido seu regime de águas, por apresentar repiquetes e por apresentar bancos no meio do rio, que surgem inesperadamente. Desta forma, é recomendada a utilização de guias regionais para navegar neste rio.

As datas de início de enchente e vazante variam de ano para ano, sendo a média apresentada no quadro do item 0601. Em Maraã-AM existe régua fluviométrica, cujas

leituras podem ser obtidas junto à colônia de pescadores local. O rio Solimões exerce influência no nível do rio Japurá até 170 milhas da foz deste, devido às várias ligações existentes entre ambos, como o Auati-Paraná e o Furo do Aranapu. Assim, para efeito de referência, também poderá ser acompanhada a leitura da régua do rio Solimões junto à Agência Fluvial de Tefé.

Acima de Maraã a navegação requer maior cautela.

As principais passagens são referenciadas em milhas a partir da foz:

- Milhagem 126 a 135: existe passagem entre as Ilhas do Macaco e do Japurá, retornando-se à calha principal a montante da Ilha do Boiador, na subida;
- Milhagem 205: assoreamento na boca do paraná do Mocó;
- Milhagem 308: alto-fundo junto à Ilha Grande (Tabuleiro do Flexa), a cerca de uma 1,5 MN da boca montante do Paraná da Igualdade;
- Milhagem 354 a 360: a montante da Ilha do Cajubim existem três ilhas não cartografadas, que devem ser deixadas por BB de quem sobe o rio;
- Milhagem 375 a 380, junto à fronteira com a Colômbia: pedras na margem direita. Deve-se navegar a cerca de 1000 jardas dessa margem.

6.3. REGRAS NA NAVEGAÇÃO INTERIOR

As presentes regras especiais são complementares, no âmbito da navegação interior, às regras estabelecidas no Regulamento Internacional para Evitar Abalroamentos no Mar - Londres, 1972 - (RIPEAM 72):

a) Toda embarcação deverá navegar com velocidade apropriada sempre que cruzar com embarcações pequenas e embarcações empurrando ou rebocando e que devam ser protegidas contra avarias causadas pela ação de banzeiros.

b) Toda embarcação deverá navegar com velocidade apropriada sempre que se aproximar de qualquer embarcação amarrada a um trapiche, cais e similares.

c) Uma embarcação com propulsão mecânica navegando em rios ou canais com a corrente a favor terá preferência de passagem quando cruzar com uma embarcação navegando contracorrente. A embarcação que tem a preferência indicará a maneira e o local da passagem e efetuará os sinais de manobra apropriados.

d) Uma embarcação não deverá cruzar ou ultrapassar outra embarcação sob vãos de pontes, a menos que o canal ofereça uma largura compatível para a passagem simultânea.

e) Luzes de tubulação de dragagem

As tubulações de dragagem, que estiverem flutuando ou apoiadas em cavaletes, deverão exibir, durante a noite e em períodos de visibilidade reduzida, uma fileira de luzes circulares amarelas com as seguintes características:

I) Seu alcance será de pelo menos 2 milhas em noite escura e calma;

II) Sua altura sobre a água não será inferior a 1m e nem superior a 3,5m; e

III) O espaçamento das luzes não será superior a 10m, quando a tubulação cruzar um canal navegável. Quando não cruzar uma via de navegação, as luzes deverão ser em número suficiente para mostrar corretamente o comprimento e a posição da tubulação.

Tubulações de dragagem exibirão, adicionalmente, mais duas luzes circulares vermelhas nos extremos da tubulação, incluindo aqueles que se formam quando se separa a tubulação para permitir a passagem de embarcações, tanto na sua posição fechada ou aberta, com as seguintes características:

IV) Alcance destas luzes deve ser, pelo menos, de 2 milhas em noite escura e clara;

V) Estas luzes serão posicionadas a uma altura não inferior a 1m acima da fileira das luzes amarelas.

6.3.1. NORMAS PARA TRÁFEGO DE COMBOIO NO RIO URUCU

6.3.1.1. CONSTITUIÇÃO DO COMBOIO BALSA-EMPURRADOR

Os comboios deverão ser formados por um empurrador e apenas uma balsa de até 500 (quinhentas) toneladas, com as dimensões máximas de 60 (sessenta) metros de comprimento e 15 (quinze) metros de largura. O empurrador deverá ter, comprovadamente, reserva de potência e boas condições de manobrabilidade (preferencialmente dotado de dois propulsores). Qualquer solicitação de alteração, para maior, nas características do comboio, deverá ser apresentada para apreciação do Capitão dos Portos.

6.3.1.2. NAVEGAÇÃO NO RIO URUCU

Os comboios somente poderão navegar no período diurno. Deverão ser obedecidas as regras internacionais de navegação previstas no RIPEAM, em especial a regra 9 (nove). As embarcações deverão ter atenção para a realização dos seguintes procedimentos:

- Navegar no sentido convencionado de mão e contramão;
- Emitir sinais sonoros previamente ao entrar em cada curva;
- Manobrar com marcha reduzida nas curvas;
- Utilizar embarcação do tipo “voadeira” adiante do comboio, em especial nos

trechos mais sinuosos;

- Ultrapassar ou cruzar com outras embarcações somente nos estirões (trechos retilíneos);

- Evitar a colisão nas margens do rio;

- Trafegar com velocidade máxima de 6 (seis) nós;

- Observar rigorosamente a sinalização náutica;

- Trafegar com carga uniformemente distribuída, evitando banda e trim; e

- Dentre os tripulantes, pelo menos um deverá possuir pleno conhecimento do rio.

6.4. COMBOIOS

6.4.1. DIMENSÕES DOS COMBOIOS

As dimensões máximas dos comboios, considerando o conjunto empurrador/balsa(s), serão de 210 m de comprimento e 37 m de boca, exceto para os comboios que seguirem viagem nos trechos abaixo especificados:

Rio	Comprimento máximo (m)	Boca máxima (m)
Juruá	60 cheia /45 na vazante	15
Urucu	60	15
Madeira	150	30
Amazonas	210	37
Tapajós	181	37
Trombetas	181	37
Pará	181	37
Jari	181	37
Matapi	210	37
Solimões	210	37
Javari	80	18
Içá	110	22

Comboios com dimensões superiores ao especificado acima somente serão autorizados mediante o atendimento do contido na Seção IV do Capítulo 6 da NORMAM-204/DPC, que versa sobre os procedimentos gerais para homologação de comboios. Para tal, deverão ser observadas as dimensões e características dos Comboios Tipo, conforme item abaixo, homologados e autorizados a navegarem nas águas sob jurisdição da CFAOC e Agências subordinadas.

6.4.1.1. COMBOIOS TIPO HOMOLOGADOS PELA CFAOC

A Seção IV do Capítulo 6 da NORMAM-204/DPC contempla a sistemática para

homologação e autorização de Comboios que extrapolem os gabaritos acima estipulados. O quadro a seguir apresenta os Comboios Tipo homologados e autorizados a navegarem nas águas sob jurisdição da CFAOC e Agências subordinadas.

Autorização	Formação Longitudinal x Transversal	Dimensões Totais (m) Comprimento x Boca	Trecho navegável	Potência propulsiva
Portaria nº 63, de 08/04/2021	5x5 (25 barcaças)	331,4 x 53,3	Borba-AM a Itacoatiara-AM	4.290 HP
Portaria nº 196, de 17/12/2021	5x3 (15 barcaças) 4x4 (16 barcaças)	349,5 x 36 287,5 x 48	Borba-AM a Parintins-AM	3.414 HP
Portaria nº 40, de 27/02/2024	4x3 (12 barcaças)	278,5 x 36	Borba-AM a Parintins-AM	1.770 HP
Portaria nº 59, de 26/03/2024	5x6 (30 barcaças)	392,38 x 53,35	Borba-AM a Itacoatiara-AM	4.290 HP
Portaria nº 60, de 26/03/2024	3x3 (09 barcaças)	210,2 x 32	Borba-AM a Itacoatiara-AM	1.660 HP
Portaria nº 106, de 12/06/2024	5x4 (20 barcaças)	349,5 x 48	Borba-AM a Parintins-AM	3.414 HP

6.4.1.2. OUTROS REQUISITOS

Para os comboios que navegarão nos rios na jurisdição da Capitania Fluvial de Santarém (CFS), Capitania dos Portos da Amazônia Oriental (CPAOR), Capitania dos Portos do Amapá (CPAP), Capitania Fluvial de Tabatinga (CFT) e Capitania Fluvial de Porto Velho (CFPV), deverão ser consultadas as respectivas Normas e Procedimentos de cada Capitania, nos itens que versam sobre cada rio, cujas características básicas já estão constando na planilha acima, contudo existem outras orientações:

- NPCF-CFS: Rio Amazonas, Rio Tapajós e Rio Trombetas;
- NPCP-CPAOR: Área dos Estreitos (131 de cumprimento e 37 metros de boca) e Rio Pará;
- NPCF-CPAP: Rio Amazonas, Rio Jari, Rio Matapi e Furo do Salvadorzinho (Proibido o tráfego de comboios);
- NPCF-CFT: Solimões (A montante do Jutaí), Javari e Içá; e
- NPCF-CFPV: Rio Madeira.

Quando o comboio for composto por mais de uma balsa, no sentido longitudinal, as luzes de navegação devem ser instaladas na balsa mais de vante.

Deverá ser cumprido a alínea b) do item 5.15 e 5.16 da NORMAM-202/DPC para a altura mínima do passadiço do empurrador de modo a proporcionar uma visão segura para a navegação.

Para isso, deverá ser observada a seguinte fórmula:

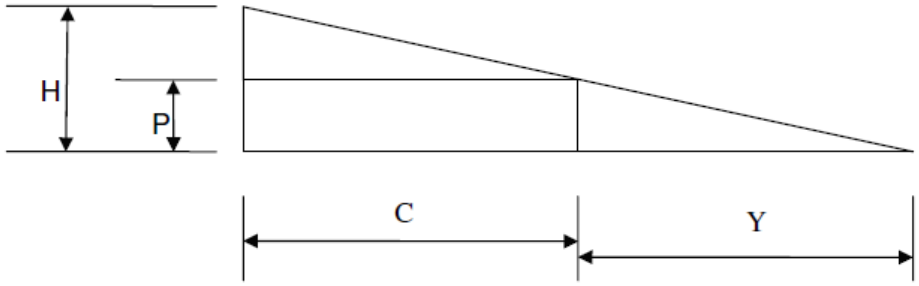

$$H = \frac{P \times (C+Y)}{Y}$$

Onde:
H = altura mínima do passadiço em relação à linha d'água;
C = comprimento do comboio;
P = altura de carga em relação à linha d'água (caso o condutor veja, do passadiço, a parte superior da proa da balsa de vante do comboio, considerar como P a altura da balsa de vante em relação à linha d'água);
Y = (2 x C) ou 500 metros, o que for menor (acordo item 5.16 da NORMAM-202/DPC).

6.4.2. ARRUMAÇÃO DA CARGA

6.4.2.1. BALSA - EMPURRADOR

IX) A arrumação da carga nas balsas não pode obstruir a visibilidade do passadiço, devendo ser garantida a visibilidade da água pela proa a uma distância menor que a equivalente ao comprimento do comboio;

X) A carga deverá estar estivada e peada de modo a não correr e não comprometer a estabilidade;

XI) Nas balsas que transportam carga geral, incluindo carretas, acompanhadas ou não do cavalo mecânico, **é proibido o transporte de pessoas quanto não for previsto no TIE/DPP/PRPM**. No entanto, o empurrador poderá transportar os profissionais não

tripulantes, caso apresente condições de habitabilidade regulamentares, equipamentos de salvatagem compatíveis com o número de pessoas, além de ter condições de estabilidade, comprovadas mediante estudo de estabilidade.

XII) As balsas que transportam veículos deverão possuir mecanismo para impedir o transbordo acidental, com 40 cm de altura, no mínimo, de proa a popa, e serem equipadas com olhais soldados, peias de cabo de aço de ½ polegada ou mais, com mão costurada ou abotoada (mínimo de 3 grampos), dispondo de macacos esticadores de 1 polegada, ou mais, com 2 parafusos, sendo 4 peias por veículo. Não é permitido usar um mesmo olhal para dois veículos.

XIII) Devem possuir, também, cavaletes de ferro, com reserva de capacidade para suportar o peso das carretas desacompanhadas do cavalo mecânico e um calço triangular para cada trem de rodas.

f) A balsa que se destine ao transporte de carga deverá possuir uma faixa marcada de forma indelével, definindo a área onde a carga será transportada. A faixa deverá possuir largura mínima de 5 centímetros e sua cor deve contrastar com a cor de fundo do convés.

g) No Item 0305.1 desta NPCF, versa sobre a amarração balsa empurrador.

6.4.2.2. BALSA – EMPURRADOR COM CONTÊINER ALOJAMENTO

IV. A empresa que realize transporte de caminhões poderá solicitar a Capitania a instalação de contêiner alojamento.

V. A empresa deverá apresentar os seguintes documentos para análise da Capitania e posterior emissão de Portaria:

- Planos de Arranjo Geral, Estudo de Estabilidade, Notas para Arqueação, Anotação de Responsabilidade Técnica assinada por Engenheiro Naval.
- Vistoria de constatação das alterações realizadas pelo GVI desta Capitania Fluvial.

c) Fica proibida o deslocamento e permanência dos motoristas nas boleias e outras partes do caminhão e quaisquer outras partes da balsa e empurradores, exceto no momento das refeições e higiene.

d) O trânsito de motoristas entre as embarcações do comboio deve ser supervisionado por tripulante devidamente qualificado e habilitado.

6.4.2.3. EMBARCAÇÕES DE TRAVESSIA

As pessoas não deverão permanecer no interior dos veículos enquanto a embarcação estiver em movimento. As balsas deverão possuir local abrigado, confortável e arejado e de preferência climatizado para os passageiros e condutores dos veículos, devendo o embarque e desembarque acontecer somente com a balsa firmemente amarrada.

b) Deverá ser alertado a todos os motoristas, pelo sistema de som de bordo, sobre o perigo de manter o motor em funcionamento.

c) As balsas que transportam veículos deverão possuir mecanismo para impedir o transbordo acidental, com 40 cm de altura, no mínimo, de proa a popa, e serem equipadas com olhais soldados, peias de cabo de aço de ½ polegada ou mais, com mão costurada ou abotoada (mínimo de 3 grampos), dispondo de macacos esticadores de 1 polegada, ou mais, com 2 parafusos, sendo 4 peias por veículo. Não é permitido usar um mesmo olhal para dois veículos.

d) Devem possuir, também, cavaletes de ferro, com reserva de capacidade para suportar o peso das carretas desacompanhadas do cavalo mecânico e um calço triangular para cada trem de rodas.

e) O transporte de cargas perigosas, tais como explosivos, tóxicas, radioativas, petróleo e seus derivados e gás engarrafado, será feito em viagem específica, sendo vedado o transporte simultâneo com passageiros e viaturas comuns, exceto se estes estiverem descarregados, admitindo-se caminhões-tanque com outros caminhões de carga, Viaturas Militares, Polícia Federal, do Corpo de Bombeiros Militar, Polícia Militar e Polícia Civil, desde que caracterizadas e sob responsabilidade exclusiva de tais Organizações.

f) O convés exposto que se destine ao transporte de carga deverá possuir uma faixa marcada de forma indelével, definindo a área onde a carga será transportada. A faixa deverá possuir largura mínima de 5 centímetros e sua cor deve contrastar com a cor de fundo do convés.

6.4.2.4. ACESSOS

a) A disposição da carga sobre o convés deve permitir o acesso da tripulação à proa, popa e ao comando da embarcação.

b) A carga sobre o convés deve permitir o acesso da tripulação:

I) Aos equipamentos de combate a incêndio;

II) Aos equipamentos de salvatagem; e

III) Equipamentos dos sistemas de amarração, fundeio e reboque.

c) Quando o acesso aos locais mencionados anteriormente se efetuar por cima da carga no convés ou através das bordas da embarcação, deverão ser instaladas balaustradas, passarelas ou bordas-falsas cuja altura mínima não poderá ser inferior a 1 metro, a fim de permitir a circulação da tripulação com segurança.

6.4.2.5. MARCAÇÃO

O convés exposto que se destine ao transporte de carga deverá possuir uma faixa marcada de forma indelével, definindo a área onde a carga será transportada. A faixa deverá possuir largura mínima de 5 centímetros e sua cor deve contrastar com a cor de fundo do convés.

6.4.3. TRANSPORTE DE MADEIRAS EM TOROS FLUTUANTES

6.4.3.1. EMBARCAÇÕES NECESSÁRIAS

Para jangadas com até 100 metros, deverá ser utilizada uma embarcação com tração suficiente para efetuar as manobras com segurança. Para jangadas com comprimento de até 200 metros, deverão ser utilizadas duas embarcações.

6.4.3.2. SINALIZAÇÃO

a) Diurna - seis bandeiras encarnadas, três por bordo em posição visível.

b) Noturna - luzes de navegação a meio comprimento da jangada, além das obrigatórias para os rebocadores.

6.4.3.3. DIMENSÕES MÁXIMAS

a) comprimento - 200 m

b) largura - 20 m

6.4.3.4. PROIBIÇÕES

Fundear, atracar e abarrancar a jangada obstruindo o canal navegável.

6.4.4. TRANSPORTE DE PRODUTOS INFLAMÁVEIS

10. É proibido o transporte de produtos inflamáveis em porões ou em ambientes confinados;

11. O transporte de botijões de GLP em embarcações classificadas para o transporte de carga poderá ser autorizado, desde que o Armador/Comandante obtenha junto à

Capitania autorização específica para este fim. Esta carga deverá ser transportada no convés principal e, portanto, estas embarcações deverão estar autorizadas a utilizar esse convés para o transporte de carga. Neste caso, não será admitido o transporte de passageiros junto ao convés; e

12. O transporte de botijões de GLP, para uso específico na cozinha da embarcação, está autorizado, desde que atenda aos requisitos das Normas da Autoridade Marítima para Embarcações Empregadas na Navegação Interior (NORMAM-202/DPC) e que esteja instalado fora dos compartimentos e em área afastada de passageiros.

6.4.5. TRANSPORTE DE MATERIAL E PASSAGEIROS

a) É proibido o transporte de passageiros fora dos locais adequados e aprovados para esse fim, tais como área de máquinas.

b) É proibido o transporte de passageiros e carga no mesmo convés, a não ser que esteja demonstrado claramente nos planos de arranjo geral e segurança da embarcação ser possível o transporte de passageiro e carga no mesmo convés. Conforme preconizado na NORMAM-202/DPC, tal possibilidade deve constar no Certificado de Segurança da Navegação.

c) É proibido o transporte de veículos de quatro rodas, nas embarcações de passageiros autorizadas a transportar carga no convés.

d) É proibido realizar transbordo de passageiros, tripulantes ou cargas, com as embarcações navegando ou fundeadas, sem a autorização.

e) É proibido manter tráfego de embarcações miúdas entre os navios de longo curso, cabotagem e/ou estrangeiras, e pontos de terra não alfandegados, bem como manter tal tráfego antes das visitas obrigatórias.

f) É proibido lançar lixo, detritos, fazer esgoto de porão ou de tanques que contenham poluentes, bem como permitir situações que favoreçam sua queda acidental nas águas.

g) É proibido às embarcações de passageiros o transporte de carga nos conveses acima do principal. O Comandante da embarcação será o responsável perante a Autoridade Marítima pelo cumprimento dos requisitos relativos ao transporte de carga no convés, devendo para isso assinar o Termo de Responsabilidade para o Transporte de Carga no Convés, conforme previsto na NORMAM-202/DPC.

h) A amarração da carga sobre o convés deve impedir seu movimento quando a

embarcação estiver navegando. É recomendável que a amarração da carga permita sua separação e até o seu alijamento, total ou parcial, em caso de perigo.

i) As características dos cabos, tensores, correntes, macacos esticadores e demais acessórios de amarração da carga sobre o convés devem ser tais que assegurem a imobilidade da carga e suportem seu peso em caso de deslocamentos. As amarrações feitas com cabos de capacidade reduzida em locais não apropriados são terminantemente proibidas.

j) É proibido manter embarcações a contrabordo sem a devida iluminação.

k) É proibido arriar embarcações de salvatagem para finalidade diferente da prevista, sem a autorização da Capitania dos Portos.

l) Todas as embarcações que trafegarem para os rios (e/ou afluentes) das jurisdições da Capitania Fluvial de Santarém (CFS), Capitania dos Portos da Amazônia Oriental (CPAOR), Capitania dos Portos do Amapá (CPAP) e Capitania Fluvial de Tabatinga (CFT) e Capitania Fluvial de Porto Velho (CFPV) deverão observar, além destas normas, as Normas e Procedimentos estabelecidos por aqueles Agentes da Autoridade Marítima.

6.5. DEVER DE INFORMAÇÃO

Os Comandantes e mestres das embarcações devem comunicar ao Agente da Autoridade Marítima do primeiro porto que demande qualquer irregularidade dos auxílios à navegação e qualquer imprecisão, obstáculo ou estorvo à navegação que encontrar, bem como acidentes ou fatos da navegação ocorridos com o seu navio ou embarcação. Quando se tratar de irregularidade dos auxílios à navegação e qualquer imprecisão, obstáculo ou estorvo à navegação, a comunicação poderá ser efetuada ao Centro de Hidrografia da Marinha (CHM), conforme o anexo constante dos folhetos quinzenais de Avisos aos Navegantes, intitulado “COLABORAÇÃO DOS NAVEGANTES E USUÁRIOS”.

SEÇÃO II
OBRAS, DRAGAGENS E EXTRAÇÃO MINERAL

6.6. OBRAS EM VIAS NAVEGÁVEIS

Em complemento ao previsto na NORMAM-303/DPC, e considerando as peculiaridades da área de jurisdição da CFAOC e OM subordinadas, poderá ser necessária a exigência de

documentos, informações e procedimentos adicionais não relacionados na norma referenciada.

Tal medida tem como propósito avaliar se o arranjo da obra pretendida comprometerá o ordenamento do espaço aquaviário, a segurança da navegação local, e ainda as atividades das instalações vizinhas.

Em especial nas questões envolvendo a construção de portos e terminais, incluindo ou não flutuantes, o Agente da Autoridade Marítima, a seu juízo, poderá:

a) Consultar previamente os seguintes órgãos e entidades:

- Administração dos Portos e Terminais (públicas ou privadas);
- Agência Nacional de Águas (ANA);
- Agência Nacional de Transportes Aquaviários (ANTAQ);
- Empresas de navegação;
- Órgãos ambientais;
- Prefeitura;
- Empresas de Praticagem; e
- Superintendência do Patrimônio da União (SPU).

b) Solicitar estudos adicionais, entre os quais os de manobrabilidade, com o propósito de avaliar as restrições operacionais dos portos/terminais e das embarcações que os utilizarão, bem como as interferências com as instalações adjacentes.

6.6.1. PONTES

Para a construção de pontes sobre os rios da jurisdição, o interessado deverá cumprir o contido no item 2.11 da NORMAM-303/DPC. Os interessados na execução da obra, quando da elaboração do projeto, para estabelecimento do vão-livre entre pilares e da altura livre, deverá atender aos seguintes parâmetros:

a) proporcionar um retângulo de navegação compatível com a navegação existente e sua perspectiva de desenvolvimento, independentemente de restrições artificiais já existentes na ocasião (pontes ou outras obras). Deverá estar posicionado sobre o canal navegável e sempre cortar transversalmente o canal navegável, de tal modo que as correntes existentes incidam sobre as embarcações pela sua proa ou popa. O vão-livre do retângulo de navegação deverá ser estabelecido a partir da largura dos pilares, abatendo o valor das respectivas dimensões das proteções contra colisões;

b) a boca e a altura (distância entre o ponto mais alto da embarcação e a sua linha de flutuação, considerada a embarcação com seu calado mínimo) das embarcações de maior porte que trafegam no local;

c) quando a ponte estiver situada em rio, considerar os níveis das mais altas águas navegáveis quando conhecidos ou os níveis correspondentes aos das enchentes históricas dos últimos 50 (cinquenta anos). Esse cálculo deverá ser baseado em dados transpostos de séries hidrológicas existentes para o local ou de postos hidrométricos vizinhos; e

d) quando situada em águas sujeitas à influência da maré, deverá ser considerado o nível da maré de sizígia, obtido das Tábuas de Marés, publicação editada anualmente pela DHN.

e) Os interessados serão ainda os responsáveis pelas seguintes seguranças:

- Sinalização diurna e noturna; e

- Proteção dos pilares, para evitar colisão direta de embarcações contra a estrutura da ponte.

6.6.2. PONTÕES

a) Os pontões (postos de combustíveis flutuantes) deverão ser dotados no que couber de todos os materiais de salvatagem pertinentes e no item 4.9 da Seção III do Capítulo 4 da NORMAM 202/DPC, dentre eles:

- barreiras de contenção fixa, e barreira de contenção plástica;

- mantas absorvedoras; e

- kit SOPEP (Shipboard Oil Pollution Emergency Plan) - composto por travesseiros Absorvente de Óleo e Derivados, cordões, produto granel absorvente, luva pvc ou nitrílica, óculos de segurança, pá anti-faisca, macacões e embalagens plásticas para acondicionamento do material absorvido dentre outros.

b) Fica estabelecida a distância mínima de cinquenta (50) metros entre os pontões instalados na jurisdição desta Capitania e Agências subordinadas.

c) O requerente deverá apresentar, no ato da solicitação do Parecer de interferência prévia, a Licença Ambiental emitida por Órgão competente da autarquia federal, estadual ou municipal, conforme o caso.

6.6.3. BARES FLUTUANTES, RESIDÊNCIAS E ESTABELECIMENTOS COMERCIAIS FLUTUANTES

a) Deverão estar regularizados perante a Marinha do Brasil, conforme a NORMAM 202/DPC (Embarcação) e NORMAM-303/DPC (Obras nas Margens). Além disso, devem-se cumprir os seguintes requisitos:

I) apresentar Estudo de Estabilidade, capacidade máxima de pessoas, Plano de incêndio com rotas de fuga demarcadas, iluminação de emergência, dotação de coletes e boias salva-vidas; e

II) deverão ser dotados de ETE – Estação de Tratamento de Efluentes, aprovados pelos Órgãos Ambientais do Estado e do Município, e de acordo com suas legislações pertinentes.

b) O requerente deverá apresentar, no ato da solicitação do Parecer de Interferência Prévia (PIP), a Licença Ambiental emitida por Órgão competente da autarquia federal, estadual ou municipal.

c) Sempre que fizer uso, estes estabelecimentos devem colocar boias de demarcação de áreas para banhistas e “Stand Up Paddle” (SUP).

6.6.4. PLANTA DE SITUAÇÃO

Nas Plantas de Situação deverão constar todas as obras já instaladas em um raio de cem (100) metros, de forma a garantir melhor apreciação do ordenamento do espaço aquaviário. As Plantas Finais de Situação deverão conter as mesmas informações desta alínea.

6.6.5. ACOMPANHAMENTO DE PROCESSOS

O proprietário de embarcação (Pontões, Píeres Flutuantes e outros) ou seu representante legal, ao protocolar o processo de inscrição de embarcação, transferência de jurisdição, transferência de propriedade, alteração de dados ou emissão de 2° Via de Título de Inscrição de Embarcação (TIE), deverá apresentar acompanhado dos documentos exigidos na NORMAM-202/DPC, uma Declaração de Dados Pessoais (Anexo 6-A), assinada pelo proprietário da embarcação, conforme o modelo do referido anexo, na qual deverá conter o número de telefone celular e e-mail do proprietário da embarcação, para recebimento de informações referentes ao andamento ou situação do respectivo processo.

6.7. BARRAGENS E ECLUSAS

Não aplicável.

6.8. DRAGAGENS

Os interessados em realizar dragagem, devidamente autorizado pelos órgãos competentes, deverão cumprir as determinações previstas no Capítulo 3 da NORMAM-303/DPC.

6.9. EXTRAÇÃO DE MINERAIS

Os interessados em realizar pesquisa, lavra, garimpo ou extração de areia, devidamente autorizado pelos órgãos competentes, deverão prestar informações formalmente a esta CF, conforme preconiza no capítulo 4 da NORMAM-303/DPC.

6.10. ATUALIZAÇÃO DE DOCUMENTOS NÁUTICOS

As obras e atividades afins em águas sob jurisdição brasileira (AJB), no que concerne ao ordenamento do espaço aquaviário e à segurança da navegação necessitam de parecer do Agente da Autoridade Marítima para sua execução, inclusive para atualização de documentos náuticos onde a obra estiver estabelecida, com o propósito de se garantir a segurança da navegação e a manutenção do ordenamento do espaço aquaviário na área.

Em decorrência, após a conclusão de obras nas vias navegáveis e dragagens realizadas, os responsáveis pelas mesmas deverão encaminhar à Capitania as Plantas Finais de Situação pertinentes aos projetos, apresentando as documentações, desenhos técnicos e plantas, particularmente aquelas relativas aos portos, terminais, píeres, marinas, pontes, etc., da área de jurisdição da CFAOC, conforme previsto na NORMAM-303/DPC. Estas serão encaminhadas ao Centro de Hidrografia da Marinha (CHM) para a atualização dos documentos náuticos.

Para as obras localizadas em áreas de rios não cartografados, o requisito acima é dispensado.

CAPÍTULO 7
DISPOSIÇÕES GERAIS
SEÇÃO I
DEVERES E SANÇÕES

7.1. DEVERES

O cumprimento das presentes normas é obrigatório para todos os armadores, proprietários de embarcações, estaleiros e carreiras, aquaviários, amadores, agências de navegação, proprietários de marinas, clubes e entidades desportivas náuticas, no que couber a cada segmento, e em acréscimo às demais regulamentações vigentes, atinentes ao prescrito na Lei nº 9.537 de 11 de dezembro de 1997 (Lei de Segurança do Tráfego Aquaviário - LESTA), na Lei 9.605 de 12 de fevereiro de 1998 (Lei de Crimes Ambientais) e na Lei nº 9.966 de 28 de abril de 2000 (Lei do Óleo).

É dever do Comandante da embarcação, além de outras obrigações legais pertinentes, cumprir e fazer cumprir a presente Norma, bem como conhecer, e divulgar aos tripulantes, todas as informações contidas nas NORMAM e demais documentos náuticos, tais como: Avisos aos Navegantes, “ROTEIRO”, Cartas Náuticas, Aviso Rádio Náutico e SAR e outros emitidos pela Diretoria de Hidrografia e Navegação da Marinha do Brasil.

7.1.1. DEVERES ADICIONAIS PARA OS COMANDANTES DE EMBARCAÇÕES DE TRANSPORTE DE PASSAGEIROS

Todo o Comandante de embarcação de transporte de passageiros deverá providenciar a devida demonstração de uso de coletes salva-vidas e demais equipamentos de salvatagem logo após a saída dos portos, seguindo as instruções constantes do Anexo 7-A desta Norma. Isto poderá ser feito por meio de exibição de filmes para os passageiros, que poderá, ainda, conter outras orientações sobre Segurança da Navegação.

Os tripulantes de embarcações de passageiros deverão estar uniformizados, identificando o nome e a categoria do fluviário, conforme especificado no capítulo 3 da Norma da Autoridade Marítima para o Uso de Uniformes da Marinha Mercante Nacional (NORMAM-111/DPC).

As empresas de navegação que desejarem utilizar uniformes em desacordo com a Norma em vigor, deverão apresentar requerimento a esta Capitania Fluvial para apreciação e homologação.

7.1.2. DEVERES ADICIONAIS PARA OS COMANDANTES DE EMBARCAÇÕES DE TRANSPORTE ESCOLAR

a) Os Municípios que receberam estas embarcações deverão envidar esforços para sua plena manutenção, operação regular, bem como ser conduzida por pessoa habilitada para o transporte seguro de seus alunos, dando ênfase ao material de salvatagem individual (coletes e boias salva-vidas).

b) O emprego destas embarcações para outros fins é proibido, exceto no caso de emergência.

c) A fim de preservar a integridade física das dos passageiros, determina-se a leitura do Anexo 7-A e a ministração das seguintes instruções:

- Procedimentos em caso de emergências (incêndio, alagamento, abalroamento e naufrágio);
- Identificação do local da área de reunião;
-Exercício de vestimenta dos coletes salva-vidas por todos os tripulantes e alunos; e
-Instruções no caso de homem ao mar/rio.

-A responsabilidade do cumprimento desta ordem é do Comandante da embarcação.

7.1.3. MARINAS, CLUBES NÁUTICOS, ENTIDADES DESPORTIVAS NÁUTICAS, ESTABELECIMENTOS E PESSOAS FÍSICAS CADASTRADAS

As Marinas, Clubes Náuticos, Entidades Desportivas Náuticas, Estabelecimentos e Pessoas Físicas cadastradas para o treinamento náutico que estão situados nos Estados do Amazonas, Acre e Roraima deverão ser obrigatoriamente cadastradas na CFAOC, Agência de Cruzeiro do Sul, Agência de Eirunepé, Agência de Itacoatiara, Agência de Parintins, Agência de Tefé e Agência de Caracaraí, conforme a área de jurisdição, de acordo com as Normas da Autoridade Marítima para Amadores, Embarcações de Esporte e Recreio e para Cadastramento das Marinas, Clubes Náuticos e Entidades Desportivas Náuticas (NORMAM-211/DPC).

Marinas, Clubes, Entidades Desportivas Náuticas, Estabelecimentos e Pessoas Físicas Cadastradas para o treinamento náutico tem a obrigação de colaborar com a segurança da navegação, a salvaguarda da vida humana no mar, a prevenção da poluição do meio hídrico,

e o ordenamento do espaço aquaviário. Desta forma, deverão cumprir/seguir as seguintes determinações/orientações:

I) A Capitania Fluvial da Amazônia Ocidental (CFAOC) faculta a atividade em tela para utilização condicional de curta duração.

Tal ato administrativo caracteriza-se como unilateral, precário e discricionário quanto à decisão de outorga e revogação.

II) A precariedade e o caráter unilateral e discricionário da autorização desoneram a administração do dever de observar o burocrático processo administrativo para revogar o ato concessivo.

III) A revogação da autorização é medida sumária que independe de prévia oitiva do particular, podendo ser feita a qualquer momento, não cabendo direito à indenização por parte da Marinha do Brasil (CFAOC).

IV) A CFAOC fará inspeções periódicas para verificar a qualidade dos treinamentos ministrados.

V) As Escolas Náuticas, Marinas e Instrutores Cadastrados devem informar com antecedência de no mínimo de sete (7) dias úteis, a inclusão de novos recursos instrucionais, incluindo embarcações e/ou instrutores, a fim de permitir a atualização do Cadastro da empresa junto à Capitania.

VI) Marinas, clubes, entidades desportivas náuticas, estabelecimentos e pessoas físicas cadastrados para o treinamento náutico devem informar com antecedência mínima de três (3) dias úteis antes dos dias das aulas práticas, a data e o período de duração das aulas (horário de início e término), bem como o local de embarque, desembarque, percurso, nome completo e CPF do(s) aluno (os) e nomes das embarcações que serão utilizadas. Caso contrário, os alunos que comparecerem para a inscrição não poderão realizar a avaliação.

VII) Marinas, clubes, entidades desportivas náuticas, estabelecimentos e pessoas físicas cadastrados para o treinamento náutico devem informar em até dois (2) dias úteis após as aulas práticas, o nome completo e o CPF do (os) aluno (os) faltoso(s).

VIII) A exibição de documento de identificação é obrigatória no momento da inspeção, salvo quando o Inspetor julgar que tal identificação prejudicará a eficácia da fiscalização, hipótese em que deverá fazê-lo após a verificação física.

IX) O Inspetor Naval somente poderá exigir a apresentação de documentos após sua devida identificação.

X) Os empregadores, tomadores e intermediadores de serviços, empresas, instituições, associações, órgãos e entidades de qualquer natureza ou finalidade envolvida no processo de certificação de candidatos a Arrais Amador e Motonauta, são sujeitos à inspeção e ficam, pessoalmente ou por meio de seus representantes legais, obrigados a franquear aos Inspetores Navais o acesso aos estabelecimentos, respectivas dependências e locais de trabalho, bem como exibir os documentos e materiais solicitados para fins de inspeção.

XI) As inspeções, sempre que necessário, serão efetuadas de forma imprevista, cercadas de todas as cautelas, na época e horários mais apropriados à sua eficácia.

As determinações para o cumprimento de ações decorrentes da Inspeção deverão ser comunicadas por escrito.

XII) Os instrutores (Amadores ou equivalentes) deverão cumprir rigorosamente o previsto no Anexo 5-E da NORMAM 211/DPC, no Atestado de Treinamento para Arrais Amador e Anexo 3-B da NORMAM 212/DPC , Atestado de Treinamento para Motonauta, sendo corresponsáveis com os Diretores pelo seu preenchimento e responderão administrativamente, civil ou penalmente por todas as informações neles constantes. Os instrutores deverão possuir os seguintes requisitos:

XIII) Estar com suas respectivas Carteiras de Habilitação de Amador (CHA) dentro do prazo de validade e, se CPA, MSA, ARA ou outros profissionais equivalentes (CIR), possuir no mínimo dois (2) anos de habilitação.

XIV) Ter capacidade técnica comprovada para ministrar aulas práticas e teóricas. Esta capacidade deverá ser verificada durante a visita da equipe da Capitania Fluvial da Amazônia Ocidental para Cadastramento ou Renovação de Cadastro da Escola Náutica, que fará uma avaliação dos seus conhecimentos, por meio de uma aula prática que será ministrada pelo instrutor, abrangendo os assuntos do anexo 5-A da NORMAM-211/DPC. O resultado será encaminhado ao Capitão dos Portos que decidirá se o mesmo preenche os requisitos necessários; e

XV) Estar sem pendências legais junto à Autoridade Marítima (Notificações, multas, dívidas, arrolado em Inquérito Administrativo sobre Acidentes e Fatos da Navegação, etc).

O Plano de Treinamento e o Controle de Embarque seguirão a sinopse dos cursos a serem oferecidos, com respectivas cargas horárias, conforme preconizado no anexo 5-A da NORMAM-211/DPC, respeitando as seguintes determinações:

Para a categoria de Motonauta serão contabilizados apenas sete (7) alunos/dia por instrutor e moto aquática cadastrada, uma vez que deverão cumprir as seguintes determinações:

FUNCIONAMENTO	
Expediente	08h00 às 18h00
Horário de Almoço	12h00 às 13h00

QUANTIDADE DE ALUNOS	
Realização de manobras e técnicas de pilotagem	1 (uma) hora/por aluno/por moto aquática com respectivo instrutor cadastrado.
Demais assuntos	2 (duas) horas para a turma.

Para Arrais Amador serão contabilizados apenas oito (8) alunos/dia por instrutor e lancha de esporte e/ou recreio cadastrada, respeitando a lotação da mesma, uma vez que deverão cumprir as seguintes determinações:

FUNCIONAMENTO	
Expediente	08h00 às 18h00
Horário de Almoço	12h00 às 13h00

QUANTIDADE DE ALUNOS	
Execução de manobra de atracação, desatracação, fundeio e suspender	30 minutos / por aluno / por lancha com respectivo instrutor cadastrado.
Demais assuntos	5 horas para a turma

Caso na apresentação da Lista de alunos haja inconsistência quanto ao número de alunos que realizaram aula, o documento será devolvido para as marinas, clubes, entidades desportivas náuticas, estabelecimentos e pessoas físicas cadastradas para o treinamento náutico e a inscrição destes alunos não será realizada e estes responderão administrativamente;

As aulas realizadas em lanchas não cadastradas e não identificadas, com a logo “Treinamento Náutico”, não serão contabilizadas e a Marina responderá administrativamente;

Durante as ações de fiscalização um Inspetor Naval poderá acompanhar a instrução a bordo das embarcações e realizará a verificação das aulas práticas em consonância com a

NORMAM-211/DPC e esta Norma, por meio da Lista de Verificação de Aula Prática de Amador (Anexo 5-C);

As Escolas Náuticas cadastradas e localizadas em Manaus deverão se apresentar no ponto P1, em frente a esta Capitania Fluvial, para verificação de presença e realização da aula prática, conforme o Anexo 5-C.

PONTO	LATITUDE	LONGITUDE
P1	03° 08’ 08” S	060° 02’ 03” W

As marinas, clubes, entidades desportivas náuticas em complementação a NORMAM-211/DPC, visando à adoção de medidas preventivas para salvaguarda da vida humana, a segurança da navegação e a prevenção da poluição no mar, deverão cumprir as seguintes determinações:

Enviar, até o dia 15 de janeiro de cada ano, a Lista de Embarcações (Anexo 7-B) atualizada por e-mail (cfaoc.secom@marinha.mil.br); e

Deverão, sempre que a referida lista sofrer alterações, enviá-la constando os dados das embarcações que saíram ou entraram do quadro de embarcações associadas das respectivas marinas, clubes, entidades desportivas náuticas.

Torna-se obrigatório por parte das marinas, clubes, entidades desportivas náuticas, estabelecimentos e pessoas físicas cadastrados para o treinamento náutico, a fim de lançarem na água as embarcações de esporte e/ou recreio dos seus associados ou usuários, realizar a Lista de Verificação para Embarcações de Esporte e/ou Recreio junto com o condutor e/ou proprietário (Anexo 5-F da NORMAM-211/DPC), e solicitar que cumpram os seguintes requisitos:

I) Condutor habilitado de posse da Carteira de Habilitação de Amador (CHA) ou documento equivalente na validade, conforme a alínea d) do item 5.3 da NORMAM-211/DPC;

II) Embarcação inscrita e com as documentações pertinentes a bordo, conforme o capitulo 4 da NORMAM-211/DPC; e

III) A embarcação com a dotação obrigatória de segurança, conforme o item 4.33 da NORMAM-211/DPC.

IV) O transporte de passageiros, incluindo crianças, e ademais determinações previstas no Item 4.33 da NORMAM-211/DPC; e

V) Os condutores não estejam em estado de embriaguez alcoólica, consumindo álcool ou sob efeito de substância tóxica de qualquer natureza, conforme Item 3.10 da NORMAM-301/DPC.

VI) Marinas, clubes, entidades desportivas náuticas, estabelecimentos e pessoas físicas cadastrados para o treinamento náutico deverão informar a Capitania Fluvial da Amazônia Ocidental, visando à adoção de medidas administrativas cabíveis, caso o proprietário da embarcação de esporte e/ou recreio decida sair em descumprimento à alínea anterior, por meio do Disque Denúncia (Sala de Estado/WhatsApp): (92) 2123-4900/(92) 99302-5040.

VII) O não cumprimento das determinações previstas nas normas da autoridade marítima e nesta Norma, tornam imperativas e sumárias a adoção por parte do titular desta Capitania das seguintes penalidades, quanto ao funcionamento das Marinas, Escolas Náuticas, Entidades Desportivas Náuticas e Estabelecimentos e Pessoas Físicas cadastradas para o treinamento náutico:

- Advertência;
- Suspensão Temporária; ou
- Cancelamento do Cadastramento.

Quando em instrução para a obtenção do “Atestado de Treinamento náutica para Arrais Amador” e “Atestado de Treinamento para Motonauta” é permitido ao aluno conduzir a embarcação, desde que devidamente supervisionado pelo instrutor que pelo correto cumprimento das regras estabelecidas no RIPEAM e a segurança da embarcação. Tal instrução deverá ser realizada em área que não cause interferência com a realização de outras atividades náuticas e, principalmente, com banhistas.

Para cadastramento ou renovação do cadastramento das marinas, clubes, entidades desportivas náuticas, estabelecimentos e pessoas físicas cadastrados para o treinamento náutico deverão manifestar-se formalmente com antecedência de três (3) meses, cumprindo o item 6.3. da NORMAM-211/DPC, no qual será submetido a uma nova avaliação por uma equipe desta Capitania.

7.2. AMADORES

A definição de “Amador” está contida na NORMAM-211/DPC, bem como as regras para habilitação nessa categoria. Para realizar a prova de habilitação de amador, o interessado deverá comparecer, durante o horário do expediente, na CFAOC, Agência de Cruzeiro do Sul, Agência de Eirunepé, Agência de Itacoatiara, Agência de Parintins, Agência de Tefé e Agência de Caracaraí, conforme a área de jurisdição, entregar os documentos exigidos e preencher uma ficha de inscrição.

7.3. INFRAÇÕES E SANÇÕES

Constatada infração ao Decreto nº 2.596 de 18 de maio de 1998 (Regulamenta a Lei de Segurança do Tráfego Aquaviário - RLESTA) e ao Decreto nº 4.136 de 20 de fevereiro de 2002 (Regulamenta a Lei do Óleo e aplica sanções penais e administrativas dispostas na Lei de Crimes Ambientais) a equipe de inspeção naval deverá lavrar a notificação ao suposto responsável, devendo seguir as seguintes fases:

a) **Análise da notificação e lavratura do auto de infração:**

Após o transcurso do prazo para apresentação da defesa prévia da notificação ou da sua análise, será lavrado o Auto de Infração que, após ciência pelo suposto infrator e/ou Recurso do auto de infração, será julgado.

b) **Julgamento do Auto de Infração**

Após o Julgamento e ciência do suposto infrator, este terá cinco dias para apresentar o primeiro recurso.

c) **Julgamento do recurso em 1ª Instância**

Após o Julgamento do recurso o suposto infrator terá cinco dias para apresentar recurso final.

d) **Julgamento do recurso em 2ª Instância**

Após o julgamento do recurso final o suposto infrator terá que cumprir a penalidade estabelecida.

e) **Cumprimento da penalidade**

Após a finalização do período de recurso o infrator deverá proceder da seguinte forma:

I) Pagamento da Multa por GRU gerada pelo sistema de pagamento no sítio eletrônico da DPC;

II) Cumprimento da pena de suspensão estabelecida por Portaria do Capitão dos Portos e registrada no Sistema de Gerenciamento de Aquaviários (SISAQUA);

III) Para multas com valor superior a R$ 999,00 e três meses de ciência pelo infrator deverá ser lançada em dívida ativa da união por intermédio do sistema inscreve fácil.

7.4. ASSINATURA NA DECLARAÇÃO DO ENGENHEIRO RESPONSÁVEL E NO TERMO DE RESPONSABILIDADE DE CONSTRUÇÃO/ALTERAÇÃO

a) Considerando exclusivamente as embarcações miúdas, o Responsável Técnico pela avaliação das condições de segurança, operacionalidade e discriminação das características da embarcação, que devem constar na Declaração de Construção (comprimento, boca, pontal, material do casco, lotação e motorização) poderá ser engenheiro naval, tecnólogo em construção naval ou tecnólogo em operação e administração de sistemas de navegação fluvial, conforme previsto na NORMAM-202/DPC; e

b) Para as demais embarcações, a Declaração do Engenheiro Responsável (Anexo 3-H da NORMAM-202/DPC) ou o Termo de Responsabilidade de Construção/Alteração (Anexo 3-D da NORMAM-211/DPC) deverão ser assinados por engenheiro naval.

7.5. INSCRIÇÃO DE CANOAS INDÍGENAS E RIBEIRNHAS MENORES QUE 12 METROS

Será considerada embarcação indígena/regional e/ou tradicional qualquer tipo de embarcação construída de madeira por seu proprietário, com ou sem propulsão, e deverá apresentar as seguintes especificações:

I) Tipo de material do casco: Madeira;

II) Forma do casco: canoa;

III) Propulsão: motor com potência compatível ao tamanho da embarcação; e

IV) Atividade: comercial previsto nas Normas da Autoridade Marítima para embarcações Empregadas na Navegação Interior (NORMAM-202/DPC) ou não comercial prevista nas Normas da Autoridade Marítima para Amadores, Embarcações de Esporte e/ou Re-

creio e para Cadastramento e Funcionamento das Marinas, Clubes e Entidades Desportivas Náuticas (NORMAM-211/DPC);

A navegação desse tipo de embarcação obedecerá aos critérios estabelecidos pela Capitania e Agências subordinadas, atendendo aos critérios de segurança e, dessa forma, poderão trafegar, próximo as margens e nos igarapés, não sendo permitido o tráfego no canal (centro) do rio, em período noturno e em mau tempo.

A Inscrição, o registro e a habilitação (aquaviário/amador), obedecendo aos seguintes requisitos:

- Requerimento do interessado;
- Pagamento de GRU ou dispensado pelo Capitão dos Portos para moradores de comunidades indígena e ribeirinhas;
- Assinatura do Termo de Responsabilidade;
- Declaração de Atividade;
- Documentos de identificação, previstos nas Normas da Autoridade Marítima para Amadores, Embarcações de Esporte e/ou Recreio e para Cadastramento e Funcionamento das Marinas, Clubes e Entidades Desportivas Náuticas (NORMAM-211/DPC)
- Declaração de construção, conforme anexo (2-O da NORMAM-202/DPC);
- Nota fiscal do motor ou declaração de propriedade; e
- Notas de Arqueação.

7.6. INSCRIÇÕES DE EMBARCAÇÕES REGIONAIS ARTESANAIS INDÍGENAS/RIBEIRINHAS ACIMA DE 12M MENORES QUE 20 AB

As embarcações acima de 12 metros com AB menor que 20 poderão ser inscritas na categoria Esporte e/ou recreio, carga e passageiro e passageiros (até 12 passageiros) com dispensa do Anexo 3-D assinado por Engenheiro Naval, tendo que apresentar as seguintes características:

a) Artesanais;

b) Regionais (indígenas/ribeirinhas);

c) Comprimento total: 12 a 15 metros;

d) Material do casco: madeira;

e) Potência do motor: até 15 HP; e

f) Possuir apenas um convés.

A Capitania e Agências Subordinadas, nestes casos, cumprirão o contido na Seção VIII, do Capítulo 6, da NORMAM-02/DPC, em especial o contido no Anexo 6-G, desta forma, poderá ser suprimida a necessidade da assinatura do responsável técnico com registro no CREA, para inscrição das embarcações de proprietários que não possuem recursos financeiros para custear as despesas referentes aos serviços prestados para emissão do ART por análise dos militares do setor de Cadastro.

7.7. TRANSPORTE DE COMBUSTÍVEIS POR PEQUENAS EMBARCAÇÕES REGIONAIS INDÍGENAS/RIBEIRINHAS PARA COMUNIDADES DISTANTES DAS CIDADES

A CFAOC e as Agências subordinadas, excepcionalmente, poderão autorizar o transporte de combustível em pequenas embarcações regionais indígenas/ribeirinhas de madeira com as seguintes características:

a) Para transporte de botijões de GLP, com no máximo 13 Kg de massa líquida, por botijão:

I) as embarcações com AB menor ou igual a 10 estão limitadas ao transporte de no máximo **cinco (5) botijões**;

II) as embarcações com AB maior que 10 e menor ou igual a 20 estão limitadas ao transporte de no máximo **sete (7) botijões**;

III) as embarcações com AB maior que 20 e menor ou igual a 50 estão limitadas ao transporte de no máximo **dez (10) botijões**;

IV) para embarcações com mais de um convés são mantidas as mesmas quantidades mencionadas, devendo o transporte dos botijões ser efetuado no convés inferior, **em todas as situações, separadamente dos passageiros**.

b) Para Transporte de óleo diesel, gasolina e lubrificantes:

I) essas mercadorias devem ser acondicionadas em embalagens apropriadas para o seu transporte e vedadas para evitar a possibilidade de vazamentos;

II) as embalagens devem ser peadas e armazenadas na parte de vante da embarcação nas proximidades da proa. Devem ser mantidas cobertas por lona e com a viso externo indicando que trata de óleo diesel, gasolina ou lubrificante; e

III) os combustíveis e lubrificantes devem ser transportados separadamente dos passageiros.

c) Requisitos adicionais de segurança para o transporte:

I) Os botijões devem ser sempre armazenados em locais ventilados para que, no caso de eventuais vazamentos não ocorra acúmulo de gás no ambiente;

II) Não armazenas os botijões em locais fechados tais como porões, armários e embaixo de pias;

III) Não posicionar os botijões próximos de tomadas elétricas, ralos e grelhas de escoamento de água. Recomenda-se um distanciamento mínimo de 1,5 m; e

IV) Dispor de avisos de proibido fumar nas embarcações em locais visíveis e de forma legível;

V) A quantidade a ser transportada tanto de botijões quanto de embalagens contendo gasolina, óleo diesel ou lubrificante não pode afetar a estabilidade, flutuabilidade e a manobrabilidade da embarcação, bem como, a movimentação das pessoas no seu interior, sendo importante avaliar o possível excesso de peso na embarcação, sendo passível de notificação caso o tripulante da embarcação coloque sobrepeso na embarcação.

7.8. REBOQUE DE EMBARCAÇÕES UTILIZADAS EM PESCA ESPORTIVA

O reboque de embarcações miúdas por embarcações de esporte e/ou recreio de médio e grande porte utilizadas na prática de pesca esportiva deverão seguir os seguintes requisitos:

7.8.1. COMPRIMENTO DO DISPOSITIVO DE REBOQUE

O comprimento máximo do dispositivo, incluindo os cabos de reboque e as embarcações a serem rebocas, deve ser de até 50% do comprimento total da embarcação que esteja efetuando o reboque.

7.8.2. QUANTIDADE DE EMBARCAÇÕES A SEREM REBOCADAS

A quantidade máxima de embarcações a serem rebocadas será estabelecida de acordo com o comprimento total da embarcação que esteja efetuando o reboque, devendo obedecer ao número de até (uma) embarcação miúda para cada 2 (dois) metros da embarcação do reboque.

7.8.3. INSTRUÇÕES GERAIS

a) O cabo de reboque deverá ser composto por fibra sintética (poliéster, nylon ou polipropileno), ficando proibido o uso de cabos de aço.

b) O reboque das embarcações só será permitido durante a luz do dia, ficando proibido o tráfego dos dispositivos durante a noite e/ou após o pôr do sol.

c) Durante o período noturno, as embarcações rebocadas devem ser amaradas a contrabordo das embarcações que esteja efetuando o reboque ou, caso não seja possível, todas as medidas possíveis devem ser tomadas para indicar a natureza da ligação entre a embarcação d reboque e as embarcações rebocadas, em particular, iluminando-se o cabo de reboque.

d) A largura máxima do dispositivo de reboque, caso as embarcações rebocadas sejam posicionadas a contrabordo uma das outras, fica limitada à medida da metade da dimensão da boca da embarcação que esteja efetuando o reboque.

ANEXO 2-A

MARINHA DO BRASIL
CAPITANIA FLUVIAL DA AMAZÔNIA OCIDENTAL

ENCAMINHAMENTO DAS INFORMAÇÕES SOBRE OCORRÊNCIA DE PERDA OU PERDA PROVÁVEL DE MERCADORIAS PERIGOSAS EM ÁGUAS SOB JURISDIÇÃO NACIONAL

1 – ENCAMINHAMENTO DAS INFORMAÇÕES

As informações deverão ser enviadas pelo Comandante do navio, sem demora, conforme adiante indicado, no caso de perda ou de perda provável, de mercadorias perigosas acondicionais:

a) à estação costeira apropriada mais próxima (precedida do sinal de segurança, se o acidente afetar a segurança da navegação);

b) utilizar o formato padrão de acordo com a alínea *a* do item 2 e nas frequências ou subfaixas apropriadas (faixas de 405-525 Khz, 1.605-2 850 Khz ou 156-174 Khz);

c) à estação costeira mais apropriada que opere em alta frequência (HF) ou usando o sistema INMARSAT, se o navio não estiver dentro do alcance da estação rádio que opere em frequência média (MF) ou em frequência muita alta (VHF); e

d) para a estação costeira de um Sistema de informações de Navios, quando a embarcação se encontrar dentro ou perto de uma área marítima para qual esse Sistema tenha sido estabelecido. Em águas brasileiras, as informações deverão ser endereçadas ao SALVAMAR BRASIL.

2 – TEOR DAS INFORMAÇÕES

a) A mensagem inicial sobre qualquer perda ou perda provável de mercadorias perigosas acondicionadas deverá ser imediatamente transmitida e conter informações sobre a ocorrência, obedecendo ao seguinte formato:

1) SISTEMA IDENTIFICADOR

Estação rádio costeira – BELÉM RÁDIO – PPL ou Sistema de Informação para Navios (SALVAMAR BRASIL em Águas Jurisdicionais Brasileiras);

2) TIPO DA MENSAGEM

“Mercadoria perigosa perdida no rio”;

3) PREFIXOS

A – Nome e indicativo de chamada ou de identificação da estação do navio;

B – Data e hora, em grupo de seis algarismos, sendo os dois primeiros relativos ao dia do mês e os quatro últimos às horas e minutos, referidas a Hora Média de Greenwich (HMG), seguidos do mês;

C – Posição na hora da ocorrência, em grupo de quatro algarismos, informando a latitude em graus e minutos, seguidos da letra N (Norte) ou S (Sul) e outro grupo de cinco algarismo, informando a longitude em graus e minutos seguidos da letra E (Leste) ou W (Oeste);

D – Marcação verdadeira e distância de uma posição em terra facilmente identificável (opção em relação a C):

I – Resumo de pormenores do acidente:

XIV) nome(s) técnico(s) correto(s) das mercadorias;

XV) número ou números UN (número das Nações Unidas);

XVI) classe ou classes de perigo, segundo a classificação IMO;

(4) estimativa da quantidade e prováveis condições das mercadorias;

(5) se a mercadoria flutuou ou afundou;

(6) se a perda está continuando; e

(7) causa da perda.

II – Resumo dos pormenores relativos às condições de tempo, vento e rio;

III – nome e endereço telegráfico do representante do navio para fornecimento de informações (afretador ou agente local, etc); e

IV – Tipo e dimensões do navio.

OBSERVAÇÕES:

a) Mensagens suplementares deverão ser enviadas, como necessário, a fim de fornecer informações adicionais; conforme se tornem disponíveis ou sejam solicitadas.

b) Quando apropriado, arranjos adequados deverão ser feitos, a fim de que essas informações sejam complementadas, logo que possível, pela lista completa de mercadorias ou pelo manifesto de carga, plano de carga, pormenores sobre danos ao navio e provável estado da carga. Tais informações podem ser fornecidas pelos armadores ou pelos afretadores do navio ou por seus agentes.

ANEXO 3-A

MARINHA DO BRASIL

CAPITANIA FLUVIAL DA AMAZÔNIA OCIDENTAL

MODELOS DE PLACAS A SEREM COLOCADAS EM CADA CONVÉS DE BARCOS DE PASSAGEIROS OU EM BALSAS DE TRAVESSIA

I – EM IDIOMA PORTUGUÊS

NOME DA EMBARCAÇÃO

DE ACORDO COM A NORMA DA CAPITANIA DOS PORTOS, COMUNICAMOS:

1. LOTAÇÃO DE PASSAGEIROS E CAPACIDADE DE CARGA:
PORÃO: _____
CONVÉS PRINCIPAL: _____
CONVÉS SUPERIOR: _____

2. LOCAL DE GUARDA DOS COLETES SALVA-VIDAS:

3. TELEFONES ÚTEIS:
CAPITANIA FLUVIAL DA AMAZÔNIA OCIDENTAL (CFAOC): (92) 2123-4900
DISQUE SEGURANÇA DA NAVEGAÇÃO: 0800-280-7200 (GRATUITO)
TELEFONE DA EMPRESA: _____

Observação: O tamanho da placa deverá ser de 1,00m por 0,80m.

II - EM IDIOMA INGLÊS

VESSEL NAME

ACCORDING TO THE HARBOUR MASTER´S RULES, CAPTAIN INFORMS THAT:

1. PASSENGERS / CARGO CAPACITIES:
CARGO DECK: _____
MAIN DECK: _____
UPPER DECK: _____

2. LIFE JACKETS STOWAGE AREA:

3. USEFUL TELEPHONE NUMBERS:
WESTERN AMAZON FLUVIAL CAPTAINCY (CFAOC): +55 (92) 2123-4900
INFORMATION/ COMPLAINTS/ ACCIDENT REPORTS: 0800-280-7200 (TOLL-FREE)
VESSEL COMPANY: _____

Observation: Size of plate shall be of 1,00m per 0,80m.

ANEXO 4-A

MARINHA DO BRASIL

CAPITANIA FLUVIAL DA AMAZÔNIA OCIDENTAL

LISTA DE EMPRESAS DE REBOCADORES DISPONÍVEIS

1) Ocidental Transportes e Navegação LTDA
Endereço: Rua Taqueirinha, nº 24, Centro – Manaus – CEP 69005-420 – AM.
Telefone: (92) 3233-8405.

2) Chibatão Navegação e Comércio LTDA
Endereço: Rua Zebu, nº 201, Colônia Oliveira Machado – Manaus – CEP 69073-670 – AM.
Telefone: (92) 2127-1015.

ANEXO 4-B

MARINHA DO BRASIL
DIRECTORATE OF PORTS AND COAST - BRAZIL
CAPITANIA FLUVIAL DA AMAZÔNIA OCIDENTAL
PILOT CARD

SHIP'S PARTICULARS

Name: _____ Call sign: _____ Flag: _____

Ower: _____ Operator: _____ Year of delivery: _____

Gross Tonnage: _____ Loa: _____ (m) Breadht: _____ (m)

Draught Fwd: _____ (m) Draught aft: _____ (m) Max. Draught: _____ (m)

Port Anchor: _____ (Shackles) Stbd anchor: _____ (Shackles) Astem anchor: _____ (Shackles)

Cargo on Board: _____ Last Port: _____ Next Port: _____

ENGINE

Type of Engine: _____ Max power: _____(kw) Astern power: _____ (% of full ahead)

Time Full Ahead to Full Astern: _____s Time limit astern: _____ (min) Max. Number of cons starts: _____

Time Full Ahead to Full Astern: _____s Time limit astern: _____ (min) Max. Number of cons starts: _____

Engine RPM	Loaded		Ballast	Engine	RPM	Loaded	Ballast
	Order	Pitch	Speed Speed	Order	Picht		Speed Speed
Full Ahead:	____	_____	_____	Full Astern:	_____	_____	_____
Half Ahead	____	_____	_____	Half Astern:	_____	_____	_____
Slow Ahead:	____	_____	_____	Slow stern:	_____	_____	_____
Dead Slow Ahead:	____	_____	_____	Dead Slow Astern:	_____	_____	_____

STEERING

Rudders: _____ (number) Maximum Angle: _____ Rudder angle ofr neutral effect: ____

Time hard-over to hard-over: ____ (sec) Bow Thruster Power: ____(kw)

Ster Thruster Power:_____ (kw)

EQUIPMENTS CHECKED AND READY FOR USE

Windlass:	Yes/No	Echo Sounder	Yes/No	VHF	Yes/No
Mooring Winches:	Yes/No	Magnetic Compass	Yes/No	Main Engine	Yes/No
Whistle:	Yes/No	Gyro Compass	Yes/No	Navigation Lights	Yes/No
X-Band Radar	Yes/No	Steering Gear	Yes/No	Engine Telegraphs	Yes/No
S-Band Radar	Yes/No	Rudder Angle Indicator		Yes/No	
	Maneuvering Characterisitcs		Yes/No		
RPM/Picht Indicador		Yes/No		Signalling Lamp:	Yes/No
	Pilot Transfer Arrangements		Yes/No		

_____	_____	_____/____/_____
MASTER'S NAME	PILOT'S NAME	DATE

ANEXO 4-C

MARINHA DO BRASIL
CAPITANIA FLUVIAL DA AMAZÔNIA OCIDENTAL

MARITIME AUTHORITY DIRECTIONS FOR PILOTS

According to ordinance 0009/2000 from Harbour Master of the Amazônia Ocidental, in additional to the filling in the pilot card, it is necessary to verify the items below and to send immediately report to Brazilian Maritime Representative Authority.

LISTA DE VERIFICAÇÃO DO PRÁTICO

EQUIPAMENTOS	**VERIFICAÇÃO**	**RESULTADO**
UM RADAR (opera na freq. 9 GHz) SOLAS, Cap. V, Reg. 12-g Todo navio SOLAS cumpre esta regra	Checar o funcionamento das escalas de ½, 3 e 6 milhas, setores cegos, desvio da linha de fé, manchas e funções.	
DOIS RADARES SOLAS, Cap. V, Reg. 12-h Todo navio AB igual ou sup. 10.000 t		
ECOBATÍMETRO SOLAS, Cap. V, Reg. 12-k Todo navio AB igual/sup. 500 t constante após 25/05/1980. Todo navio AB igual sup. 1.600 t constantes 25/05/80.	Checar o funcionamento, verificar os registros gráficos (papel) e digitais nas diversas escalas, utilizando os transdutores de vante e ré.	
AGULHA GIROSCÓPICA SOLAS, Cap. V, Reg. 12-d. Todo navio AB igual/sup. 500 t const. Após 09/84 SOLAS, Cap. Cap. V, Reg. 12-e. Todo navio AB igual/sup. 1600 t const. Antes 09/84	Checar o funcionamento, verificar se todas as repetidoras estão sincronizadas e tomar conhecimento do erro da agulha.	
AGULHA MAGNÉTICA SOLAS, Cap. V, Reg. 12-b Todo navio AB superior 150t	Checar o funcionamento, verificar iluminação disponível P/ leitura do rumo p/ timoneiro e curva de desvio atualizada.	
PUBLICAÇÕES NÁUTICAS SOLAS, Cap. V, Reg. 20 Todos os navios.	Checar existência das cartas náuticas que serão utilizadas na derrota, suas validades/correções e tábua de maré.	

EQUIPAMENTOS	VERIFICAÇÃO	RESULTADO
APARELHOS DE GOVERNO SOLAS, Cap. II-1, Reg. 29-1 SOLAS, Cap. V, Reg. 19-1 Todos os navios.	Checar o funcionamento das duas máquinas do leme funcionando independente, testar governo manual e elétrico, verificar tempo gasto para levar leme de 35° de um bordo para 35° de outro bordo, tempo máx. de 28 Seg. e leitura indicador passad. c/ régua máq. leme. Navegar com duas máquinas em funcionamento.	
INDICADOR ANGULO DO LEME SOLAS, Cap. V, Reg. 12-m AB igual/sup. 1600 t const. Antes 09/84 AB igual/sup. 500 t const. Após 01/09/84		
MÁQUINA PROPULSORA E MAQUINAS AUXILIARES SOLAS, Cap. II-1, Reg. 26 Todos os navios.	Verificar condições de funcionamento com o comandante, restrição informada deve ser analisada a fim de evitar perda de propulsão.	
MÁQUINA DE FUNDEIO/ SUSPENDER Todos os navios.	Verificar condição de funcionamento com o comandante, restrição informada deve ser analisada a fim de evitar problemas de fundeio e manobras com o ferro.	
DISPOSITIVO P/EMBARQUE DO PRÁTICO SOLAS, Cap. V, Reg. 17 Todos os navios.	Verificar se o dispositivo de embarque atende reg. solas, diagrama encontra-se afixado no passadiço, checar estado conservação da escada, iluminação, embarque/desembarque Prático supervisionado por um Oficial com meio de comunicação com passadiço.	
APITO RIPEAM, Reg. 33	Checar o funcionamento, operação manual e automático (cerração).	
ACOMODAÇÕES NORMAM-12	Verificar as acomodações p/ o Prático atende padrão disponível p/ Oficiais	

ANEXO 4-D

MARINHA DO BRASIL

CAPITANIA FLUVIAL DA AMAZÔNIA OCIDENTAL

PROGRAMA MÍNIMO DE ESTÁGIO DE QUALIFICAÇÃO DO PRATICANTE DE PRÁTICO

SINOPSE DO MÓDULO INICIAL DA ZP-02

DURAÇÃO: 20 HORAS

1 – PROPÓSITO GERAL

Permitir que os Praticantes de Práticos (PRP) conheçam os detalhes dos diversos trechos e terminais da Zona de Praticagem 02 - Itacoatiara – Tabatinga (ZP-02), na jurisdição da Capitania dos Portos da Amazônia Ocidental (CFAOC), das possibilidades e limitações dos rebocadores disponíveis, dos procedimentos administrativos da praticagem, das normas baixadas pela DPC, DHN, Capitania dos Portos e Administrações Portuárias, provendo a devida qualificação ao Praticante de Prático e habilitando-o para o exame à categoria de Prático na ZP-02.

O Programa será supervisionado pela Capitania Fluvial da Amazônia Ocidental (CFAOC) e realizado sob o rígido controle do Representante Único do Serviço de Praticagem (RUSP), utilizando-se de Práticos de todas as entidades existentes na Zona de Praticagem. Ao RUSP caberá enviar mensalmente à CFAOC as informações necessárias ao controle e acompanhamento do referido programa.

2 – DIRETRIZES GERAIS

2.1 – ESTRUTURAÇÃO DO MÓDULO

O Programa será dividido em duas fases, a saber:

I. Treinamento; e
II. Qualificação.

O módulo será realizado em Manaus, nas dependências de uma das Associações de Praticagem da jurisdição da CFAOC.

A Associação de Praticagem encarregada da execução do Programa deverá designar formalmente um ou mais práticos do seu quadro para atuar como Prático Instrutor no curso.

O material didático será fornecido pela Associação de Praticagem designada para execução do Estágio.

Na fase de treinamento, o praticante conhecerá os detalhes dos Terminais Portuários, dos rebocadores disponíveis, dos procedimentos administrativos da praticagem, das normas, bem como acompanhará as diversas manobras efetuadas nos diferentes trechos e terminais da área.

Durante a fase de qualificação, o Praticante de Prático deverá exercitar manobras nos diferentes berços dos complexos portuários, sempre acompanhado de um Prático qualificado. O Praticante de Prático ajustar—mencionada.

2.2 – TÉCNICAS DE ENSINO

O binômio ensino-aprendizagem deverá ser desenvolvido por meio de exemplos práticos passados pelo Prático Instrutor, dando mais credibilidade ao conhecimento adquirido e enfatizando às atividades na ZP-02. Deverá ser constituído de aulas expositivas com recursos audiovisuais com acompanhamento por meio de material didático fornecido.

3 – FREQUÊNCIA DAS AULAS

XVII) O comparecimento às aulas e demais atividades programadas é obrigatório; e

XVIII) O PRP deverá obter 90% de frequência no total de aulas ministradas no curso.

4 – AFERIÇÃO DO APROVEITAMENTO

A avaliação será aferida por meio de observações de desempenho do PRP conforme estabelecida no sumário do curso.

5 – APROVAÇÃO NO MÓDULO

Será considerado aprovado no módulo o PRP que obtiver a frequência mínima exigida e ter sido considerado, pelo Prático Instrutor do Curso, com desempenho satisfatório.

ANEXO 4-E

MARINHA DO BRASIL

CAPITANIA FLUVIAL DA AMAZÔNIA OCIDENTAL

PROGRAMA MÍNIMO DE ESTÁGIO DE QUALIFICAÇÃO DO PRATICANTE DE PRÁTICO

SUMÁRIO DO MÓDULO INICIAL DA ZP-02

1 - OBJETIVO GERAL

Permitir que o Praticante de Prático (PRP) possa ter um primeiro contato com a atividade, de modo a conhecer os principais trechos de navegação da zona de praticagem, os procedimentos e costumes adotados, as manobras nos diferentes terminais, o emprego de rebocadores e as normas vigentes, visando maximizar o seu aprendizado a bordo dos diferentes navios que frequentam a zona de praticagem.

2 - LISTA E PROPÓSITO DAS UNIDADES DE ENSINO

2.1 ESTRUTURA ORGANIZACIONAL DA PRATICAGEM.....0.5 HORA-AULA

2.1.1 Descrever a estrutura organizacional da empresa
2.1.2 Citar as atribuições da diretoria, conselho administrativo e conselho fiscal
2.1.3 Citar as atribuições da gerência
2.1.4 Mostrar o funcionamento do setor operacional

2.2 ESCALA DE RODÍZIO ÚNICA.....0.5 HORA-AULA

2.2.1 Mostrar as principais regras da ERU
2.2.2 Consulta à ERU publicada na internet

2.3 LIMITES DA ZONA DE PRATICAGEM .....0.5 HORA-AULA

2.3.1 Descrever os limites geográficos da zona de praticagem
2.3.2 Mostrar os trechos de toda a extensão da ZP-02.

2.4 DESCRIÇÃO DE PORTOS E TERMINAIS .....0.5 HORA-AULA

2.4.1 Descrever todos os portos e terminais existentes na zona de praticagem
2.4.2 Citar os calados máximos permitidos em cada terminal
2.4.3 Citar outras limitações operacionais existentes na ZP-02

2.5 PERÍODOS DE ESTIAGEM NOS RIOS DA AMAZÔNIA.....0.5 HORA-AULA

2.5.1 Períodos de estiagem
2.5.2 Descrever a influência das secas e cheias na navegação fluvial.

2.6 REGIME DE MARÉS E SUA INFLUÊNCIA .....0.5 HORA-AULA

2.6.1 Descrever o regime de marés nos principais portos e terminais
2.6.2 Citar os locais onde existem estações maregráficas
2.6.3 Mostrar a influência das marés nas manobras nos portos e terminais

2.7 MANOBRAS DE FUNDEIO .....0.5 HORA-AULA

2.7.1 Descrever como são realizadas as principais manobras de fundeio
2.7.2 Mostrar como realizar um fundeio em situação de emergência
2.7.3 Citar os principais cuidados a serem observados em um fundeio
2.7.4 Descrever os procedimentos para suspender de um fundeio

2.8 MANOBRAS DE EMERGÊNCIA.....0.5 HORA-AULA

2.8.1 Descrever as manobras de emergência mais comuns
2.8.2 Citar casos em que foram realizadas manobras de emergência

2.9 CRUZAMENTO DE NAVIOS .....0.5 HORA-AULA

2.9.1 Descrever como deve ser feito o cruzamento de navios
2.9.2 Citar os trechos onde o cruzamento ou ultrapassagem são proibidos
2.9.3 Citar os cuidados a serem tomados por ocasião de um cruzamento de ultrapassagem

2.10 COMUNICAÇÕES .....0.5 HORA-AULA

2.10.1 Citar os principais canais de comunicação entre navios
2.10.2 Descrever os procedimentos utilizados para comunicação entre navios (SMCP)
2.10.3 Citar os principais canais de comunicação entre navio e praticagem

2.11 MANOBRAS DE ATRACAÇÃO E DESATRACAÇÃO.....4.0 HORAS-AULA

2.11.1 Explicar detalhadamente o procedimento adotado nas manobras de atracação e desatracação em cada porto ou terminal da zona de praticagem, incluindo a aproximação, emprego de espias ou rebocadores e outros recursos existentes;
2.11.2 Citar a disponibilidade de rebocadores para auxílio nas manobras e as potências dos mesmos; e
2.11.3 Mostrar as técnicas de emprego do ferro no auxílio às manobras de atracação e desatracação

2.12 NAVEGAÇÃO NO TRECHO MANAUS/COARI.....4.0 HORAS-AULA

2.12.1 Descrever em detalhes a navegação no trecho

2.12.2 Citar os principais pontos conspícuos do trecho
2.12.3 Citar os principais perigos à navegação no trecho
2.12.4 Citar os principais faroletes, boias e outros auxílios à navegação
2.12.5 Citar os procedimentos especiais a serem adotados no trecho.

2.13 NAVEGAÇÃO NO TRECHO MANAUS/TABATINGA.....2.0 HORAS-AULA

2.13.1 Descrever em detalhes a navegação no trecho
2.13.2 Citar os principais pontos conspícuos do trecho
2.13.3 Citar os principais perigos à navegação no trecho
2.13.4 Citar os principais faroletes, boias e outros auxílios à navegação
2.13.5 Citar os procedimentos especiais a serem adotados no trecho, se houver

2.14 NAVEGAÇÃO NO TRECHO ITACOATIARA MANAUS.....4.0 HORAS-AULA

2.14.1 Descrever em detalhes a navegação no trecho
2.14.2 Citar os principais pontos conspícuos do trecho
2.14.3 Citar os principais perigos à navegação no trecho
2.14.4 Citar os principais faroletes, boias e outros auxílios à navegação
2.14.5 Citar os procedimentos especiais a serem adotados no trecho, se houver

2.15 NAVEGAÇÃO NO TRECHO MANAUS/ANAVILHANAS.....1.0 HORA-AULA

2.15.1 Descrever em detalhes a navegação no trecho
2.15.2 Citar os principais pontos conspícuos do trecho
2.15.3 Citar os principais perigos à navegação no trecho
2.15.4 Citar os principais faroletes, boias e outros auxílios à navegação
2.15.5 Citar os procedimentos especiais a serem adotados no trecho, se houver

3 - DIRETRIZES ESPECÍFICAS

3.1 As aulas serão ministradas pelos práticos instrutores para que os exemplos sobre o conteúdo de cada disciplina sejam o mais próximo possível da realidade.

3.2 Com o objetivo de tornar o binômio teoria x prática mais eficiente, os alunos deverão acompanhar as aulas com material didático que os permita visualizar, nas cartas náuticas, o que está sendo transmitido.

4 - CARGA HORÁRIA
20 HORAS-AULA

ANEXO 4-F

MARINHA DO BRASIL

CAPITANIA FLUVIAL DA AMAZÔNIA OCIDENTAL

PROGRAMA MÍNIMO DE ESTÁGIO DE QUALIFICAÇÃO DO PRATICANTE DE PRÁTICO

GUIA PARA ORGANIZAÇÃO DO PROGRAMA DE QUALIFICAÇÃO PARA PRATICANTE DE PRÁTICO

Nome do Praticante de Prático: _____

Início do Estágio: ____ / ____ / ____ Término do Estágio: _____ / _____ / _____

FASE DE TREINAMENTO			
ITEM	**DESCRIÇÃO**	**DATA TÉRMINO**	**CARIMBO E RUBRICA**
T-1	Visitar e conhecer as atividades do Setor de Segurança do Tráfego Aquaviário da Capitania dos Portos, no que se refere ao controle da atividade de praticagem, normas de tráfego e permanência e emprego de rebocadores.		
T-2	Ser aprovado no módulo inicial.		
T-3	Conhecer, detalhadamente, as silhuetas da costa, altos-fundos, ilhas, nomes de canais e estreitos, inclusive passagens normais de navegação e situações normativas em manobras de emergência referente à ZP-02.		
T-4	Conhecer, detalhadamente, nomes e locais dos portos, terminais e atracadouros localizados na ZP-02, suas manobras de atracação, inclusive as limitações em emergências e em condições meteorológicas desfavoráveis.		
T-5	Conhecer, detalhadamente, nomes e características de faróis e faroletes, seus alcances e arco de visibilidade, profundidades e o uso de equipamento de sondagem.		
T-6	Conhecer, detalhadamente, os pontos de referência que permitam efetuar a navegação, tanto visual como radar.		
T-7	Acompanhar manobras a bordo de rebocadores de forma a conhecer suas operações, limitações e precauções necessárias, bem como seus sistemas de comunicação (VHF, sonoro e visual).		
T-8	Observar singraduras e manobras de atracação, desatracação e fundeio, tanto no período diurno como no noturno, efetuadas		

	por práticos habilitados para cada um dos Terminais existentes.		

FASE DE QUALIFICAÇÃO			
ITEM	**DESCRIÇÃO**	**DATA TÉRMINO**	**CARIMBO E RUBRICA**
Q-1	Executar navegação de singradura nos trechos discriminados no item 1 do Anexo 4G, acompanhado por um prático habilitado.		
Q-2	Executar manobras de atracação e desatracação, acompanhado por prático habilitado, conforme discriminado no item 2 do Anexo 4G.		
TRECHO MANAUS-COARI			
ITEM	**DESCRIÇÃO**	**DATA TÉRMINO**	**CARIMBO E RUBRICA**
Q-3	Executar fainas especiais, acompanhado por prático habilitado, de acordo com as manobras previstas no programa de qualificação, item 3 do Anexo 4G.		

ANEXO 4-G

MARINHA DO BRASIL
CAPITANIA FLUVIAL DA AMAZÔNIA OCIDENTAL

PROGRAMA MÍNIMO DE ESTÁGIO DE QUALIFICAÇÃO DO PRATICANTE DE PRÁTICO

FASE DE TREINAMENTO/QUALIFICAÇÃO DA ZP-02

1 – Programa Mínimo de Singraduras a serem acompanhadas (A) ou realizadas (R):

Trecho		(A)	(R)	Quantidade total
A	Manaus-Coari	01	01	02
B	Coari-Manaus	01	01	02
C	Manaus-Tabatinga	01	-	01
D	Tabatinga-Manaus	01	-	01
E	Manaus-Itacoatiara	01	01	02
F	Itacoatiara-Manaus	01	01	02

2 – Programa Mínimo de Manobras (atracação e desatracação) a serem acompanhadas (A) ou realizadas (R):

Porto / Terminal		Atracação (A)	Desatracação (A)	Atracação (R)	Desatracação (R)
A	Terminal Chibatão externo	02	02	02	02
B	Terminal Chibatão interno	02	02	02	02
C	Terminal Superterminais externo	02	02	02	02
D	Terminal Superterminais interno	02	02	02	02
E	Terminal Moageira (Trigolar)	01	01	01	01
F	REAM – POF 01	01	01	01	01
G	REAM – POF 03	01	01	01	01
H	Terminal Aquaviário de Coari	02	02	02	02
I	Terminal de Cimento Vencemos	01	01	01	01
J	Terminal ATEM	02	02	02	02
K	Terminal Graneleiro da Hermasa I	01	01	01	01
L	Terminal Graneleiro da Hermasa II	01	01	01	01
M	Terminal Fluvial do Brasil S.A.	02	02	02	02
N	Terminal Portuário Novo Remanso - TGSA	02	02	02	02

3 – Manobras Especiais a serem acompanhadas (A) e realizadas (R):

Manobras especiais		(A)	(R)	Total
A	Fundeio após desatracação no rio Negro	01	01	02
B	Fundeio após desatracação no rio Solimões	01	01	02
C	Manobra de Fundeio rio Negro	01	01	02 (1 noturno)
D	Manobra de Fundeio no rio Solimões	01	01	02 (1 noturno)
E	Manobra de Fundeio no rio Amazonas	01	01	02 (1 noturno)

ANEXO 4-H

MARINHA DO BRASIL

CAPITANIA FLUVIAL DA AMAZÔNIA OCIDENTAL

PROGRAMA MÍNIMO DE ESTÁGIO DE QUALIFICAÇÃO DO PRATICANTE DE PRÁTICO (ZP-02)

QUADRO DE RESUMO MENSAL DE MANOBRAS/SINGRADURAS ACOMPANHADAS/REALIZADAS POR PRATICANTE DE PRÁTICO

NOME: _____

MÊS E ANO: _____ /_____

DATA HORA DE INÍCIO E TÉRMINO	LOCAL	TIPO DE FAINA	NAVIO	CALADO MÁXIMO	ACOMPANHADA (A) OU EXECUTADA (E)	PRÁTICO RESPONSÁVEL	NOTA FINAL

Assinatura do Prático Monitor **Assinatura do Praticante de Prático**

ANEXO 4-I

MARINHA DO BRASIL

CAPITANIA FLUVIAL DA AMAZÔNIA OCIDENTAL

PROGRAMA MÍNIMO DE ESTÁGIO DE QUALIFICAÇÃO DO PRATICANTE DE PRÁTICO

RELATÓRIO DE MANOBRA/SINGRADURA

DATA: _____ / ____ / _____

DADOS DA MANOBRA/SINGRADURA		
Nome do Praticante de Prático:		
Nome do Prático Responsável:		
Nome do Navio:	Calado Médio: _____ m	LOA: _____ m
Local:		
Data-hora do início: _____ _____ : _____	Data-hora do término: _____ _____ : _____	
Atracação ( ) Desatracação ( ) BE ( ) BB ( ) Fundear ( ) Suspender ( )		
Vento e Corrente:		
Rebocadores utilizados:		

FASES DA MANOBRA/SINGRADURA	**GRAU (0 a 10)**
Manobra da Embarcação/Navegação de Praticagem	
Manobra com Rebocadores/Navegação Radar	
Serviços de Amarração e Desamarração/Conhecimento de Contatos	
Conhecimento das ordens de manobra e conversação técnica em idioma inglês	
RESULTADO FINAL	

OCORRÊNCIAS DIVERSAS

( ) Manobra Acompanhada ( ) Manobra Executada pelo Praticante de Prático

_____ _____

Assinatura do Prático Responsável Assinatura do Praticante de Prático

ANEXO 4-J

MARINHA DO BRASIL

CAPITANIA FLUVIAL DA AMAZÔNIA OCIDENTAL

651

PORTARIA Nº ____/CFAOC, DE ___ DE _____ DE _____.

Estabelece as fainas de praticagem a serem realizadas nos trechos Manaus - Itacoatiara (AM); Manaus - Coari (AM) e Manaus - Tabatinga (AM), da Zona de Praticagem nº 2.

O CAPITÃO DOS PORTOS DA AMAZÔNIA OCIDENTAL, no uso das atribuições que lhe são conferidas pela Lei nº 9.537, de 11 de dezembro de 1997 (LESTA) e de acordo com as alíneas d, e e f do item 0224 das Normas da Autoridade Marítima para o Serviço de Praticagem - NORMAM-12/DPC, aprovada pela Portaria nº 78/DPC, de 15 de março de 2011, resolve:

Art. 1º Estabelecer as seguintes fainas de praticagem para o Exame de Habilitação para Prático, conforme abaixo:

1 - Trecho Manaus - Itacoatiara:

- Navegação de praticagem no trecho Manaus - Itacoatiara ou Itacoatiara - Manaus;
- Atracação ou desatracação no Terminal de Cargas “Superterminais ou Chibatão” (Serviço de amarração ou desamarração); e
- Ordens de manobra no idioma Inglês.

2 - Trecho Manaus - Coari:

- Navegação de praticagem no trecho Manaus - Coari ou Coari - Manaus;
- Atracação ou desatracação no Terminal Solimões - TA Coari. (Serviço de amarração ou desamarração);
- Atracação ou desatracação na Refinaria de Manaus (Serviço de amarração ou desamarração); e
- Ordens de manobra no idioma Inglês.

3 – Trecho Manaus - Tabatinga:

- Navegação de praticagem no trecho Manaus - Tabatinga ou Tabatinga - Manaus;

- Um fundeio ou suspender em Manaus ou Tabatinga; e
- Ordens de manobra no idioma Inglês.

Art. 2º Esta Portaria entra em vigor na presente data.

NOME
Posto
Capitão dos Portos

Distribuição: XXX.

ANEXO 4-K

MODELO DE PORTARIA DA BANCA EXAMINADORA

MARINHA DO BRASIL

XX/XX/XXX **CAPITANIA FLUVIAL DA AMAZÔNIA OCIDENTAL**
651

PORTARIA Nº ____/CFAOC, DE ___ DE _____ DE _____.

Designa a Banca Examinadora para Exame de Habilitação de Prático, nos trechos Manaus - Itacoatiara (AM); Manaus - Coari (AM) e Manaus - Tabatinga (AM), da Zona de Praticagem nº 2.

O CAPITÃO DOS PORTOS DA AMAZÔNIA OCIDENTAL, no uso das atribuições que lhe são conferidas pela Lei nº 9.537, de 11 de dezembro de 1997 (LESTA) e de acordo com as alíneas e e g, do item 0224 das Normas da Autoridade Marítima para o Serviço de Praticagem - NORMAM-12/DPC, aprovada pela Portaria nº 78/DPC, de 15 de março de 2011, resolve:

Art. 1º Designar o pessoal abaixo relacionado para compor a Banca Examinadora para o Exame de Habilitação para Prático, nos trechos Manaus - Itacoatiara (AM); Manaus - Coari (AM) e Manaus - Tabatinga (AM), da Zona de Praticagem nº 2:

- Posto, nome (Capitão dos Portos) – Presidente; e
- ____, _____ - Membro (Substituto).

Art. 2 º Serão avaliados os seguintes Praticantes de Práticos:

- nome completo dos Praticantes; e
- _____.

Art. 3º O exame de Habilitação para Prático consistirá das manobras estabelecidas na Portaria nº ___ /CFAOC, de __ de _____ de ____.

Art. 4º Esta Portaria entra em vigor na presente data.

NOME
Posto
Capitão dos Portos

Distribuição: XXX.

ANEXO 4-L

MARINHA DO BRASIL
CAPITANIA FLUVIAL DA AMAZÔNIA OCIDENTAL
Rua Frei José dos Inocentes, 36 - Centro
CEP: 69005-530 Manaus - AM
(92) 2123-4900 - secom@cfaoc.mar.mil.br

PLANO DE RECUPERAÇÃO DA HABILITAÇÃO

MAPA DE COMPROVAÇÃO DAS FAINAS DE PRATICAGEM REALIZADAS POR PRÁTICO SUSPENSO – ZP-02

Nome do Prático	N° de fainas realizadas	N° de fainas de praticagem como assistente	Validade Laudo médico	Documento que publicou afastamento	Férias no período

Obs: A recuperação da habilitação está condicionada ao cumprimento deste Plano, Conforme o item 2.41 da NORMAM-311/DPC, que deverá ser apresentado juntamente com os comprovantes de cada manobra, conforme Anexo 2-G da mesma.

_____

Diretor da Empresa de Praticagem da ZP-02

ANEXO 4-M

MARINHA DO BRASIL

CAPITANIA FLUVIAL PORTOS DA AMAZÔNIA OCIDENTAL

DECÁLOGO DE SEGURANÇA

1 – VIGIE O NAVIO E CARGA

É dever de todo Comandante zelar pela carga e adotar as medidas de precaução para a completa segurança do navio, bem como das atividades nele desenvolvidas, exercidas pela tripulação ou outras pessoas a bordo, sob pena prevista na Regulamentação da Lei do Tráfego Aquaviário e nas normas emitidas pela Autoridade Marítima. Toda a tripulação deverá cooperar na vigilância, em seu próprio interesse, comunicando ao Oficial de Quarto qualquer atividade suspeita.

2 – ILUMINE O NAVIO E SEU COSTADO

Mantenha o navio iluminado, principalmente o costado do lado do mar e convés toda a extensão, use refletores de grande potência. A má visibilidade dificulta a ação de fiscalização, constituindo-se em fator favorável às atividades ilícitas. Não se esqueça do preconizado pelas regras 2 e 30 do RIPEAM.

3 – ESTABELEÇA COMUNICAÇÕES PARA APOIO EXTERNO

Instale, sempre que possível, uma linha telefônica que seja de fácil acesso ao vigia ou tripulante de serviço. As Autoridades do Porto mantém um serviço permanente de combate à criminalidade. Peça auxílio pelo telefone.

Lembre-se ainda que a Capitania Fluvial da Amazônia Ocidental e suas OM subordinadas, a Praticagem e Manaus Rádio mantêm escuta permanente no canal 16 de VHF. Estas estações poderão encaminhar o pedido de auxílio às autoridades competentes.

4 – CONTROLE DOS ACESSOS AOS COMPARTIMENTOS DE CARGA E HABITÁVEIS

A Câmara do Comandante é um dos principais objetivos dos assaltantes que buscam dinheiro e as chaves mestra dos demais compartimentos habitáveis, para realizarem saques de objetos de valor de uso pessoal da tripulação e equipamentos náuticos existentes no passadiço. Os camarotes e demais compartimentos habitáveis devem ser mantidos trancados à chave, sempre que seus ocupantes encontrarem-se ausentes.

A carga só será, normalmente, objeto de roubo ou furto se os marginais tiverem conhecimento prévio do seu conteúdo, através de informações colhidas por pessoas inescrupulosas que têm acesso ao conhecimento de embarque, ou mesmo por contatos prévios da prostituição com os tripulantes. Procure estivar os containeres com cargas valiosas de forma a obstruir os seus tampões de acesso. Isole os meios de acesso ao navio, e também, os acessos às suas áreas internas, criando uma única via de entrada e saída pelo portaló, garantindo seu controle através do vigia ali postado.

5 – MANTENHA AS VIGIAS FECHADAS

Vigias abertas podem constituir-se em fácil acesso hábeis malfeitores: deixe-as fechadas com os grampos passados sempre que se ausentar. Procure manter, também, os

acessos às áreas internas trancados, garantindo o controle de entrada e saída por meio do vigia de portaló.

6 – NÃO DEIXE OBJETOS DE VALOR EXPOSTOS

Procure reduzir as oportunidades de roubo, removendo todos os equipamentos portáteis que não estejam em uso, para seus locais de guarda. Objetos de valor expostos estimulam a prática de furto por "oportunidade", guarde-os em local trancado e seguro.

7 – MANTENHA AS ESCADAS RECOLHIDAS

Nos fundeadouros e no porto, dificulte o acesso mantendo içadas as escadas de portaló e de quebra-peito. No porto, somente deixe arriada a escada de portaló pelo bordo do cais.

8 – EM CASO DE ASSALTO

I – Não hesite em soar o sinal de alarme geral do navio em caso de ameaça de assalto;

II – Procure manter iluminação adequada para ofuscar permanentemente os oponentes, no caso de tentativa de subida de estranhos pelo costado;

III – Dar o alarme, através de contato rádio VHF – Canal 16, para os navios das proximidades e para o sistema de escuta permanente das autoridades de terra (Capitania, Delegacia e Agências, Praticagem e Manaus Rádio). A eficácia de socorro pela Polícia Federal depende do alarme antecipado;

IV – Usar alarmes sonoros com apitos intermitentes e visuais como holofotes e sinalizadores náuticos;

V – Se adequado, para proteger as vidas de bordo, e sob inteira responsabilidade do Comandante use medidas para repelir a abordagem, como uso de holofotes de grande potência para ofuscamento dos agressores ou mesmo guarnecendo jatos d'água ou sinalizadores náuticos contra áreas de abordagem; e

VI – não realizar atos de heroísmo.

9 – MANTENHA OS VIGIAS CONTRATADOS SOB CONTROLE DO OFICIAL DE QUARTO

Exija um bom serviço dos vigias. Faça-os identificar todo o pessoal que entra e sai do navio. Recomende que a tripulação colabore com o controle. Não permita que o vigia se ausente do portaló, salvo se substituído por outro vigia ou tripulante.

10 – COMUNIQUE À POLÍCIA FEDERAL QUALQUER OCORRÊNCIA RELATIVA A FURTO, ROUBO OU ASSALTO

As ocorrências envolvendo roubo ou assalto, tanto de carga quanto de objetos do navio ou tripulantes, devem ser comunicadas à Polícia Federal para as providências legais pertinentes.

Essas informações possibilitarão, ainda, o estudo das medidas a serem adotadas para a prevenção e combate a esses crimes, contribuindo para garantia da segurança da tripulação e do navio.

ANEXO 4-N

MARINHA DO BRASIL

CAPITANIA FLUVIAL DA AMAZÔNIA OCIDENTAL

Nº_____/20____

SOLICITAÇÃO DE TROCA DE SERVIÇO ENTRE PRÁTICOS

NOME DO PRT SOLICITANTE/TRIGRAMA	DATA DETALHADA NA ERU	DATA DO EFETIVO SERVIÇO
	____/____/20___	____/____/20___
ASSINATURA		
NOME DO PRT SUBSTITUTO/TRIGRAMA	**DATA DETALHADA NA ERU**	**DATA DO EFETIVO SERVIÇO**
	____/____/20___	____/____/20___
ASSINATURA		

MOTIVO: _____

_____.

Manaus, AM, _____ de _____ de 20_____.

_____

RUSP

Representante Único do Serviço de Praticagem – ZP-02

Autorizo:

_____

CAPITÃO DOS PORTOS

OBS: Pedido de troca de Período de Escala ocorre quando dois Práticos que compõem a ERU de um determinado mês desejam alterar entre si os respectivos dias em Período de Escala. A solicitação deve obedecer o prazo de 48h de antecedência em relação ao dia/período da troca.

ANEXO 6-A

MARINHA DO BRASIL

CAPITANIA FLUVIAL DA AMAZÔNIA OCIDENTAL

DECLARAÇÃO DE DADOS PESSOAIS

Eu,_____,

(nome completo)

inscrito(a) no CPF sob o nº _____, venho por meio desta, declarar, a fim de receber informações sobre a embarcação de minha propriedade, referente ao processo de inscrição de embarcação, transferência de propriedade, transferência de jurisdição, emissão de 2ª Via ou alteração de dados da embarcação inscrita, que tramita na Capitania Fluvial da Amazônia Ocidental (CFAOC), os contatos de correio eletrônico (e-mail) e número de telefone/celular particular abaixo indicados:

1 - E-mail particular: _____

2 - E-mail de parente ou vizinho, se houver: _____

3 - Telefone/celular particular: _____

4 - Telefone/celular particular de parente ou vizinho, se houver: _____

Declaro assumir a total responsabilidade sobre a veracidade das informações contidas neste documento.

Local e data.

Manaus, em ____ de _____ de 20___.

_____

(Nome do Proponente / Assinatura conforme documento de identidade)

ANEXO 7-A

MARINHA DO BRASIL

CAPITANIA FLUVIAL DA AMAZÔNIA OCIDENTAL

INSTRUÇÕES SOBRE A LOCALIZAÇÃO DO MATERIAL DE SALVATAGEM E DEMONSTRAÇÃO DE USO DE COLETES SALVA-VIDAS AOS PASSAGEIROS

BOM DIA! BOA TARDE! ou BOA NOITE!

SENHORAS E SENHORES PASSAGEIROS, BEM-VINDOS A BORDO, NOSSA CHEGADA NO PORTO DE (DESTINO FINAL) ESTÁ PREVISTA PARA ÀS _____ HORAS DO DIA _____.

EM CUMPRIMENTO ÀS NORMAS DA CAPITANIA FLUVIAL DA AMAZÔNIA OCIDENTAL, SERÃO PRESTADAS AGORA INFORMAÇÕES SOBRE A LOCALIZAÇÃO E USO DO MATERIAL DE SALVATAGEM:

1. “ESTA EMBARCAÇÃO ESTÁ EQUIPADA COM O SEGUINTE MATERIAL DE SALVATAGEM (DESCREVER O MATERIAL E A LOCALIZAÇÃO)”.

2. “REALIZAREMOS AGORA UMA DEMONSTRAÇÃO SOBRE O USO DO COLETE SALVA-VIDAS”.

AO ENTRAR NA EMBARCAÇÃO VERIFIQUE SE EXISTE A PLACA COM O Nº DE PASSAGEIROS PERMITIDO E O TELEFONE DA CAPITANIA DOS PORTOS. OBSERVE SE OS COLETES ESTÃO EM LOCAL DE FÁCIL ACESSO E EM BOM ESTADO DE CONSERVAÇÃO.

O COLETE TRAZ DUAS FITAS DE FIXAÇÃO:

A FITA SUPERIOR, QUE DEVE SER FIRMEMENTE AMARRADA, UMA Á OUTRA, E A INFERIOR, QUE APÓS CONTORNAR O CORPO DO PASSAGEIRO, DEVERÁ SER BEM AMARRADA À CINTURA. O COLETE DISPÕE, TAMBÉM, DE UM APITO PARA FACILITAR A LOCALIZAÇÃO DO NÁUFRAGO.

EM CASO DE ABANDONO DA EMBARCAÇÃO, SEGURE O COLETE COM FIRMEZA COM A MÃO DIREITA, LEVE A MÃO ESQUERDA AO NARIZ, JUNTE AS PERNAS E SALTE!

EM CASO DE ACIDENTE, MANTENHA A CALMA E SIGA AS INSTRUÇÕES DA TRIPULAÇÃO.

MUITO OBRIGADO E BOA VIAGEM.

ESTA TRIPULAÇÃO ESTÁ ÀS SUAS ORDENS.

ANEXO 7-B

MARINHA DO BRASIL
CAPITANIA FLUVIAL DA AMAZÔNIA OCIDENTAL
Rua Frei José dos Inocentes, 36 - Centro
CEP: 69005-530 Manaus - AM
(92) 2123-4900 - secom@cfaoc.mar.mil.br

LISTA DE EMBARCAÇÃO DE ASSOCIADOS DAS MARINAS, CLUBES E ENTIDADES DESPORTIVAS NÁUTICAS

Nome da EMB	Número de Inscrição (EMB)	Nome do Proprietário	CPF/CNPJ (Proprietário)	Número de Contato (Proprietário)	Nº CHA/CIR (Proprietário)

Obs.: Na coluna do Nº de Inscrição da Embarcação (EMB), do Nº da CHA (Carteira de Habilitação de Amadores)/CIR (Caderneta de Inscrição e Registro), caso possua alguma pendência, deve ser preenchido com A/S (A Ser), informando os óbices e as medidas em andamento para regularização destas.

_____

(Nome/Assinatura conforme documento de identidade do Titular da Marina, Clube ou Entidade Desportiva Náutica)